Katalog: 1102001.6301040
ISSN 0852-5048

KECAMATAN Bati-Bati DALAM ANGKA 2024

Volume 34

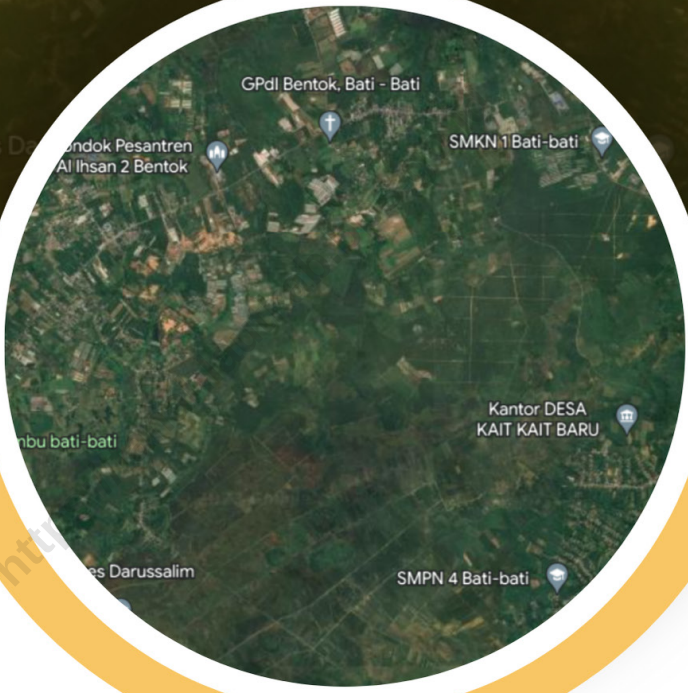

BADAN PUSAT STATISTIK
KABUPATEN TANAH LAUT

https://tanahlautkab.bps.go.id

Katalog: 1102001.6301040
ISSN 0852-5048

KECAMATAN Bati-Bati DALAM ANGKA 2024

Volume 34

https://tanahlautkab.bps.go.id

BADAN PUSAT STATISTIK
KABUPATEN TANAH LAUT

KECAMATAN BATI-BATI DALAM ANGKA
2024
Volume 34, 2024

Katalog: 1102001.6301040
ISSN: 0852-5048
Nomor Publikasi: 63010.24015

Ukuran Buku: 14,8 cm x 21 cm
Jumlah Halaman: xxvi+126 halaman

Penyusun Naskah:
BPS Kabupaten Tanah Laut

Penyunting:
BPS Kabupaten Tanah Laut

Pembuat Kover:
BPS Kabupaten Tanah Laut

Penerbit
©BPS Kabupaten Tanah Laut

Sumber Ilustrasi: Google Earth
Dilarang mereproduksi dan/atau menggandakan sebagian atau seluruh isi buku ini untuk tujuan komersial tanpa izin tertulis dari Badan Pusat Statistik Kabupaten Tanah Laut.

https://tanahlautkab.bps.go.id

ISSN 0852-5048

TIM PENYUSUN

KECAMATAN BATI-BATI DALAM ANGKA 2024

Volume 34, 2024

Pengarah
Siswo Widjanarko

Penanggung Jawab
Nurul Ni'mah

Penyunting
Nurul Ni'mah

Pengolah Data dan Penulis Naskah
Ardianto S. • Abdul Hair • Desy Rivina Maulita
Nurul Ni'mah • Surhaliza Aprilianti

Penata Letak
Nurul Ni'mah

Infografis
Nurul Ni'mah

Kover
Surhaliza Aprilianti

https://kotalautkab.bps.go.id

https://tanahlautkab.bps.go.id

KONTRIBUTOR DATA

1. Kementerian Agama
2. Kementerian Pendidikan dan Kebudayaan
3. Badan Pusat Statistik
4. Sekretariat Daerah Kabupaten Tanah Laut
5. Dinas Kependudukan dan Pencatatan Sipil Kabupaten Tanah Laut
6. Dinas Tanaman Pangan, Hortikultura, dan Perkebunan
7. Pengadilan Agama Pelaihari
8. Dinas Peternakan dan Kesehatan Hewan
9. Badan Keuangan Daerah Unit Pelayanan Pendapatan Daerah Pelaihari
10. Kantor Kecamatan
11. Kantor Desa
12. Kepolisian Resor Tanah Laut
13. Kepolisian Sektor
14. Dinas Pengendalian Penduduk, Keluarga Berencana, Pemberdayaan Perempuan dan Perlindungan Anak Kabupaten Tanah Laut

https://tanahlautkab.bps.go.id

https://tanahlautkab.bps.go.id

PETA WILAYAH KECAMATAN BATI-BATI

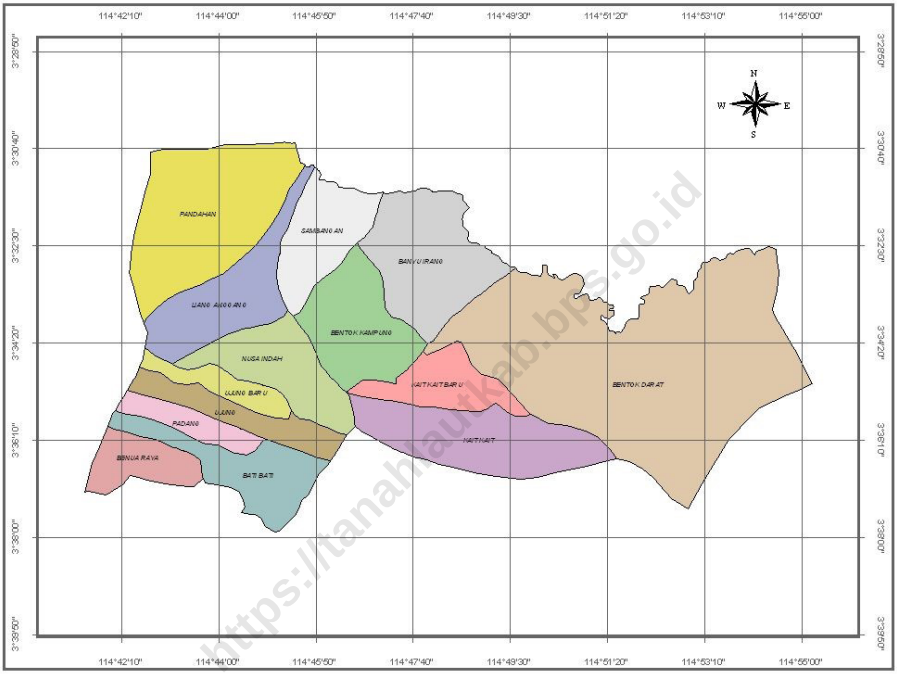

https://tanahbautkab.bps.go.id

https://tanahlautkab.bps.go.id

KEPALA BPS KABUPATEN TANAH LAUT

SISWO WIDJANARKO

https://tanahlautkab.bps.go.id

KATA PENGANTAR

Puji syukur kami panjatkan ke hadirat Tuhan Yang Maha Esa atas segala rahmat dan karunia-Nya sehingga publikasi "Kecamatan Bati-Bati dalam Angka 2024" ini dapat diselesaikan dengan baik. Publikasi ini merupakan hasil kerja keras dan kerjasama dari berbagai pihak yang telah memberikan kontribusi dalam pengumpulan, pengolahan, dan penyajian data.

Publikasi ini menyajikan berbagai macam data dan informasi mengenai keadaan geografis, demografi, sosial, dan ekonomi di Kecamatan Bati-Bati. Data yang disajikan dalam publikasi ini diperoleh dari berbagai sumber, termasuk survei yang dilakukan oleh Badan Pusat Statistik (BPS) serta kompilasi data dari instansi pemerintah.

Kami berharap publikasi ini dapat menjadi sumber informasi yang bermanfaat bagi para pengguna data, baik dari kalangan pemerintah, akademisi, maupun masyarakat umum. Kami juga menyadari bahwa publikasi ini masih memiliki kekurangan dan keterbatasan. Oleh karena itu, kami sangat mengharapkan masukan dan saran yang konstruktif untuk perbaikan di masa mendatang.

Akhir kata, kami mengucapkan terima kasih kepada semua pihak yang telah membantu dalam penyusunan publikasi ini. Semoga publikasi ini dapat memberikan manfaat yang sebesar-besarnya bagi pembangunan dan kesejahteraan masyarakat di Kecamatan Bati-Bati.

Pelaihari , September 2024
Kepala BPS
Kabupaten Tanah Laut

Siswo Widjanarko

https://tanahlautkab.bps.go.id

https://tanahlautkab.bps.go.id

ISSN 0852-5048

DAFTAR ISI

KECAMATAN BATI-BATI DALAM ANGKA
2024
Volume 34, 2024

Halaman

Kata Pengantar xi
Daftar Isi xiii
Daftar Tabel xv
Daftar Gambar xxi
Penjelasan Umum xxiii
Daftar Singkatan xxv
1. Geografi 1
2. Pemerintahan 11
3. Penduduk 35
4. Sosial dan Kesejahteraan Rakyat 43
5. Pertanian 81
6. Pariwisata, Transportasi, dan Komunikasi 101
7. Perbankan, Koperasi, dan Perdagangan 113
Daftar Pustaka 125

https://tanahlautkab.bps.go.id

https://tanahlautkab.bps.go.id

DAFTAR TABEL

Tabel Halaman

1. GEOGRAFI

1.1 KEADAAN GEOGRAFI

1.1.1 Luas Daerah Menurut Desa/Kelurahan di Kecamatan Bati-Bati, 2023 8

1.1.2 Jarak ke Ibukota Kecamatan dan Ibukota Kabupaten/Kota Menurut Desa/Kelurahan di Kecamatan Bati-Bati (km), 2023 9

2. PEMERINTAHAN

2.1 WILAYAH ADMINISTRATIF

2.1.1 Jumlah Rukun Warga (RW) dan Rukun Tetangga (RT) Menurut Desa/Kelurahan di Kecamatan Bati-Bati, 2023 16

2.1.2 Nama Camat/Kepala Wilayah Kecamatan Bati-Bati, 2000-2023 17

2.1.3 Nama Kepala Desa di Kecamatan Bati-Bati, 2023 18

2.1.4 Jumlah Anggota Badan Permusyawaratan Desa (BPD) di Kecamatan Bati-Bati, 2023 19

2.1.5 Nama Ketua RT di Desa Benua Raya, 2023 20

2.1.6 Nama Ketua RT di Desa Bati-Bati, 2023 21

2.1.7 Nama Ketua RT di Desa Padang, 2023 22

2.1.8 Nama Ketua RT di Desa Ujung, 2023 23

2.1.9 Nama Ketua RT di Desa Ujung Baru, 2023 24

2.1.10 Nama Ketua RT di Desa Nusa Indah, 2023 25

2.1.11 Nama Ketua RT di Desa Kait-Kait, 2023 26

2.1.12 Nama Ketua RT di Desa Kait-Kait Baru, 2023 27

2.1.13 Nama Ketua RT di Desa Bentok Darat, 2023 28

2.1.14 Nama Ketua RT di Desa Banyu Irang, 2023 29

2.1.15 Nama Ketua RT di Desa Bentok Kampung, 2023 30

2.1.16 Nama Ketua RT di Desa Sambangan, 2023 31

2.1.17 Nama Ketua RT di Desa Liang Anggang, 2023 32

2.1.18 Nama Ketua RT di Desa Pandahan, 2023 33

https://tanahbumbukab.bps.go.id

Tabel Halaman

3. PENDUDUK

3.1 Penduduk, Distribusi Persentase Penduduk, Kepadatan Penduduk, Rasio Jenis Kelamin Penduduk Menurut Desa/Kelurahan di Kecamatan Bati-Bati, 2023 40

4. SOSIAL DAN KESEJAHTERAAN RAKYAT

4.1 PENDIDIKAN

4.1.1 Banyaknya Desa[1]/Kelurahan yang Memiliki Fasilitas Sekolah Menurut Tingkat Pendidikan di Kecamatan Bati–Bati, 2021–2023... 52

4.1.2 Jumlah Sekolah Menurut Tingkat Pendidikan di Kecamatan Bati–Bati, 2023/2024 53

4.1.3 Jumlah Guru Menurut Tingkat Pendidikan di Kecamatan Bati–Bati, 2023/2024..... 54

4.1.4 Jumlah Murid Menurut Tingkat Pendidikan di Kecamatan Bati–Bati, 2023/2024 55

4.2 KESEHATAN

4.2.1 Banyaknya Desa[1]/Kelurahan yang Memiliki Sarana Kesehatan Menurut Jenis Sarana Kesehatan di Kecamatan Bati–Bati, 2021–2023 56

4.2.2 Banyaknya Warga Penderita Kekurangan Gizi Menurut Desa/Kelurahan di Kecamatan Bati–Bati, 2023..... 57

4.2.3 Jumlah Rumah Sakit Umum, Rumah Sakit Khusus, dan Puskesmas Menurut Desa/Kelurahan di Kecamatan Bati–Bati, 2023..... 58

4.2.4 Banyaknya Tenaga Kesehatan Menurut Desa/Kelurahan di Kecamatan Bati–Bati, 2023 59

4.2.5 Banyaknya Wanita Usia Subur (WUS) 15–49 Tahun, Pasangan Usia Subur (PUS) Dan Peserta Keluarga Berencana (KB) Menurut Desa/kelurahan di Kecamatan Bati–Bati, 2023 60

4.3 PERUMAHAN DAN LINGKUNGAN

4.3.1 Banyaknya Desa[1]/Kelurahan Menurut Sumber Air Minum Sebagian Besar Keluarga di Kecamatan Bati–Bati, 2021–2023 61

https://tanahbumkab.bpn.go.id

Tabel Halaman

4.3.2 Banyaknya Keluarga Menurut Desa/Kelurahan dan Jenis Pengguna Listrik di Kecamatan Bati–Bati, 2023 62

4.3.3 Banyaknya Desa/Kelurahan Menurut Sumber Penerangan Jalan Utama Desa/Kelurahan di Kecamatan Bati–Bati, 2021–2023 63

4.3.4 Banyaknya Desa/Kelurahan Menurut Penggunaan Fasilitas Tempat Buang Air Besar Sebagian Besar Keluarga di Kecamatan Bati–Bati, 2021–2023 64

4.3.5 Banyaknya Desa/Kelurahan Menurut Jenis Bahan Bakar untuk Memasak yang Digunakan Sebagian Besar Keluarga di Kecamatan Bati–Bati, 2023 65

4.4 AGAMA DAN SOSIAL LAINNYA

4.4.1 Jumlah Tempat Peribadatan Menurut Desa/Kelurahan di Kecamatan Bati–Bati, 2023 66

4.4.2 Banyaknya Kejadian Bencana Alam Menurut Desa/Kelurahan dan Jenis Bencana Alam di Kecamatan Bati–Bati, 2023 67

4.4.3 Banyaknya Korban Jiwa Akibat Bencana Alam Menurut Desa/Kelurahan dan Jenis Bencana Alam di Kecamatan Bati–Bati, 2023 .. 70

4.4.4 Keberadaan Fasilitas/Upaya Antisipasi/Mitigasi Bencana Alam Menurut Desa/Kelurahan di Kecamatan Bati–Bati, 2023..... 73

4.4.5 Banyaknya Desa/Kelurahan yang Memiliki Kelompok Kegiatan Olahraga Menurut Jenis Olahraga dan Ketersedian Fasilitas/Lapangan Olahraga di Kecamatan Bati–Bati, 2023..... 75

4.4.6 Banyaknya Perkara Kejahatan/Pelanggaran yang Dilaporkan ke Kepolisian dan yang Diselesaikan di Kecamatan Bati–Bati, 2023..... 76

4.4.7 Jumlah Pondok Pesantren, Jumlah Santri dan Guru/Kyai Menurut Desa/Kelurahan di Kecamatan Bati–Bati, 2023 77

4.4.8 Jumlah Penduduk Menurut Desa/Kelurahan dan Agama yang Dianut di Kecamatan Bati–Bati, 2023 78

4.4.9 Banyaknya Nikah, Talak, Cerai, dan Rujuk Menurut Desa/Kelurahan di Kecamatan Bati–Bati, 2023 79

4.4.10 Banyaknya Nikah, Talak, Cerai, dan Rujuk Menurut Bulan di Kecamatan Bati–Bati, 2023 80

https://tanahbumbukab.bps.go.id

Tabel Halaman

5. PERTANIAN

5.1 Luas Panen Tanaman Sayuran dan Buah-buahan Semusim Menurut Jenis Tanaman di Kecamatan Bati-Bati (ha), 2020–2023 88

5.2 Produksi Tanaman Sayuran dan Buah-buahan Semusim Menurut Jenis Tanaman di Kecamatan Bati-Bati (kuintal), 2020–2023 89

5.3 Luas Panen Tanaman Biofarmaka Menurut Jenis Tanaman di Kecamatan Bati-Bati (m^2), 2020–2023 90

5.4 Produksi Tanaman Biofarmaka Menurut Jenis Tanaman di Kecamatan Bati-Bati (kg), 2020–2023 91

5.5 Luas Panen Tanaman Hias Menurut Jenis Tanaman di Kecamatan Bati-Bati (m^2), 2020–2023 92

5.6 Produksi Tanaman Hias Menurut Jenis Tanaman di Kecamatan Bati-Bati (tangkai), 2020–2023 93

5.7 Produksi Buah-buahan dan Sayuran Tahunan Menurut Jenis Tanaman di Kecamatan Bati-Bati (kuintal), 2020–2023 94

5.8 Luas Areal Tanaman Perkebunan Menurut Jenis Tanaman di Kecamatan Bati-Bati (ha), 2020–2023 95

5.9 Produksi Tanaman Perkebunan Menurut Jenis Tanaman di Kecamatan Bati-Bati (ton), 2020–2023 96

5.10 Populasi Unggas Menurut Jenisnya di Kecamatan Bati-Bati (ekor), 2020–2023 97

5.11 Produksi Daging Ternak Unggas di Kecamatan Bati-Bati (kg), 2020–2023 98

5.12 Populasi Ternak Besar dan Kecil Menurut Jenisnya di Kecamatan Bati-Bati (ekor), 2020–2023 99

6. PARIWISATA, TRANSPORTASI, DAN KOMUNIKASI

6.1 PARIWISATA

6.1.1 Jumlah Sarana Akomodasi Menurut Desa/Kelurahan dan Jenis Akomodasi di Kecamatan Bati-Bati, 2023 106

https://batilaut.kab.bps.go.id

Tabel Halaman

6.2 TRANSPORTASI

6.2.1 Prasarana dan Sarana Transportasi Antar Desa/Kelurahan Menurut Desa/Kelurahan di Kecamatan Bati-Bati, 2023 107

6.2.2 Banyaknya Kendaraan Bermotor di Kecamatan Bati-Bati, 2021–2023 109

6.3 KOMUNIKASI

6.3.1 Keberadaan Kantor Pos/Pos Pembantu/Rumah Pos, Pos Keliling, dan Perusahaan/Agen Jasa Ekspedisi Swasta Menurut Desa/Kelurahan di Kecamatan Bati-Bati, 2023..... 110

6.3.2 Jumlah Menara Telepon Seluler dan Operator Layanan Komunikasi Telepon Seluler Menurut Desa/Kelurahan di Kecamatan Bati-Bati, 2023 111

6.3.3 Kekuatan Sinyal Telepon Seluler dan Jenis Sinyal Internet Telepon Seluler Menurut Desa/Kelurahan di Kecamatan Bati-Bati, 2023..... 112

7. PERBANKAN, KOPERASI, DAN PERDAGANGAN

7.1 Banyaknya Sarana Lembaga Keuangan Bank Menurut Desa/Kelurahan dan Jenis Bank di Kecamatan Bati-Bati, 2023 120

7.2 Banyaknya Koperasi Aktif Menurut Menurut Desa/Kelurahan dan Jenis Koperasi di Kecamatan Bati-Bati, 2023..... 121

7.3 Banyaknya Sarana Perdagangan Menurut Desa/Kelurahan dan Jenis Sarana Perdagangan di Kecamatan Bati-Bati, 2023 123

https://tanahbumbukab.bps.go.id

https://tanahlautkab.bps.go.id

DAFTAR GAMBAR

Gambar Halaman

1.1 Persentase Luas Desa/Kelurahan terhadap Luas Kecamatan di Kecamatan Bati-Bati (persen), 2023 6

1.2 Jarak ke Ibukota Kecamatan Menurut Desa/Kelurahan di Kecamatan Bati-Bati (km), 2023 7

https://tanahlautkab.bps.go.id

https://tanahlautkab.bps.go.id

PENJELASAN UMUM

Tanda-tanda, satuan-satuan, dan lain-lainnya yang digunakan dalam publikasi ini adalah sebagai berikut:

1. TANDA-TANDA

Data tidak tersedia	:	...
Tidak ada atau nol	:	-
Data dapat diabaikan	:	~0
Tanda decimal	:	,
Data tidak dapat ditampilkan	:	NA
Angka estimasi	:	e
Angka diperbaiki	:	r
Angka sementara	:	*
Angka sangat sementara	:	**
Angka sangat sangat sementara	:	***

2. SATUAN

barel	:	158,99 liter = 1/6,2898 m^3
hektare (ha)	:	10.000 m^2
kilometer (km)	:	1.000 meter (m)
knot	:	1,8523 km/jam
kuintal	:	100 kg
KWh	:	1.000 Watt *hour*
MWh	:	1.000 KWh
liter (untuk beras)	:	0,80 kg
MMSCF	:	1/35,3 m^3
metrik ton (m.ton)	:	0,98421 long ton = 1.000 kg
ons	:	28,31 gram
ton	:	1.000 kg

Satuan lain: buah, dus, butir, helai/lembar, kaleng, batang, pulsa, ton kilometer (ton-km), jam, menit, persen (%).

Perbedaan angka di belakang koma disebabkan oleh pembulatan angka.

https://tanahlautkab.bps.go.id

https://tanahlautkab.bps.go.id

DAFTAR SINGKATAN

SI	:	Stasiun Iklim
SMPK	:	Stasiun Meterologi Pertanian Khusus
t.t	:	Tempat tidur
BCG	:	Bacillus Calmette Guerin
DPT	:	Difteri, Pertusis, Tetanus
TT	:	Tetanus Toxoid
IOT	:	Industri Obat Tradisional
IKOT	:	Industri Kecil Obat Tradisional
Alkes	:	Alat kesehatan
PKRT	:	Perbekalan Kesehatan Rumah tangga
Kompl	:	Komplemen
IRTP	:	Industri Pangan Produksi Rumah Tangga
GFK	:	Gudang Farmasi Kab/Kota
RB	:	Rumah Bersalin
Pustu	:	Puskesmas pembantu
BP	:	Balai Pengobatan
TPS	:	Tempat Pembuangan Sampah Sementara
Jamkesmas	:	Jaminan kesehatan masyarakat miskin
PJKMU	:	Program Jaminan Kesehatan Masyarakat Umum
SIUP	:	Surat Izin Usaha Perdagangan
TDP	:	Tanda Daftar Perusahaan
API	:	Angka Pengenal Importir

https://sorlautkab.bps.go.id

https://tanahlautkab.bps.go.id

BAB 1
GEOGRAFI

https://tulangbawangkab.bps.go.id

https://tanahlautkab.bps.go.id

PENJELASAN TEKNIS

1. Secara astronomis, Kecamatan Bati-Bati terletak antara 114,691º– 114,92º Bujur Timur, 3,51086º–3,6318º Lintang Selatan

2. Luas wilayah Kecamatan Bati-Bati adalah 234,25 km^2 atau 6,10 persen dari luas wilayah Kabupaten Tanah Laut (Berdasarkan Data Sekretariat Daerah Kabupaten Tanah Laut dan Peraturan Menteri Dalam Negeri Nomor 100.1-6117 Tahun 2022 tanggal 9 November 2022).

3. Kecamatan Bati-Bati terdiri dari 14 desa, yaitu:
   - Benua Raya
   - Bati-Bati
   - Padang
   - Ujung
   - Ujung Baru
   - Nusa Indah
   - Kait-Kait
   - Kait-Kait Baru
   - Bentok Darat
   - Banyu Irang
   - Bentok Kampung
   - Sambangan
   - Liang Anggang
   - Pandahan

https://tanahlautkab.bps.go.id

https://tanahlautkab.bps.go.id

ULASAN

Kecamatan Bati-Bati adalah bagian dari wilayah Kabupaten Tanah Laut, terletak pada :

114,691º– 114,92º Bujur Timur
3,51086º–3,6318º Lintang Selatan

Dengan batas-batas :

Sebelah Utara	: Kota Banjarbaru
Sebelah Timur	: Kabupaten Banjar, Kecamatan Bajuin
Sebelah Barat	: Kecamatan Kurau, Kecamatan Bumi Makmur
Sebelah Selatan	: Kecamatan Tambang Ulang

Tinggi dari permukaan laut	: 25 meter
Luas Wilayah	: 234,25 km^2
Jumlah Desa	: 14 Desa

https://tanahlautkab.bps.go.id

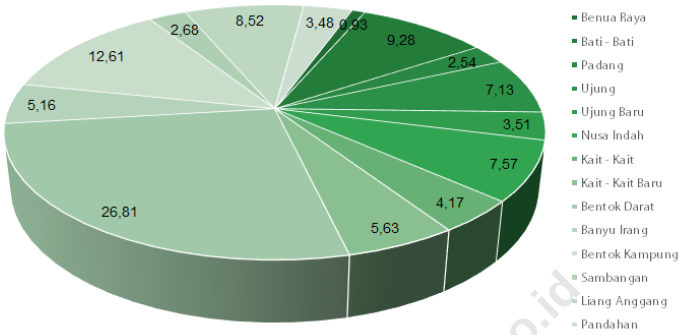

Sumber : Sekretariat Daerah Kabupaten Tanah Laut

Gambar 1.1 Persentase Luas Desa/Kelurahan terhadap Luas Kecamatan di Kecamatan Bati-Bati (persen), 2023

https://tanahlautkab.bps.go.id

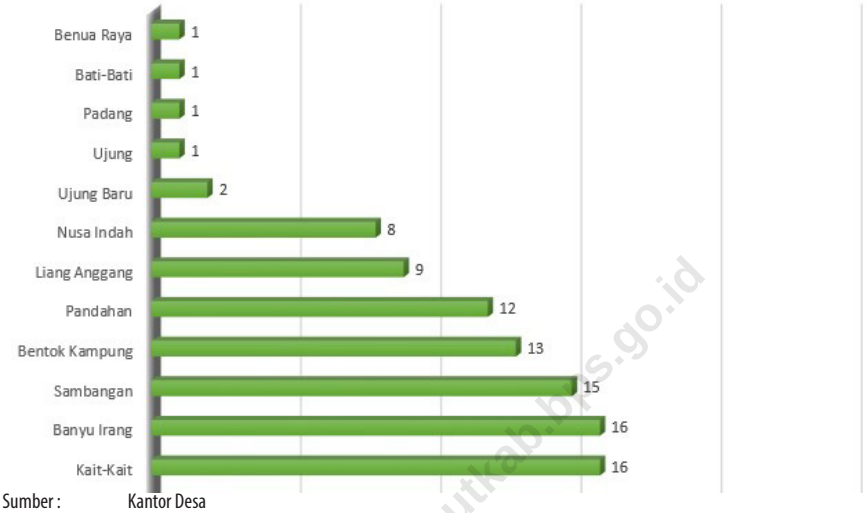

Gambar 1.2 **Jarak ke Ibukota Kecamatan Menurut Desa/Kelurahan di Kecamatan Bati-Bati (km), 2023**

https://kotalaut kab.bps.go.id

1.1 KEADAAN GEOGRAFI

Tabel 1.1.1 Luas Daerah Menurut Desa/Kelurahan di Kecamatan Bati-Bati, 2023

Desa/Kelurahan	Luas (km^2)	Persentase terhadap Luas Kecamatan
(1)	(2)	(3)
Benua Raya	2,18	0,93
Bati-Bati	21,73	9,28
Padang	5,95	2,54
Ujung	16,70	7,13
Ujung Baru	8,22	3,51
Nusa Indah	17,73	7,57
Kait-Kait	9,77	4,17
Kait-Kait Baru	13,18	5,63
Bentok Darat	62,79	26,81
Banyu Irang	12,09	5,16
Bentok Kampung	29,53	12,61
Sambangan	6,29	2,68
Liang Anggang	19,95	8,52
Pandahan	8,15	3,48
Bati-Bati	**234,25**	**100,00**

Sumber: Sekretariat Daerah Kabupaten Tanah Laut

https://tanahlautkab.bps.go.id

Tabel 1.1.2 Jarak ke Ibukota Kecamatan dan Ibukota Kabupaten/Kota Menurut Desa/Kelurahan di Kecamatan Bati-Bati (km), 2023

Desa/Kelurahan	Jarak ke Ibukota Kecamatan (km)	Jarak ke Ibukota Kabupaten/ Kota (km)
(1)	(2)	(3)
Benua Raya	1	25
Bati-Bati	1	26
Padang	1	25
Ujung	1	28
Ujung Baru	2	30
Nusa Indah	8	35
Kait-Kait	16	38
Kait-Kait Baru	23	32
Bentok Darat	25	37
Banyu Irang	16	49
Bentok Kampung	13	36
Sambangan	15	35
Liang Anggang	9	34
Pandahan	**12**	**39**

Sumber: Kantor Desa

https://tanahlautkab.bps.go.id

https://tanahlautkab.bps.go.id

BAB 2
PEMERINTAHAN

https://talaudkab.bps.go.id

https://tanahlautkab.bps.go.id

PENJELASAN TEKNIS

1. Desa adalah satuan wilayah yang ditempati oleh sejumlah penduduk sebagai kesatuan masyarakat termasuk di dalamnya kesatuan masyarakat hukum yang mempunyai organisasi pemerintahan terendah dan langsung di bawah camat serta berhak menyelenggarakan rumah tangga sendiri dalam ikatan negara kesatuan Republik Indonesia (RI). Ciri utama desa adalah kepala desanya dipilih oleh masyarakat setempat.

2. Kelurahan adalah satuan wilayah yang ditempati oleh sejumlah penduduk yang mempunyai organisasi pemerintahan terendah langsung di bawah camat dan tidak berhak menyelenggarakan rumah tangga sendiri. Ciri utama kelurahan adalah kepala kelurahannya (lurah) sebagai pegawai negeri dan tidak dipilih oleh rakyat.

3. Badan Permusyawaratan Desa atau yang disebut dengan nama lain BPD adalah lembaga yang melaksanakan fungsi pemerintahan yang anggotanya merupakan wakil dari penduduk desa berdasarkan keterwakilan wilayah dan ditetapkan secara demokratis.

4. Di desa dibentuk lembaga kemasyarakatan desa, seperti rukun tetangga, rukun warga, pembinaan kesejahteraan keluarga, karang taruna, dan lembaga pemberdayaan masyarakat atau yang disebut dengan nama lain. Lembaga kemasyarakatan desa bertugas membantu Pemerintah Desa dan merupakan mitra dalam memberdayakan masyarakat desa.

https://banjarkab.bps.go.id

https://tanahlautkab.bps.go.id

ULASAN

Jumlah desa di Kecamatan Bati-Bati sebanyak 14 desa yang terbagi menjadi 50 Rukun Warga (RW)/Dusun dan 161 Rukun Tetangga (RT). Setiap desa di Kecamatan Bati-Bati memiliki Badan Pemusyawaratan Desa (BPD) yang memiliki fungsi yaitu membahas dan menyepakati Rancangan Peraturan Desa (Perdes) bersama kepala desa; menampung dan menyalurkan aspirasi masyarakat desa; dan. melakukan pengawasan kinerja kepala desa. Anggota BPD di Kecamatan Bati-Bati masing-masing desa beragam yaitu antara 5-11 orang.

https://tanahlautkab.bps.go.id

2.1 WILAYAH ADMINISTRATIF

Tabel 2.1.1 Jumlah Rukun Warga (RW) dan Rukun Tetangga (RT) Menurut Desa/Kelurahan di Kecamatan Bati-Bati, 2023

Desa/Kelurahan	Rukun Warga (RW)	Rukun Tetangga (RT)
(1)	(2)	(3)
Benua Raya	4	15
Bati-Bati	4	12
Padang	3	14
Ujung	2	8
Ujung Baru	3	7
Nusa Indah	3	10
Kait-Kait	4	13
Kait-Kait Baru	7	14
Bentok Darat	5	16
Banyu Irang	3	16
Bentok Kampung	2	10
Sambangan	2	4
Liang Anggang	6	12
Pandahan	2	10
Bati-Bati	**50**	**161**

Sumber: Kantor Kecamatan

https://tanahlautkab.bps.go.id

Tabel 2.1.2 Nama Camat/Kepala Wilayah Kecamatan Bati-Bati, 2000-2023

Nama	Jabatan	Periode Jabatan
(1)	(2)	(3)
Drs. H. Syamsul Sairi	Camat	2000–2001
Drs. M. Rafiki Iffendi	Camat	2001
Drs. Munadi Anwar	Camat	2001–2004
Drs. Husein Irinata	Camat	2004–2006
Syaifullah, S.Sos.	Camat	2006–2008
Drs. Iriadi	Camat	2008–Jan 2012
Drs. H. M. Badaruddin	Camat	Jan–Mei 2012
Drs. Muhammad Noor	Camat	2012–2013
Bambang Kusudarisman, S.I.P, M.Si.	Camat	2013–2014
Mawardi, S.Sos.	Camat	2014–2016
H.Hasjudin, S.Sos.	Camat	2016–2019
Aan Nurhuda, S.Sos.	Camat	2020–2021
H. Rudiansyah, S.Pd. MM	Camat	2021–2022
Ade Gumilar, S.STP	Camat	2022–sekarang

Sumber: Kantor Kecamatan

https://tanahlautkab.bps.go.id

Tabel 2.1.3 Nama Kepala Desa di Kecamatan Bati-Bati, 2023

Desa	Nama Kepala Desa	Keterangan
(1)	(2)	(3)
Benua Raya	Sailil Irpan	–
Bati-Bati	Musmulyadi	–
Padang	Abdurahman	–
Ujung	H. Andi, SE	–
Ujung Baru	Irawan	–
Nusa Indah	Bibit Guntoro	–
Kait-Kait	Thesar T Jatmiko	–
Kait-Kait Baru	Arif Badrus Sholeh	–
Bentok Darat	H. Mukhlas, S.Pd.	–
Banyu Irang	Salasiah	–
Bentok Kampung	Syarwani	–
Sambangan	Muhammad Noor	–
Liang Anggang	Sukiman	–
Pandahan	H. Alfian Taurus, S.Pd	–

Sumber: Kantor Kecamatan

https://tanalbulkab.bps.go.id

Tabel 2.1.4 Jumlah Anggota Badan Permusyawaratan Desa (BPD) di Kecamatan Bati-Bati, 2023

Desa	Anggota BPD	Keterangan
(1)	(2)	(3)
Benua Raya	11	–
Bati-Bati	11	–
Padang	7	–
Ujung	7	–
Ujung Baru	6	–
Nusa Indah	9	–
Kait-Kait	5	–
Kait-Kait Baru	6	–
Bentok Darat	9	–
Banyu Irang	7	–
Bentok Kampung	7	–
Sambangan	5	–
Liang Anggang	11	–
Pandahan	7	–

Sumber: Kantor Kecamatan

https://tanahlautkab.bps.go.id

Tabel 2.1.5 Nama Ketua RT di Desa Benua Raya, 2023

RW/Dusun	RT	Nama Ketua RT
(1)	(2)	(3)
001	001	Fauzi Rahmi
	005	Abdul Yani
	006	Hj Aminah
	011	Ihsani
002	002	Arjani
	003	Saidah
	004	Badrudin
	015	Syamsudin
003	007	H.Nasrullah
	008	Marhani
	012	Qadim Ismail
004	009	Samsuni
	010	Rislani
	013	M. Subli
	014	Juaini

Sumber: Kantor Desa Benua Raya

https://tanahlautkab.bps.go.id

Tabel 2.1.6 Nama Ketua RT di Desa Bati-Bati, 2023

RW/Dusun	RT	Nama Ketua RT
(1)	(2)	(3)
001	001	Norjannah
	002	Arbain
	003	M Shabirin Suaib
002	004	Hj. Markiah
	005	Arsani
	006	Badruddin
003	007	Rusydi Saleh
	008	Abdul Basit
	009	M Rusydiani
004	010	Fachrudin
	011	H. Anang Ramli
	012	M. Yusuf

Sumber: Kantor Desa Bati-Bati

https://tanahlautkab.bps.go.id

Tabel 2.1.7 Nama Ketua RT di Desa Padang, 2023

RW/Dusun	RT	Nama Ketua RT
(1)	(2)	(3)
001	001	H Aliansyah
	003	H. Anang Intan
	006	Tambrin
	013	Sugianor
	014	Sriyoso
002	005	Abdan
	007	Zainal Muradi
	009	Haidi Sarbainoor
	011	Normaya
	012	M. Ali
003	002	Hadi Romani
	004	M. Najib
	008	H. Tuji
	010	Baihaki

Sumber: Kantor Desa Padang

https://tanahlautkab.bps.go.id

Tabel 2.1.8 Nama Ketua RT di Desa Ujung, 2023

RW/Dusun	RT	Nama Ketua RT
(1)	(2)	(3)
001	001	Jamhari
	002	Eko Sumarno
	003	Hadrudin
	004	Abdul Somad
002	005	Marhat
	006	Mashuri
	007	Bahran
	008	Saberani

Sumber: Kantor Desa Ujung

https://tanahlautkab.bps.go.id

Tabel 2.1.9 Nama Ketua RT di Desa Ujung Baru, 2023

RW/Dusun	RT	Nama Ketua RT
(1)	(2)	(3)
001	001	Jamani
	002	Rudiani
002	003	Mahrani
	004	Tamrin
	005	Mardiansyah
003	006	Mahlianor
	007	Arkani

Sumber: Kantor Desa Ujung Baru

https://tanahlautkab.bps.go.id

Tabel 2.1.10 Nama Ketua RT di Desa Nusa Indah, 2023

RW/Dusun	RT	Nama Ketua RT
(1)	(2)	(3)
001	001	Sugimin
	004	Mulyadi
	008	Purnomo
	009	Sudayar
002	003	Wahyono
	007	Imam Bukhori
	010	Sumanto
003	002	Ari Asmuri
	005	Mulyadi
	006	Sarifudin

Sumber: Kantor Desa Nusa Indah

https://tanahlautkab.bps.go.id

Tabel 2.1.11 Nama Ketua RT di Desa Kait-Kait, 2023

RW/Dusun	RT	Nama Ketua RT
(1)	(2)	(3)
001	001	Hendri Agus Susanto
002	002	Nyamiran
	003	Suyut
	004	Ribut Sukatno
	005	M.Asra Ansory
003	006	Sugiono
	007	Sudariyanto
	008	Edi Hariono
	009	Imam Subakir
	010	Lukman Hakim
004	011	Rozikin
	012	Supiyan Hadi
	013	Sabirin Nor

Sumber: Kantor Desa Kait-Kait

https://tanahlautkab.bps.go.id

Tabel 2.1.12 Nama Ketua RT di Desa Kait-Kait Baru, 2023

RW/Dusun	RT	Nama Ketua RT
(1)	(2)	(3)
001	001	M. Romadhon
	002	Hadransyah
002	003	Noor Yasin
	004	Hariyadi
003	005	Daniel
	006	Sugeng Heriawan
004	007	Agus Mujiono
	008	Abdul Rauf
005	009	Sapri
	014	Suharno
006	010	Suyono
	011	M. Nurdin
007	012	Udin
	013	M. Nurdin Islami

Sumber: Kantor Desa Kait-Kait Baru

https://tanahlautkab.bps.go.id

Tabel 2.1.13 Nama Ketua RT di Desa Bentok Darat, 2023

RW/Dusun	RT	Nama Ketua RT
(1)	(2)	(3)
001	001	Baderun
	002	Karnan
002	003	Bahrudin
	004	Sutrisno
003	005	Paryono
	006	Senen
004	007	Misran
	008	Suryanto
	009	Junaidi
	010	Eko
	013	Yusran
	014	Syamsudin
	015	Juhaini
	016	H. Agus Wijayadi
005	011	Taufik Ibrahim
	012	M. Hanafi

Sumber: Kantor Desa Bentok Darat

https://tanahlautkab.bps.go.id

Tabel 2.1.14 Nama Ketua RT di Desa Banyu Irang, 2023

RW/Dusun	RT	Nama Ketua RT
(1)	(2)	(3)
001	001	Anang Darmansyah
	002	Kusairi
	014	Suriansyah
	015	Radiatam Mardiah
002	003	Pheny Purwanti
	005	Martadi Arifani
	006	Nor Hasanah
	009	Rahmiati
	010	Rapandi
	012	Gajali Rahman
003	004	Alhianor
	007	Slamet Riadi
	008	Supian Hadi
	011	Akhmadi
	013	Murjani
	016	Yuliana

Sumber: Kantor Desa Banyu Irang

https://tanahlautkab.bps.go.id

Tabel 2.1.15 Nama Ketua RT di Desa Bentok Kampung, 2023

RW/Dusun	RT	Nama Ketua RT
(1)	(2)	(3)
001	001	Darkoni
	002	Abdul Muin
	007	Haryadi
	008	Aprani
002	003	Masrani
	004	Murjani
	005	Rahmat Nur Angga
	006	Wajihudin
	009	Sarbaini
	010	Saidi

Sumber: Kantor Desa Bentok Kampung

https://tanahlautkab.bps.go.id

Tabel 2.1.16 Nama Ketua RT di Desa Sambangan, 2023

RW/Dusun	RT	Nama Ketua RT
(1)	(2)	(3)
001	001	Mahdiansyah
	004	Riduan
002	002	Hadni
	003	Mansyah

Sumber: Kantor Desa Sambangan

https://tanahlautkab.bps.go.id

Tabel 2.1.17 Nama Ketua RT di Desa Liang Anggang, 2023

RW/Dusun	RT	Nama Ketua RT
(1)	(2)	(3)
001	001	Mala
002	002	Rupiani
003	003	Purnomo Asyhari
	004	Ibnu Rachman
004	005	Wahyuni
	006	Khamarudin
	009	Husin Abdullah
	010	Sulianto
005	011	Sutrisno
	012	Wahyono
006	007	Wahyudi
	008	Suwandi

Sumber: Kantor Desa Liang Anggang

https://tanahlautkab.bps.go.id

Tabel 2.1.18 Nama Ketua RT di Desa Pandahan, 2023

RW/Dusun	RT	Nama Ketua RT
(1)	(2)	(3)
001	001B	Raslan
	001A	Wardiansyah
	002	Sabirin Muhtar
	003	Jusrani
002	004	Ahmad Riyadi
	005	Bulhani
	006	Ahmad Yani
	007	Mujiburrahman
	008	Asnan
	009	Zainal

Sumber: Kantor Desa Pandahan

https://tanahlautkab.bps.go.id

https://tanahlautkab.bps.go.id

BAB 3
PENDUDUK

https://tanahlautkab.bps.go.id

PENJELASAN TEKNIS

1. Sumber utama data kependudukan adalah sensus penduduk yang dilaksanakan setiap sepuluh tahun sekali. Di dalam sensus penduduk, pencacahan dilakukan terhadap seluruh penduduk yang berdomisili di wilayah teritorial Indonesia termasuk warga negara asing kecuali anggota korps diplomatik negara sahabat beserta keluarganya.
   Untuk tahun yang tidak dilaksanakan sensus penduduk, data kependudukan diperoleh dari data registrasi penduduk didasarkan pada asumsi dari komponen-komponen perubahan penduduk, yaitu kelahiran, kematian, dan migrasi.

2. Penduduk Indonesia adalah semua orang yang berdomisili di wilayah teritorial Indonesia, mencakup Warga Negara Indonesia (WNI) dan Warga Negara Asing (WNA) yang telah menetap selama satu tahun atau lebih atau berencana menetap di wilayah Indonesia selama minimal satu tahun.

3. Kepadatan penduduk adalah ukuran persebaran penduduk yang menunjukkan jumlah penduduk untuk setiap kilometer persegi luas wilayah.

4. Rasio jenis kelamin adalah perbandingan antara jumlah penduduk laki-laki dan jumlah penduduk perempuan pada suatu daerah dan waktu tertentu, yang biasanya dinyatakan dalam banyaknya penduduk laki-laki per 100 penduduk perempuan.

https://manado.kemenkumham.go.id

https://tanahlautkab.bps.go.id

ULASAN

Jumlah penduduk di Kecamatan Bati-Bati pada tahun 2022 berdasarkan hasil registrasi penduduk dari Dinas Kependudukan dan Pencatatan Sipil Kabupaten Tanah Laut yaitu 46.195 jiwa. Penduduk paling banyak di Kecamatan Bati-Bati terdapat di Desa Bati-Bati dengan jumlah penduduk sebesar 5.585 jiwa dan paling sedikit di Desa Sambangan sejumlah 1.239 jiwa. Jika dilihat kepadatan penduduknya, Desa Benua Raya merupakan desa dengan kepadatan penduduk tertinggi yaitu 1.757 jiwa per km^2. Sementara itu di Desa Bentok Darat kepadatan penduduknya paling sedikit yaitu 61 jiwa per km^2. Rasio jenis kelamin penduduk di Kecamatan Bati-Bati secara umum yaitu 104 yang artinya terdapat sebanyak 104 penduduk laki-laki per 100 penduduk perempuan. Desa Ujung dan Ujung Baru merupakan desa yang rasio jenis kelaminnya kurang dari 100.

https://tanahlautkab.bps.go.id

Tabel 3.1 **Penduduk, Distribusi Persentase Penduduk, Kepadatan Penduduk, Rasio Jenis Kelamin Penduduk Menurut Desa/ Kelurahan di Kecamatan Bati-Bati, 2023**

Desa/Kelurahan	Penduduk		
	Laki-Laki	Perempuan	Jumlah
(1)	(2)	(3)	(4)
Benua Raya	1.911	1.919	3.830
Bati-Bati	2.900	2.685	5.585
Padang	1.719	1.688	3.407
Ujung	1.496	1.505	3.001
Ujung Baru	1.376	1.404	2.780
Nusa Indah	2.612	2.473	5.085
Kait-Kait	1.214	1.152	2.366
Kait-Kait Baru	1.111	1.088	2.199
Bentok Darat	1.946	1.893	3.839
Banyu Irang	1.659	1.599	3.258
Bentok Kampung	1.376	1.299	2.675
Sambangan	654	585	1.239
Liang Anggang	2.133	2.030	4.163
Pandahan	1.394	1.374	2.768
Bati-Bati	**23.501**	**22.694**	**46.195**

https://tanahlautkab.bps.go.id

Lanjutan Tabel 3.1

Desa/Kelurahan	Persentase Penduduk	Kepadatan Penduduk (per km²)	Rasio Jenis Kelamin Penduduk
(1)	(5)	(6)	(7)
Benua Raya	8,29	1.757	100
Bati-Bati	12,09	257	108
Padang	7,38	573	102
Ujung	6,50	180	99
Ujung Baru	6,02	338	98
Nusa Indah	11,01	287	106
Kait-Kait	5,12	242	105
Kait-Kait Baru	4,76	167	102
Bentok Darat	8,31	61	103
Banyu Irang	7,05	269	104
Bentok Kampung	5,79	91	106
Sambangan	2,68	197	112
Liang Anggang	9,01	209	105
Pandahan	5,99	340	101
Bati-Bati	**100,00**	**197**	**104**

Sumber: Dinas Kependudukan dan Pencatatan Sipil Kabupaten Tanah Laut

https://tanahlautkab.bps.go.id

https://tanahlautkab.bps.go.id

BAB 4
SOSIAL DAN KESEJAHTERAAN RAKYAT

https://kab-halmahera-tengah.bps.go.id

https://tanahlautkab.bps.go.id

PENJELASAN TEKNIS

1. Jalur Pendidikan di Indonesia terdiri atas 1) pendidikan formal, 2) pendidikan nonformal, dan 3) pendidikan informal yang ketiganya dapat saling melengkapi dan memperkaya (Undang-Undang No. 20 Tahun 2003 tentang Sistem Pendidikan Nasional).

2. Jenjang Pendidikan Formal terdiri atas pendidikan dasar, pendidikan menengah, dan pendidikan tinggi. Jenis pendidikan yang diajarkan mencakup pendidikan umum, kejuruan, akademik, profesi, vokasi, keagamaan, dan khusus.

- Pendidikan Dasar berbentuk Sekolah Dasar (SD) danMadrasah Ibtidaiyah (MI) atau bentuk lain yang sederajat serta Sekolah Menengah Pertama (SMP) dan MadrasahTsanawiyah (MTs), atau bentuk lain yang sederajat.
- Pendidikan Menengah berbentuk Sekolah Menengah Atas (SMA), Madrasah Aliyah (MA), Sekolah Menengah Kejuruan (SMK), dan Madrasah Aliyah Kejuruan (MAK), atau bentuk lain yang sederajat.
- Pendidikan Tinggi merupakan jenjang pendidikan setelah pendidikan menengah yang mencakup program pendidikan diploma, sarjana, magister, spesialis, dan doktor yang diselenggarakan oleh perguruan tinggi. Perguruan tinggi dapat berbentuk akademi, politeknik, sekolah tinggi, institut, atau universitas.

3. Dokter umum adalah dokter yang diperkenankan untuk melakukan praktik medis tanpa harus memiliki spesialisasi tertentu, sehingga memungkinkannya untuk memeriksa masalah kesehatan pasien secara umum untuk segala usia.

4. Rumah sakit adalah tempat pemeriksaan dan perawatan kesehatan, biasanya berada di bawah pengawasan dokter/tenaga medis, yang melayani pasien untuk berobat rawat jalan atau rawat inap. Undang-Undang RI No. 44 Tahun 2009 tentang Rumah Sakit mengelompokkan rumah sakit berdasarkan jenis pelayanan yang diberikan menjadi:

- Rumah sakit umum adalah rumah sakit yang memberikn pelayanan kesehatan pada semua bidang dan jenis penyakit.
- Rumah sakit khusus adalah rumah sakit yang memberikan pelayanan utama pada satu bidang atau satu jenis penyakit tertentu berdasarkan disiplin ilmu, golongan umur, organ, jenis penyakit, atau kekhususan lainnya.

https://kalimantan.bps.go.id

5. Rumah Sakit Bersalin adalah rumah sakit khusus untuk persalinan, dilengkapi pelayanan spesialis pemeriksaan kehamilan, persalinan, rawat inap dan rawat jalan ibu dan anak yang berada di bawah pengawasan dokter spesialis kandungan.

6. Rumah Bersalin adalah sarana pelayanan kesehatan dengan izin sebagai rumah bersalin, dilengkapi pelayanan pemeriksaan kehamilan, persalinan serta pemeriksaan ibu dan anak yang berada di bawah pengawasan bidan senior.

7. Poliklinik adalah sarana kesehatan yang dipakai untuk pelayanan, berobat jalan, biasanya berada di bawah pengawasan dokter/tenaga medis.

8. Pusat Kesehatan Masyarakat (Puskesmas) adalah unit pelaksana teknis dinas kesehatan kabupaten/kota yang mempunyai fungsi utama sebagai penyelenggara pelayanan kesehatan tingkat pertama. Wilayah kerja puskesmas maksimal adalah 1 (satu) kecamatan. Untuk dapat menjangkau wilayah kerjanya, Puskesmas mempunyai jaringan pelayanan yang meliputi unit Puskesmas Pembantu (Pustu), unit Puskesmas Keliling (Puskel), dan unit bidan desa/komunitas (Peraturan Menteri Kesehatan RI No. 75 Tahun 2014 tentang Pusat Kesehatan Masyarakat).

9. Apotek adalah suatu tempat tertentu yang digunakan untuk melakukan pekerjaan kefarmasian, dan penyaluran/penjualan obat atau bahan farmasi dan perbekalan kesehatan lainnya kepada masyarakat yang dikelola oleh tenaga apoteker (Peraturan Menteri Kesehatan RI No. 1332 Tahun 2002 Tentang Perubahan Atas Peraturan Menteri Kesehatan RI No. 922/MENKES/PER/X/1993 Tentang Ketentuan dan Tata Cara Pemberian Izin Apotek).

10. Air leding adalah sumber air yang berasal dari air yang telah melalui proses penjernihan dan penyehatan sebelum dialirkan kepada konsumen melalui instalasi berupa saluran air. Sumber air ini biasanya diusahakan oleh PAM/PDAM/BPAM. Termasuk dalam hal ini air leding yang didapat secara eceran.

11. Sumur terlindung adalah air yang berasal dari dalam tanah yang digali dan lingkar sumur tersebut dilindungi oleh tembok paling sedikit 0,8 meter di atas tanah dan 3 meter ke bawah tanah, serta ada lantai semen sejauh 1 meter dari lingkar sumur.

https://kotabatibati.bps.go.id

12. Sumber penerangan utama merupakan sumber penerangan yang paling banyak digunakan oleh rumah tangga apabila memiliki lebih dari satu sumber.

13. Fasilitas tempat buang air besar adalah ketersediaan jamban/kloset yang digunakan oleh rumah tangga.

14. Status kepemilikan bangunan tempat tinggal milik sendiri adalah tempat tinggal yang merupakan milik kepala rumah tangga atau salah seorang anggota rumah tangga. Rumah yang dibeli secara angsuran melalui kredit bank atau rumah dengan status sewa beli dianggap rumah milik sendiri.

15. Sanitasi layak adalah fasilitas sanitasi yang memenuhi syarat kesehatan, antara lain kloset menggunakan leher angsa, tempat pembuangan akhir tinja menggunakan tangki septik (septic tank) atau Instalasi/Sistem Pengolahan Air Limbah (IPAL/SPAL), dan fasilitas sanitasi tersebut digunakan oleh rumah tangga sendiri, bersama dengan rumah tangga lain tertentu, ataupun di MCK Komunal. Untuk daerah perdesaan, dikatakan memiliki akses sanitasi layak, jika kloset menggunakan leher angsa, tempat pembuangan akhir tinja ke tangki septik atau Instalasi/Sistem Pengolahan Air Limbah (IPAL/SPAL) atau lubang tanah dan fasilitas sanitasi tersebut digunakan oleh rumah tangga sendiri, bersama dengan rumah tangga lain tertentu, ataupun di MCK Komunal.
    Konsep sanitasi layak mengacu konsep terbaru berdasarkan Surat Kementerian Perencanaan Pembangunan Nasional/Bappenas Nomor 661/ Dt.2.4/01/2019.

16. Sumber air minum layak adalah jika rumah tangga menggunakan sumber air minum utama berupa leding, air terlindungi, atau air hujan. Air terlindungi mencakup sumur bor/pompa, sumur terlindung, dan mata air terlindung. Bagi rumah tangga yang menggunakan sumber air minum berupa air kemasan bermerk atau air isi ulang, maka rumah tangga dikategorikan memiliki akses air minum layak jika sumber air untuk mandi/cuci berasal dari leding, sumur bor/pompa, sumur terlindung, mata air terlindung, atau air hujan.
    Konsep air minum layak mengacu konsep terbaru berdasarkan Surat Kementerian Perencanaan Pembangunan Nasional/Bappenas Nomor 661/ Dt.2.4/01/2019.

https://nasional.kompas.com/

17. Peristiwa kejahatan yang dilaporkan adalah setiap peristiwa yang dilaporkan masyarakat pada Polri, atau peristiwa dimana pelakunya tertangkap tangan oleh kepolisian.

18. Jumlah kejahatan menggambarkan jumlah kasus kejahatan yang terjadi pada kurun waktu tertentu.

19. Tempat ibadah adalah bangunan/ruangan yang lokasinya tetap dan peruntukannya khusus untuk ibadah oleh masyarakat umum sesuai agama yang dianut tanpa memandang status kepemilikan, termasuk bangunan/ruangan yang lokasinya tetap dan fungsinya dikhususkan untuk ibadah di fasilitas umum. Tidak termasuk tempat ibadah yang khusus dipakai oleh pribadi/keluarga.

20. Pernikahan/Perkawinan merupakan ikatan lahir dan batin antara seorang wanita dengan seorang pria sebagai suami istri dengan tujuan membentuk keluarga (rumah tangga) yang bahagia dan kekal berdasarkan Ketuhanan Yang Maha Esa (Undang-Undang Nomor 1 Tahun 1974 tentang Perkawinan Pasal 1).

    Pernikahan/Perkawinan adalah sah, apabila dilakukan menurut hukum masing-masing agamanya dan kepercayaannya itu. Tiap-tiap pernikahan/perkawinan dicatat menurut peraturan perundang-undangan yang berlaku (Undang-undang Nomor 1 Tahun 1974 tentang Perkawinan Pasal 2). Dalam hal ini, pernikahan untuk yang beragama Islam dianggap sah menurut undang-undang jika tercatat di Kantor Urusan Agama (KUA). Pencatatan perkawinan tersebut dilakukan oleh pegawai pencatat nikah. Dengan demikian, setiap perkawinan harus dilangsungkan di hadapan dan di bawah pengawasan pegawai pencatat nikah. Pernikahan boleh dilakukan di KUA atau di luar KUA (nikah bedolan).

21. Perceraian adalah salah satu sebab putusnya perkawinan/pernikahan yang dapat terjadi karena talak (cerai talak) atau berdasarkan gugatan perceraian (cerai gugat). Undang-Undang Nomor 1 Tahun 1974 tentang Perkawinan Pasal 39 menyatakan: (1) Perceraian hanya dapat dilakukan di depan sidang Pengadilan setelah Pengadilan yang bersangkutan berusaha dan tidak berhasil mendamaikan kedua belah pihak; (2) Untuk melakukan perceraian harus ada cukup alasan bahwa antara suami istri itu tidak akan dapat rukun sebagai suami istri; (3) Tata cara perceraian di depan sidang Pengadilan diatur dalam peraturan perundangan tersebut.
    Data pernikahan dan perceraian yang tersedia dalam publikasi ini hanya

https://katuahkab.bps.go.id

mencakup pernikahan dan perceraian untuk yang beragama Islam. Data pernikahan diperoleh dari Dirjen Bimas Islam, Kementerian Agama RI. Sementara data perceraian diperoleh dari Dirjen Badan Peradilan Agama, Mahkamah Agung.

22. Bencana adalah peristiwa atau rangkaian peristiwa yang mengancam dan mengganggu kehidupan dan penghidupan masyarakat yang disebabkan baik oleh faktor alam dan atau faktor nonalam maupun faktor manusia sehingga mengakibatkan timbulnya korban jiwa, kerusakan lingkungan, kerugian harta benda, dan dampak psikologis.

23. Bencana Alam adalah peristiwa atau serangkaian peristiwa yang mengancam dan mengganggu kehidupan/penghidupan masyarakat yang disebabkan oleh faktor alam antara lain berupa gempa bumi, tsunami, gunung meletus, banjir, kekeringan, angin topan, dan tanah longsor sehingga mengakibatkan kerugian materi maupun nonmateri.

https://tanahlautkab.bps.go.id

https://tanahlautkab.bps.go.id

ULASAN

Fasilitas pendidikan yang terdapat di Kecamatan Bati-Bati terdiri dari 28 SD/MI, 10 SMP/MTs, dan 4 SMA/MA/SMK. Seluruh desa di Kecamatan Bati-Bati sudah memiliki sarana pendidikan Sekolah Dasar (SD), sedangkan untuk sarana pendidikan pada tingkat yang lebih tinggi hanya terdapat di beberapa desa.

Sarana kesehatan di Kecamatan Bati-Bati meliputi 3 puskesmas tanpa rawat inap, 4 klinik, dan 25 posyandu.

Secara umum keluarga di Kecamatan Bati-Bati menggunakan listrik PLN sebagai sumber penerangan utama, menggunakan elpiji 3 kg untuk bahan bakar untuk memasak, menggunakan fasilitas buang air besar berupa jamban milik sendiri, sumber air minumnya dari sumur, dan penerangan jalan utamanya merupakan listrik pemerintah.

Tempat peribadatan di Kecamatan Bati-Bati terdiri dari 23 masjid, 75 mushola dan 2 gereja Protestan. Masjid dan mushola dapat ditemui di hampir seluruh desa, sementara gereja Protestan berada di Desa Kait-Kait Baru dan Bentok Kampung. Di Kecamatan Bati-Bati tahun 2023, pernikahan paling banyak berlangsung pada bulan Juli.

https://tanahlautkab.bps.go.id

4.1 PENDIDIKAN

Tabel 4.1.1 Banyaknya Desa[1]/Kelurahan yang Memiliki Fasilitas Sekolah Menurut Tingkat Pendidikan di Kecamatan Bati–Bati, 2021–2023

Tingkat Pendidikan	2021[2]	2022[3]	2023[3]
(1)	(2)	(3)	(4)
Sekolah Dasar (SD)	14	14	14
Madrasah Ibtidaiyah (MI)	7	7	2
Sekolah Menengah Pertama (SMP)	6	6	6
Madrasah Tsanawiyah (MTs)	4	4	4
Sekolah Menengah Atas (SMA)	1	1	1
Sekolah Menengah Kejuruan (SMK)	1	1	1
Madrasah Aliyah (MA)	3	3	1
Akademi/Perguruan Tinggi	–	–	–

Catatan: [1] Desa pada tabel ini termasuk Unit Permukiman Transmigrasi (UPT) yang masih dibina oleh kementerian terkait

Sumber: [2] Badan Pusat Statistik, Pendataan Potensi Desa (Podes)

[3] Kantor Desa

https://tanahlautkab.bps.go.id

Tabel 4.1.2 Jumlah Sekolah Menurut Tingkat Pendidikan di Kecamatan Bati–Bati, 2023/2024

Tingkat Pendidikan	Negeri	Swasta	Jumlah
(1)	(2)	(3)	(4)
Taman Kanak-Kanak (TK)[1]	1	20	21
Raudatul Athfal (RA)[2]	–[3]	3	3
Sekolah Dasar (SD)[4]	24	–	24
Madrasah Ibtidaiyah (MI)[2]	–	4	4
Sekolah Menengah Pertama (SMP)[4]	6	–	6
Madrasah Tsanawiyah (MTs)[2]	–	4	4
Sekolah Menengah Atas (SMA)[4]	1	–	1
Sekolah Menengah Kejuruan (SMK)[4]	1	–	1
Madrasah Aliyah (MA)[2]	–	2	2

Catatan: [3] Seluruh Raudatul Athfal (RA) berstatus swasta

Sumber: [1] Kementerian Pendidikan, Kebudayaan, Riset, dan Teknologi; https://dapo.kemdikbud.go.id/sp; data semester genap per tanggal 3 September 2024

[2] Kementerian Agama, EMIS, data semester genap laporan sampai dengan 30 Juni 2024

[4] Kementerian Pendidikan, Kebudayaan, Riset, dan Teknologi; Sistem Data Pokok Pendidikan; data semester ganjil laporan sampai dengan 30 November 2023

https://tanahlautkab.bps.go.id

Tabel 4.1.3 Jumlah Guru Menurut Tingkat Pendidikan di Kecamatan Bati–Bati, 2023/2024

Tingkat Pendidikan	Negeri	Swasta	Jumlah
(1)	(2)	(3)	(4)
Taman Kanak-Kanak (TK)[1]	10	139	149
Raudatul Athfal (RA)[2]	–[3]	27	27
Sekolah Dasar (SD)[4]	293	–	293
Madrasah Ibtidaiyah (MI)[2]	–	74	74
Sekolah Menengah Pertama (SMP)[4]	96	–	96
Madrasah Tsanawiyah (MTs)[2]	–	79	79
Sekolah Menengah Atas (SMA)[4]	43	–	43
Sekolah Menengah Kejuruan (SMK)[4]	30	–	30
Madrasah Aliyah (MA)[2]	–	46	46

Catatan: [3] Seluruh Raudatul Athfal (RA) berstatus swasta
[5] Jumlah guru termasuk kepala sekolah dan guru

Sumber: [1] Kementerian Pendidikan, Kebudayaan, Riset, dan Teknologi; https://dapo.kemdikbud.go.id/sp; data semester genap per tanggal 3 September 2024
[2] Kementerian Agama, EMIS, data semester genap laporan sampai dengan 30 Juni 2024
[4] Kementerian Pendidikan, Kebudayaan, Riset, dan Teknologi; Sistem Data Pokok Pendidikan; data semester ganjil laporan sampai dengan 30 November 2023

https://tanahlautkab.bps.go.id

Tabel 4.1.4 Jumlah Murid Menurut Tingkat Pendidikan di Kecamatan Bati–Bati, 2023/2024

Tingkat Pendidikan	Negeri	Swasta	Jumlah
(1)	(2)	(3)	(4)
Taman Kanak-Kanak (TK)[1]	76	1.071	1.147
Raudatul Athfal (RA)[2]	–[3]	226	226
Sekolah Dasar (SD)[4]	3.738	–	3.738
Madrasah Ibtidaiyah (MI)[2]	–	1.305	1.305
Sekolah Menengah Pertama (SMP)[4]	1.175	–	1.175
Madrasah Tsanawiyah (MTs)[2]	–	880	880
Sekolah Menengah Atas (SMA)[4]	755	–	755
Sekolah Menengah Kejuruan (SMK)[4]	362	–	362
Madrasah Aliyah (MA)[2]	–	390	390

Catatan: [3] Seluruh Raudatul Athfal (RA) berstatus swasta

Sumber: [1] Kementerian Pendidikan, Kebudayaan, Riset, dan Teknologi; https://dapo.kemdikbud.go.id/sp; data semester genap per tanggal 3 September 2024

[2] Kementerian Agama, EMIS, data semester genap laporan sampai dengan 30 Juni 2024

[4] Kementerian Pendidikan, Kebudayaan, Riset, dan Teknologi; Sistem Data Pokok Pendidikan; data semester ganjil laporan sampai dengan 30 November 2023

https://tanahlautkab.bps.go.id

4.2 KESEHATAN

Tabel 4.2.1 Banyaknya Desa[1]/Kelurahan yang Memiliki Sarana Kesehatan Menurut Jenis Sarana Kesehatan di Kecamatan Bati–Bati, 2021–2023

Jenis Sarana Kesehatan	2021[2]	2022[3]	2023[3]
(1)	(2)	(3)	(4)
Rumah Sakit	–	–	–
Rumah Sakit Bersalin	–	–	–
Poliklinik/Balai Pengobatan	2	4	4
Puskesmas Rawat Inap	–	–	–
Puskesmas Tanpa Rawat Inap	2	2	3
Apotek	1	1	2

Catatan: [1] Desa pada tabel ini termasuk Unit Permukiman Transmigrasi (UPT) yang masih dibina oleh kementerian terkait
Sumber: [2] Badan Pusat Statistik, Pendataan Potensi Desa (Podes)
[3] Kantor Kecamatan

https://tanahlautkab.bps.go.id

Tabel 4.2.2 Banyaknya Warga Penderita Kekurangan Gizi Menurut Desa/Kelurahan di Kecamatan Bati–Bati, 2023

Desa/Kelurahan	2023
(1)	(2)
Benua Raya	–
Bati-Bati	–
Padang	–
Ujung	–
Ujung Baru	–
Nusa Indah	–
Kait-Kait	–
Kait-Kait Baru	–
Bentok Darat	–
Banyu Irang	–
Bentok Kampung	–
Sambangan	1
Liang Anggang	–
Pandahan	–
Bati-Bati	**1**

Sumber: Kantor Desa

https://tanahlautkab.bps.go.id

Tabel 4.2.3 **Jumlah Rumah Sakit Umum, Rumah Sakit Khusus, dan Puskesmas Menurut Desa/Kelurahan di Kecamatan Bati–Bati, 2023**

Desa/Kelurahan	Rumah Sakit Umum	Rumah Sakit Khusus	Puskesmas[1]	Klinik Pratama	Posyandu
(1)	(2)	(3)	(4)	(5)	(6)
Benua Raya	–	–	–	–	...
Bati-Bati	–	–	–	1	...
Padang	–	–	1	–	...
Ujung	–	–	–	–	...
Ujung Baru	–	–	–	–	...
Nusa Indah	–	–	–	1	...
Kait-Kait	–	–	–	–	...
Kait-Kait Baru	–	–	1	1	...
Bentok Darat	–	–	–	1	...
Banyu Irang	–	–	–	–	...
Bentok Kampung	–	–	1	–	...
Sambangan	–	–	–	–	...
Liang Anggang	–	–	–	–	...
Pandahan	–	–	–	–	...
Bati-Bati	**–**	**–**	**3**	**4**	**25**

Catatan: [1] Puskesmas yang teregistrasi
Sumber: Kantor Kecamatan, Dinas Kesehatan Kabupaten Tanah Laut

https://tanahlautkab.bps.go.id

Tabel 4.2.4 Banyaknya Tenaga Kesehatan Menurut Desa/Kelurahan di Kecamatan Bati–Bati, 2023

Desa/Kelurahan	Dokter	Perawat	Bidan	Farmasi	Ahli Gizi
(1)	(2)	(3)	(4)	(5)	(6)
Benua Raya	...	...	...	...	...
Bati-Bati	...	...	...	...	...
Padang	...	...	...	...	...
Ujung	...	...	...	...	...
Ujung Baru	...	...	...	...	...
Nusa Indah	...	...	...	...	...
Kait-Kait	...	...	...	...	...
Kait-Kait Baru	...	...	...	...	...
Bentok Darat	...	...	...	...	...
Banyu Irang	...	...	...	...	...
Bentok Kampung	...	...	...	...	...
Sambangan	...	...	...	...	...
Liang Anggang	...	...	...	...	...
Pandahan	...	...	...	...	...
Bati-Bati	**4**	**31**	**32**	**6**	**8**

Catatan: [1] Dokter dalam tabel ini termasuk dokter spesialis (selain spesialis gigi) dan dokter umum
Sumber: Kantor Kecamatan, Dinas Kesehatan Kabupaten Tanah Laut

https://tanahlautkab.bps.go.id

Tabel 4.2.5 Banyaknya Wanita Usia Subur (WUS) 15–49 Tahun, Pasangan Usia Subur (PUS) Dan Peserta Keluarga Berencana (KB) Menurut Desa/kelurahan di Kecamatan Bati–Bati, 2023

Desa/Kelurahan	WUS	PUS	Peserta KB
(1)	(2)	(3)	(4)
Benua Raya	912	605	516
Bati-Bati	1.244	892	810
Padang	807	587	494
Ujung	705	490	383
Ujung Baru	627	412	342
Nusa Indah	1.115	858	710
Kait-Kait	598	457	393
Kait-Kait Baru	512	370	317
Bentok Darat	1.291	826	668
Banyu Irang	819	583	478
Bentok Kampung	590	495	444
Sambangan	328	247	217
Liang Anggang	936	678	545
Pandahan	693	567	492
Bati-Bati	**11.177**	**8.067**	**6.809**

Sumber: Dinas Pengendalian Penduduk, Keluarga Berencana, Pemberdayaan Perempuan dan Perlindungan Anak Kabupaten Tanah Laut

https://tanahlautkab.bps.go.id

4.3 PERUMAHAN DAN LINGKUNGAN

Tabel 4.3.1 Banyaknya Desa[1]/Kelurahan Menurut Sumber Air Minum Sebagian Besar Keluarga di Kecamatan Bati–Bati, 2021–2023

Sumber Air Minum	2021[2]	2022[3]	2023[3]
(1)	(2)	(3)	(4)
Air Kemasan Bermerk	–	–	–
Air Isi Ulang	–	–	1
Leding dengan Meteran	–	–	–
Leding Tanpa Meteran	–	–	–
Sumur Bor atau Pompa	–	–	–
Sumur	14	14	13
Mata Air	–	–	–
Sungai/Danau/Kolam/ Waduk/Situ/ Embung/Bendungan	–	–	–
Air Hujan	–	–	–
Lainnya	–	–	–

Catatan: [1] Desa pada tabel ini termasuk Unit Permukiman Transmigrasi (UPT) yang masih dibina oleh kementerian terkait

Sumber: [2] Badan Pusat Statistik, Pendataan Potensi Desa (Podes)

[3] Kantor Desa

https://tanahlautkab.bps.go.id

Tabel 4.3.2 **Banyaknya Keluarga Menurut Desa/Kelurahan dan Jenis Pengguna Listrik di Kecamatan Bati–Bati, 2023**

Desa/Kelurahan	Pengguna Listrik			Bukan Pengguna Listrik
	PLN	Non-PLN	Jumlah	
(1)	(2)	(3)	(4)	(5)
Benua Raya	1.272	–	1.272	–
Bati-Bati	1.567	–	1.567	–
Padang	1.197	–	1.197	–
Ujung	1.037	–	1.037	–
Ujung Baru	845	–	845	–
Nusa Indah	1.057	–	1.057	–
Kait-Kait	687	–	687	–
Kait-Kait Baru	764	–	764	–
Bentok Darat	1.165	–	1.165	–
Banyu Irang	1.146	–	1.146	–
Bentok Kampung	777	–	777	–
Sambangan	419	–	419	–
Liang Anggang	1.389	–	1.389	–
Pandahan	984	–	984	–
Bati-Bati	**14.306**	**-**	**14.306**	**-**

Sumber: BPS, Pendataan Potensi Desa (Podes)

https://tanahlautkab.bps.go.id

Tabel 4.3.3 Banyaknya Desa/Kelurahan Menurut Sumber Penerangan Jalan Utama Desa/Kelurahan di Kecamatan Bati–Bati, 2021–2023

Sumber Penerangan Jalan Utama	2021[2]	2022[3]	2023[3]
(1)	(2)	(3)	(4)
Listrik Pemerintah	14	14	14
Listrik Non-Pemerintah	–	–	–
Non Listrik	–	–	–

Catatan: [1] Desa pada tabel ini termasuk Unit Permukiman Transmigrasi (UPT) yang masih dibina oleh kementerian terkait
Sumber: [2] Badan Pusat Statistik, Pendataan Potensi Desa (Podes)
[3] Kantor Desa

https://tanahlautkab.bps.go.id

Tabel 4.3.4 Banyaknya Desa/Kelurahan Menurut Penggunaan Fasilitas Tempat Buang Air Besar Sebagian Besar Keluarga di Kecamatan Bati–Bati, 2021–2023

Fasilitas Tempat Buang Air Besar	2021[2]	2022[3]	2023[3]
(1)	(2)	(3)	(4)
Jamban	14	14	14
Sendiri	14	14	14
Bersama	–	–	–
Umum	–	–	–
Bukan Jamban	–	–	–
Jumlah	**14**	**14**	**14**

Catatan: [1] Desa pada tabel ini termasuk Unit Permukiman Transmigrasi (UPT) yang masih dibina oleh kementerian terkait
Sumber: [2] Badan Pusat Statistik, Pendataan Potensi Desa (Podes)
[3] Kantor Desa

https://tanahlautkab.bps.go.id

Tabel 4.3.5 Banyaknya Desa/Kelurahan Menurut Jenis Bahan Bakar untuk Memasak yang Digunakan Sebagian Besar Keluarga di Kecamatan Bati–Bati, 2023

Jenis Bahan Bakar untuk Memasak	2023
(1)	(2)
Listrik	–
Elpiji 5,5 kg	–
Elpiji 12 kg	–
Elpiji 3 kg	14
Gas Kota	–
Biogas	–
Minyak Tanah	–
Briket	–
Arang	–
Kayu Bakar	–
Lainnya	–
Jumlah	**14**

Sumber: Kantor Desa

https://tanahlautkab.bps.go.id

4.4 AGAMA DAN SOSIAL LAINNYA

Tabel 4.4.1 Jumlah Tempat Peribadatan Menurut Desa/Kelurahan di Kecamatan Bati–Bati, 2023

Desa/Kelurahan	Masjid	Mushola	Gereja Protestan	Gereja Katholik	Pura	Vihara
(1)	(2)	(3)	(4)	(5)	(6)	(7)
Benua Raya	1	5	–	–	–	–
Bati-Bati	2	5	–	–	–	–
Padang	1	5	–	–	–	–
Ujung	2	6	–	–	–	–
Ujung Baru	1	7	–	–	–	–
Nusa Indah	3	9	–	–	–	–
Kait-Kait	1	6	–	–	–	–
Kait-Kait Baru	2	4	1	–	–	–
Bentok Darat	1	7	–	–	–	–
Banyu Irang	1	5	–	–	–	–
Bentok Kampung	2	5	1	–	–	–
Sambangan	2	–	–	–	–	–
Liang Anggang	3	8	–	–	–	–
Pandahan	1	3	–	–	–	–
Bati-Bati	**23**	**75**	**2**	**–**	**–**	**–**

Sumber: Kantor Desa

https://tanahlautkab.bps.go.id

Tabel 4.4.2 Banyaknya Kejadian Bencana Alam Menurut Desa/ Kelurahan dan Jenis Bencana Alam di Kecamatan Bati–Bati, 2023

Desa/Kelurahan	Gempa Bumi	Tsunami	Gunung Meletus	Tanah Longsor
(1)	(2)	(3)	(4)	(5)
Benua Raya	–	–	–	–
Bati-Bati	–	–	–	–
Padang	–	–	–	–
Ujung	–	–	–	–
Ujung Baru	–	–	–	–
Nusa Indah	–	–	–	–
Kait-Kait	–	–	–	–
Kait-Kait Baru	–	–	–	–
Bentok Darat	–	–	–	–
Banyu Irang	–	–	–	–
Bentok Kampung	–	–	–	–
Sambangan	–	–	–	–
Liang Anggang	–	–	–	–
Pandahan	–	–	–	–
Bati-Bati	**–**	**–**	**–**	**–**

https://tanahlautkab.bps.go.id

Lanjutan Tabel 4.4.2

Desa/Kelurahan	Banjir	Banjir Bandang	Kekeringan	Kebakaran Hutan dan Lahan
(1)	(6)	(7)	(8)	(9)
Benua Raya	–	–	–	1
Bati-Bati	–	–	–	1
Padang	–	–	–	1
Ujung	–	–	–	1
Ujung Baru	–	–	–	1
Nusa Indah	–	–	–	–
Kait-Kait	–	–	–	–
Kait-Kait Baru	–	–	–	–
Bentok Darat	–	–	–	–
Banyu Irang	–	–	–	–
Bentok Kampung	–	–	–	–
Sambangan	–	–	–	–
Liang Anggang	–	–	–	1
Pandahan	–	–	–	1
Bati-Bati	**–**	**–**	**–**	**7**

https://tanahlautkab.bps.go.id

Lanjutan Tabel 4.4.2

Desa/Kelurahan	Angin Puyuh/ Puting Beliung/ Topan	Gelombang Pasang	Abrasi
(1)	(10)	(11)	(12)
Benua Raya	–	–	–
Bati-Bati	–	–	–
Padang	–	–	–
Ujung	–	–	–
Ujung Baru	–	–	–
Nusa Indah	–	–	–
Kait-Kait	–	–	–
Kait-Kait Baru	–	–	–
Bentok Darat	–	–	–
Banyu Irang	–	–	–
Bentok Kampung	–	–	–
Sambangan	–	–	–
Liang Anggang	–	–	–
Pandahan	–	–	–
Bati-Bati	**–**	**–**	**–**

Sumber: Kantor Desa

https://tanahlautkab.bps.go.id

Tabel 4.4.3 **Banyaknya Korban Jiwa Akibat Bencana Alam Menurut Desa/Kelurahan dan Jenis Bencana Alam di Kecamatan Bati–Bati, 2023**

Desa/Kelurahan	Gempa Bumi	Tsunami	Gunung Meletus	Tanah Longsor
(1)	(2)	(3)	(4)	(5)
Benua Raya	–	–	–	–
Bati-Bati	–	–	–	–
Padang	–	–	–	–
Ujung	–	–	–	–
Ujung Baru	–	–	–	–
Nusa Indah	–	–	–	–
Kait-Kait	–	–	–	–
Kait-Kait Baru	–	–	–	–
Bentok Darat	–	–	–	–
Banyu Irang	–	–	–	–
Bentok Kampung	–	–	–	–
Sambangan	–	–	–	–
Liang Anggang	–	–	–	–
Pandahan	–	–	–	–
Bati-Bati	**–**	**–**	**–**	**–**

https://tanahlautkab.bps.go.id

Lanjutan Tabel 4.4.3

Desa/Kelurahan	Banjir	Banjir Bandang	Kekeringan	Kebakaran Hutan dan Lahan
(1)	(6)	(7)	(8)	(9)
Benua Raya	–	–	–	–
Bati-Bati	–	–	–	–
Padang	–	–	–	–
Ujung	–	–	–	–
Ujung Baru	–	–	–	–
Nusa Indah	–	–	–	–
Kait-Kait	–	–	–	–
Kait-Kait Baru	–	–	–	–
Bentok Darat	–	–	–	–
Banyu Irang	–	–	–	–
Bentok Kampung	–	–	–	–
Sambangan	–	–	–	–
Liang Anggang	–	–	–	–
Pandahan	–	–	–	–
Bati-Bati	**–**	**–**	**–**	**–**

https://tanahlautkab.bps.go.id

Lanjutan Tabel 4.4.3

Desa/Kelurahan	Angin Puyuh/ Puting Beliung/ Topan	Gelombang Pasang	Abrasi
(1)	(10)	(11)	(12)
Benua Raya	–	–	–
Bati-Bati	–	–	–
Padang	–	–	–
Ujung	–	–	–
Ujung Baru	–	–	–
Nusa Indah	–	–	–
Kait-Kait	–	–	–
Kait-Kait Baru	–	–	–
Bentok Darat	–	–	–
Banyu Irang	–	–	–
Bentok Kampung	–	–	–
Sambangan	–	–	–
Liang Anggang	–	–	–
Pandahan	–	–	–
Bati-Bati	**–**	**–**	**–**

Sumber: Kantor Desa

https://tanahlautkab.bps.go.id

Tabel 4.4.4 **Keberadaan Fasilitas/Upaya Antisipasi/Mitigasi Bencana Alam Menurut Desa/Kelurahan di Kecamatan Bati–Bati, 2023**

Desa/Kelurahan	Sistem Peringatan Dini Bencana Alam	Sistem Peringatan Dini Khusus Tsunami	Perlengkapan Keselamatan
(1)	(2)	(3)	(4)
Benua Raya	Tidak Ada	Bukan Wilayah Potensi Tsunami	Tidak Ada
Bati-Bati	Tidak Ada	Bukan Wilayah Potensi Tsunami	Tidak Ada
Padang	Tidak Ada	Bukan Wilayah Potensi Tsunami	Tidak Ada
Ujung	Tidak Ada	Bukan Wilayah Potensi Tsunami	Tidak Ada
Ujung Baru	Tidak Ada	Bukan Wilayah Potensi Tsunami	Tidak Ada
Nusa Indah	Tidak Ada	Bukan Wilayah Potensi Tsunami	Tidak Ada
Kait-Kait	Tidak Ada	Bukan Wilayah Potensi Tsunami	Tidak Ada
Kait-Kait Baru	Tidak Ada	Bukan Wilayah Potensi Tsunami	Tidak Ada
Bentok Darat	Tidak Ada	Bukan Wilayah Potensi Tsunami	Tidak Ada
Banyu Irang	Tidak Ada	Bukan Wilayah Potensi Tsunami	Tidak Ada
Bentok Kampung	Tidak Ada	Bukan Wilayah Potensi Tsunami	Tidak Ada
Sambangan	Tidak Ada	Bukan Wilayah Potensi Tsunami	Tidak Ada
Liang Anggang	Tidak Ada	Bukan Wilayah Potensi Tsunami	Tidak Ada
Pandahan	Tidak Ada	Bukan Wilayah Potensi Tsunami	Tidak Ada

https://tanalautkab.bps.go.id

Lanjutan Tabel 4.4.4

Desa/Kelurahan	Rambu-Rambu dan Jalur Evakuasi Bencana	Pembuatan, Perawatan, atau Normalisasi: Sungai, Kanal, Tanggul, Parit, Drainase, Waduk, Pantai, dll
(1)	(5)	(6)
Benua Raya	Tidak Ada	Tidak Ada
Bati-Bati	Tidak Ada	Ada
Padang	Tidak Ada	Ada
Ujung	Tidak Ada	Ada
Ujung Baru	Tidak Ada	Tidak Ada
Nusa Indah	Tidak Ada	Tidak Ada
Kait-Kait	Tidak Ada	Tidak Ada
Kait-Kait Baru	Tidak Ada	Tidak Ada
Bentok Darat	Tidak Ada	Tidak Ada
Banyu Irang	Tidak Ada	Tidak Ada
Bentok Kampung	Tidak Ada	Tidak Ada
Sambangan	Tidak Ada	Tidak Ada
Liang Anggang	Tidak Ada	Tidak Ada
Pandahan	Tidak Ada	Tidak Ada

Sumber: Kantor Desa

https://tanahbumbukab.bps.go.id

Tabel 4.4.5 Banyaknya Desa/Kelurahan yang Memiliki Kelompok Kegiatan Olahraga Menurut Jenis Olahraga dan Ketersedian Fasilitas/Lapangan Olahraga di Kecamatan Bati–Bati, 2023

Jenis Olahraga	Kondisi Fasilitas/Lapangan Olahraga			Tidak Ada Fasilitas/ Lapangan Olahraga
	Baik	Rusak Sedang	Rusak Parah	
(1)	(2)	(3)	(4)	(5)
Sepak Bola	10	1	–	3
Bola Voli	8	–	–	6
Bulu Tangkis	10	–	–	4
Bola Basket	1	–	–	13
Tenis Lapangan	–	–	–	14
Tenis Meja	3	–	–	11
Futsal	3	–	–	11
Renang	–	–	–	14
Bela Diri	–	–	–	14
Bilyard	–	–	–	14
Fitnes, Aerobik, dll	–	–	–	14
Lainnya	–	–	–	14

Sumber: Kantor Desa

https://tanahlautkab.bps.go.id

Tabel 4.4.6 Banyaknya Perkara Kejahatan/Pelanggaran yang Dilaporkan ke Kepolisian dan yang Diselesaikan di Kecamatan Bati–Bati, 2023

Jenis Kejahatan/Pelanggaran	Dilaporkan	Diselesaikan
(1)	(2)	(3)
Pencurian Ringan	...	...
Penipuan	...	...
Kebakaran	...	...
Penggelapan	...	...
Penganiayaan Berat	...	...
Penadahan	...	...
Perjudian	...	...
Perkosaan	...	...
Pelanggaran Lalu Lintas	...	...
Lain–Lain	...	...
Jumlah	**16**	**13**

Sumber: Kepolisian Resor Kabupaten Tanah Laut

https://tanahlautkab.bps.go.id

Tabel 4.4.7 Jumlah Pondok Pesantren, Jumlah Santri dan Guru/Kyai Menurut Desa/Kelurahan di Kecamatan Bati–Bati, 2023

Desa/Kelurahan	Pondok Pesantren	Santri	Guru/Kyai
(1)	(2)	(3)	(4)
Benua Raya	–	–	–
Bati-Bati	2	1.280	64
Padang	1	383	95
Ujung	–		–
Ujung Baru	–	–	–
Nusa Indah	–	–	–
Kait-Kait	–	–	–
Kait-Kait Baru	–	–	–
Bentok Darat	–	–	–
Banyu Irang	–	–	–
Bentok Kampung	1	552	45
Sambangan	–	–	–
Liang Anggang	–	–	–
Pandahan	–	–	–
Bati-Bati	**4**	**2.215**	**204**

Sumber: Kementerian Agama, EMIS, data semester ganjil tahun ajaran 2023/2024

https://tanahlautkab.bps.go.id

Tabel 4.4.8 Jumlah Penduduk Menurut Desa/Kelurahan dan Agama yang Dianut di Kecamatan Bati–Bati, 2023

Desa/Kelurahan	Islam	Protestan	Katolik	Hindu	Budha	Lainnya
(1)	(2)	(3)	(4)	(5)	(6)	(7)
Benua Raya	...	...	...	...	...	...
Bati-Bati	...	...	...	...	...	...
Padang	...	...	...	...	...	...
Ujung	...	...	...	...	...	...
Ujung Baru	...	...	...	...	...	...
Nusa Indah	...	...	...	...	...	...
Kait-Kait	...	...	...	...	...	...
Kait-Kait Baru	...	...	...	...	...	...
Bentok Darat	...	...	...	...	...	...
Banyu Irang	...	...	...	...	...	...
Bentok Kampung	...	...	...	...	...	...
Sambangan	...	...	...	...	...	...
Liang Anggang	...	...	...	...	...	...
Pandahan	...	...	...	...	...	...
Bati-Bati	**45.511**	**405**	**239**	**30**	**10**	**...**

Catatan: Lainnya termasuk agama Konghucu
Sumber: Kantor Kementerian Agama Kab. Tanah Laut

https://tanahlautkab.bps.go.id

Tabel 4.4.9 Banyaknya Nikah, Talak, Cerai, dan Rujuk Menurut Desa/ Kelurahan di Kecamatan Bati–Bati, 2023

Desa/Kelurahan	Nikah	Talak	Cerai	Rujuk
(1)	(2)	(3)	(4)	(5)
Benua Raya	18	...	...	...
Bati-Bati	27	...	...	...
Padang	14	...	...	...
Ujung	28	...	...	...
Ujung Baru	8	...	...	...
Nusa Indah	14	...	...	...
Kait-Kait	23	...	...	...
Kait-Kait Baru	33	...	...	...
Bentok Darat	13	...	...	...
Banyu Irang	31	...	...	...
Bentok Kampung	18	...	...	...
Sambangan	4	...	...	...
Liang Anggang	17	...	...	...
Pandahan	10	...	...	...
Bati-Bati	**258**	**17**	**54**	**...**

Sumber: KUA Kecamatan, Kantor Kementerian Agama Kab. Tanah Laut, Pengadilan Agama Pelaihari

https://tanahlautkab.bps.go.id

Tabel 4.4.10 Banyaknya Nikah, Talak, Cerai, dan Rujuk Menurut Bulan di Kecamatan Bati–Bati, 2023

Bulan	Nikah	Talak	Cerai	Rujuk
(1)	(2)	(3)	(4)	(5)
Januari	19	...	...	...
Februari	27	...	...	...
Maret	27	...	...	...
April	6	...	...	...
Mei	14	...	...	...
Juni	13	...	...	...
Juli	48	...	...	...
Agustus	20	...	...	...
September	16	...	...	...
Oktober	17	...	...	...
November	22	...	...	...
Desember	29	...	...	...
Jumlah	**258**	**17**	**54**	**...**

Sumber: KUA Kecamatan, Kantor Kementerian Agama Kab. Tanah Laut, Pengadilan Agama Pelaihari

https://tanahlautkab.bps.go.id

BAB 5
PERTANIAN

https://bontokab.bps.go.id

https://tanahlautkab.bps.go.id

PENJELASAN TEKNIS

1. Tanaman sayuran dan buah-buahan semusim

- Tanaman sayuran semusim adalah tanaman yang bermanfaat sebagai sayur, sebagai sumber vitamin, mineral, dan lain-lain yang berumur kurang dari satu tahun. Pada umumnya, bagian yang digunakan sebagai sayur berupa daun, bunga, buah, dan umbi.
- Tanaman buah-buahan semusim adalah tanaman yang menghasilkan buah segar sebagai sumber vitamin, mineral, dan lain-lain yang berumur kurang dari satu tahun dan berbatang lunak. Pada umumnya, buah yang dihasilkan dapat dikonsumsi tanpa dimasak terlebih dahulu.

2. Tanaman buah-buahan dan sayuran tahunan

- Tanaman buah-buahan tahunan adalah tanaman yang menghasilkan buah segar sebagai sumber vitamin, mineral, dan lain-lain yang berumur satu tahun atau lebih dan berbatang keras. Pada umumnya, buah yang dihasilkan dapat dikonsumsi tanpa dimasak terlebih dahulu.
- Tanaman sayuran tahunan adalah tanaman yang bermanfaat sebagai sayur, sebagai sumber vitamin, mineral, dan lain-lain yang berumur satu tahun atau lebih. Pada umumnya, bagian yang digunakan sebagai sayur berupa daun, bunga, buah, dan umbi.

3. Tanaman biofarmaka adalah tanaman yang bermanfaat untuk obat-obatan, kosmetik, dan kesehatan yang dikonsumsi atau digunakan dari bagian-bagian tanaman seperti daun, batang, buah, umbi (rimpang) ataupun akar.

4. Tanaman hias adalah tanaman yang mempunyai nilai keindahan baik bentuk, warna daun, tajuk maupun bunganya untuk penghias pekarangan dan lain sebagainya.

5. Luas panen tanaman hortikultura adalah luas tanaman sayuran, buah-buahan, biofarmaka, dan tanaman hias yang diambil hasilnya/dipanen pada periode pelaporan.

6. Luas panen untuk tanaman sayuran adalah luas tanaman yang dipanen sekaligus/habis/dibongkar dan luas tanaman yang dipanen berkali-kali (lebih dari satu kali)/belum habis.

- Tanaman yang dipanen sekaligus/habis/dibongkar adalah tanaman yang sehabis panen langsung dibongkar/dicabut, terdiri dari bawang merah,bawang putih, bawang daun, kentang, kol/kubis, kembang kol,

https://www.bps.go.id

petsai/sawi, wortel, lobak, dan kacang merah.

- Tanaman yang dipanen berkali-kali (lebih dari satu kali)/belum habis adalah tanaman yang pemanennya lebih dari satu kali dan biasanya dibongkar apabila panenan terakhir sudah tidak memadai lagi, terdiri dari : kacang panjang, cabe besar, cabe rawit, jamur, tomat, terung, buncis, ketimun, labu siam, kangkung, bayam, melon, dan semangka.

7. Produksi hortikultura adalah hasil menurut bentuk produk dari setiap tanaman sayuran, buah-buahan, biofarmaka dan tanaman hias yang diambil berdasarkan luas yang dipanen/tanaman yang menghasilkan pada bulan/triwulan laporan.

8. Tanaman perkebunan tahunan adalah tanaman perkebunan yang umumnya berumur lebih dari satu tahun dan pemungutan hasilnya dilakukan lebih dari satu kali dan tidak dibongkar sekali panen.

9. Tanaman perkebunan semusim adalah tanaman perkebunan yang pada umumnya berumur kurang dari satu tahun dan pemanenannya dilakukan satu kali atau beberapa kali masa panen.

10. Produksi Perkebunan adalah hasil dari setiap tanaman tahunan atau semusim menurut bentuk produksi (hasil) yang diambil berdasarkan luas yang dipanen pada periode laporan.

11. Bentuk produksi perkebunan meliputi karet kering (karet), kopra (kelapa), minyak kelapa sawit (kelapa sawit), biji kering (kopi dan kakao), daun kering (teh dan tembakau), bunga kering (cengkeh), gelondong kering (jambu mete), biji kering (pala), lada kering (lada), gula kristal putih (tebu), dan minyak nilam (nilam).

12. Data populasi dan produksi ternak berasal dari Direktorat Jenderal Peternakan dan Kesehatan Hewan, Kementerian Pertanian. Produksi daging sapi, kerbau, kuda, kambing, domba, dan babi dalam bentuk karkas ditambah edible portion, dihitung berdasarkan pemotongan ternak tercatat (di RPH, selain di RPH, Qurban) dan pemotongan ternak tidak tercatat.

13. Pemotongan ternak tercatat adalah pemotongan ternak yang dilakukan di Rumah Potong Hewan Ruminansia (RPH-R), Rumah Potong Hewan Babi (RPHB), dan Rumah Potong Hewan Unggas (RPH-U), baik milik pemerintah maupun swasta, serta tempat pemotongan hewan selain RPH yang

https://tanahbumbukab.bps.go.id

dilaporkan kepada dinas atau dicatat oleh dinas yang membidangi fungsi peternakan dan kesehatan hewan setempat.

14. Pemotongan ternak tidak tercatat adalah pemotongan yang dilakukan oleh orang perorangan yang tidak dilaporkan kepada dinas atau tidak dicatat oleh dinas yang membidangi fungsi peternakan dan kesehatan hewan setempat.

https://tanahlautkab.bps.go.id

https://tanahlautkab.bps.go.id

ULASAN

Luas panen dan produksi tanaman sayuran semusim terung pada tahun 2023 di Kecamatan Bati-Bati yaitu 28 hektar dan produksi 740 kuintal, sedangkan cabai besar dengan luas panen 27 hektar memproduksi 1.041 kuital. Produksi buah-buahan tahunan pepaya sebanyak 18.615 kuintal. Produksi tanaman biofarmaka terbesar di Kecamatan Bati-Bati yaitu kencur dengan total produksi 9,5 ton. Komoditas perkebunan unggulan di Kecamatan Bati-Bati adalah kelapa sawit. Produksi tanaman kelapa sawit di Kecamatan Bati-Bati tahun 2023 sebanyak 7.541,7 ton. Populasi unggas terbesar di Kecamatan Bati-Bati yaitu ayam pedaging dengan total 8.884.479 ekor sedangkan populasi ternak besar yaitu sapi potong dengan total 2.359 ekor ternak.

https://tanahlautkab.bps.go.id

Tabel 5.1 **Luas Panen Tanaman Sayuran dan Buah-buahan Semusim Menurut Jenis Tanaman di Kecamatan Bati-Bati (ha), 2020–2023**

Jenis Tanaman	2020	2021	2022	2023
(1)	(2)	(3)	(4)	(5)
Sayuran:				
Bawang Merah	–	–	–	–
Cabai Besar	10	9	4	8
Cabai Keriting	–	–	–	–
Cabai Rawit	9	6	15	20
Kentang	–	–	–	–
Kubis	–	–	–	–
Tomat	–	–	–	3
Bawang Putih	–	–	–	–
Terung	12	22	8	28
Buah-buahan:				
Semangka	–	–	–	–

Sumber: Badan Pusat Statistik, Statistik Pertanian Hortikultura SPH-SBS

https://tanahlautkab.bps.go.id

Tabel 5.2 **Produksi Tanaman Sayuran dan Buah-buahan Semusim Menurut Jenis Tanaman di Kecamatan Bati-Bati (kuintal), 2020–2023**

Jenis Tanaman	2020	2021	2022	2023
(1)	(2)	(3)	(4)	(5)
Sayuran:				
Bawang Merah	–	–	–	–
Cabai Besar	775	745		165
Cabai Keriting	–	–	–	–
Cabai Rawit	640	980	730	580
Kentang	–	–	–	–
Kubis	–	–	–	–
Tomat	–	–	–	90
Bawang Putih	–	–	–	–
Terung	660	1.625	420	740
Buah-buahan:				
Semangka	190	450	1.145	–

Sumber: Badan Pusat Statistik, Statistik Pertanian Hortikultura SPH-SBS

https://tanahlautkab.bps.go.id

Tabel 5.3 Luas Panen Tanaman Biofarmaka Menurut Jenis Tanaman di Kecamatan Bati-Bati (m^2), 2020–2023

Jenis Tanaman	2020	2021	2022	2023
(1)	(2)	(3)	(4)	(5)
Jahe	–	–	–	–
Laos/Lengkuas	–	–	–	–
Kencur	–	90.000	45.000	10.000
Kunyit	–	–	–	–

Sumber: Badan Pusat Statistik, Statistik Pertanian Hortikultura SPH-TBF

https://tanahlautkab.bps.go.id

Tabel 5.4 **Produksi Tanaman Biofarmaka Menurut Jenis Tanaman di Kecamatan Bati-Bati (kg), 2020–2023**

Jenis Tanaman	2020	2021	2022	2023
(1)	(2)	(3)	(4)	(5)
Jahe	–	–	–	–
Laos/Lengkuas	–	–	–	–
Kencur	–	225.000	47.900	9.500
Kunyit	–	–	–	–

Sumber: Badan Pusat Statistik, Statistik Pertanian Hortikultura SPH-TBF

https://tanahlautkab.bps.go.id

Tabel 5.5 **Luas Panen Tanaman Hias Menurut Jenis Tanaman di Kecamatan Bati-Bati (m^2), 2020–2023**

Jenis Tanaman	2020	2021	2022	2023
(1)	(2)	(3)	(4)	(5)
Anggrek Pot	–	–	–	–
Anggrek Potong	–	–	–	–
Krisan	–	–	–	–
Mawar	–	–	–	–
Sedap Malam	–	–	–	–

Sumber: Badan Pusat Statistik, Statistik Pertanian Hortikultura SPH-TH

https://tanahlautkab.bps.go.id

Tabel 5.6 Produksi Tanaman Hias Menurut Jenis Tanaman di Kecamatan Bati-Bati (tangkai), 2020–2023

Jenis Tanaman	2020	2021	2022	2023
(1)	(2)	(3)	(4)	(5)
Anggrek Pot	–	–	–	–
Anggrek Potong	–	–	–	–
Krisan	–	–	–	–
Mawar	–	–	–	–
Sedap Malam	–	–	–	–

Sumber: Badan Pusat Statistik, Statistik Pertanian Hortikultura SPH-TH

https://tanahlautkab.bps.go.id

Tabel 5.7 **Produksi Buah-buahan dan Sayuran Tahunan Menurut Jenis Tanaman di Kecamatan Bati-Bati (kuintal), 2020–2023**

Jenis Tanaman	2020	2021	2022	2023
(1)	(2)	(3)	(4)	(5)
Buah-Buahan:				
Mangga	4.000	8.600	130	450
Durian	2.500	2.530	–	810
Jeruk Siam/Keprok	2.250	2.675	60	645
Pisang	1.280	2.000	2.915	2.505
Pepaya	7.700	2.750	12.670	18.615
Nenas	65	70	115	105
Salak	–	–	–	–
Nangka/Cempedak	7.500	1.500	360	750
Rambutan	700	4.000	–	600
Buah Naga	–	–	–	–
Sayuran:				
Petai	295	618	50	560
Jengkol	–	–	–	–
Melinjo	–	–	–	–

Sumber: BPS, Statistik Pertanian Hortikultura SPH-BST

https://tanahlautkab.bps.go.id

Tabel 5.8 **Luas Areal Tanaman Perkebunan Menurut Jenis Tanaman di Kecamatan Bati-Bati (ha), 2020–2023**

Jenis Tanaman	2020	2021	2022	2023
(1)	(2)	(3)	(4)	(5)
Kelapa Sawit	1.204	1.364	1.370	1.378
Kelapa	15	13	13	13
Karet	1.461	1.441	1.443	1.437
Kopi	6	6	21	21
Kakao	–	–	–	–
Tebu	–	–	–	–
Teh	–	–	–	–
Tembakau	–	–	–	–

Sumber: Dinas Tanaman Pangan, Hortikultura dan Perkebunan

https://tanahlautkab.bps.go.id

Tabel 5.9 **Produksi Tanaman Perkebunan Menurut Jenis Tanaman di Kecamatan Bati-Bati (ton), 2020–2023**

Jenis Tanaman	2020	2021	2022	2023
(1)	(2)	(3)	(4)	(5)
Kelapa Sawit	2.534,60	2.636,40	5.288,40	7.541,70
Kelapa	13,42	13,13	26,10	38,22
Karet	732,41	667,76	1.333,11	2.258,00
Kopi	3,26	4,89	10,30	11,04
Kakao	–	–	–	–
Tebu	–	–	–	–
Teh	–	–	–	–
Tembakau	–	–	–	–

Sumber: Dinas Tanaman Pangan, Hortikultura dan Perkebunan

https://tanahlautkab.bps.go.id

Tabel 5.10 **Populasi Unggas Menurut Jenisnya di Kecamatan Bati-Bati (ekor), 2020–2023**

Jenis Unggas	2020	2021	2022	2023
(1)	(2)	(3)	(4)	(5)
Ayam Kampung	110.211	162.658	922.609	37.193
Ayam Petelur	3.366.104	3.911.421	592.487	2.006.533
Ayam Pedaging	8.781.745	7.632.439	15.507.493	8.884.479
Itik	7.650	9.100	5.875	2.646
Burung Puyuh	10.573	12.315	8.593	2.277

Sumber: Dinas Peternakan dan Kesehatan Hewan

https://tanahlautkab.bps.go.id

Tabel 5.11 Produksi Daging Ternak Unggas di Kecamatan Bati-Bati (kg), 2020–2023

Jenis Unggas	2020	2021	2022	2023
(1)	(2)	(3)	(4)	(5)
Ayam Kampung	7.104	6.440	315.983	22.090
Ayam Petelur	121.948	132.977	648.447	810.248
Ayam Pedaging	...	...	5.555.704	4.353.803
Itik	5.733	5.115	8.346	5.096
Burung Puyuh	...	...	1.143	1.098

Sumber: Dinas Peternakan dan Kesehatan Hewan

https://tanahlautkab.bps.go.id

Tabel 5.12 **Populasi Ternak Besar dan Kecil Menurut Jenisnya di Kecamatan Bati-Bati (ekor), 2020–2023**

Jenis Ternak	2020	2021	2022	2023
(1)	(2)	(3)	(4)	(5)
Sapi Perah	–	–		–
Sapi Potong	2.856	2.157	2.292	2.359
Kerbau	82	33	320	336
Kuda	–	–	–	–
Kambing	804	834	342	656
Domba	13	13	–	6
Babi	–	–	–	–

Sumber: Dinas Peternakan dan Kesehatan Hewan

https://tanahlautkab.bps.go.id

https://tanahlautkab.bps.go.id

BAB 6
PARIWISATA, TRANSPORTASI, DAN KOMUNIKASI

https://karawangkab.bps.go.id

https://tanahlautkab.bps.go.id

PENJELASAN TEKNIS

1. Konsep dan definisi pariwisata mengikuti rekomendasi *United Nations World Tourism Organization* (UNWTO).

2. Usaha penyediaan akomodasi adalah usaha yang menyediakan pelayanan penginapan yang dapat dilengkapi dengan pelayanan pariwisata lainnya. Usaha penyediaan akomodasi dapat berupa hotel, vila, pondok wisata, bumi perkemahan, persinggahan karavan, dan akomodasi lainnya yang digunakan untuk tujuan pariwisata.

3. Hotel adalah penyediaan akomodasi secara harian berupa kamar-kamar di dalam satu bangunan yang dapat dilengkapi dengan jasa pelayanan makan dan minum, kegiatan hiburan dan atau fasilitas lainnya. Hotel terdiri dari hotel berbintang dan hotel non- bintang.

4. Data transportasi dan komunikasi meliputi:
   a. Panjang jalan
   b. Angkutan darat
   c. Angkutan laut
   d. Angkutan udara
   e. Pos dan telekomunikasi

5. Kendaraan bermotor adalah setiap kendaraan yang digerakkan oleh peralatan teknik yang ada pada kendaraan tersebut, biasanya digunakan untuk angkutan orang atau barang di atas jalan raya selain kendaraan yang berjalan di atas rel. Kendaraan bermotor yang dicatat adalah semua jenis kendaraan kecuali kendaraan bermotor TNI/Polri dan Korps Diplomatik.

6. Kantor Pos adalah tempat pemberi pelayanan komunikasi tertulis dan atau surat elektronik, layanan paket, layanan logistik, layanan transaksi keuangan, dan layanan keagenan pos untuk kepentingan umum. Rumah pos berfungsi sama seperti kantor pos dan kantor pos pembantu, bedanya rumah pos biasanya terletak di daerah terpencil.

7. Telekomunikasi meliputi setiap pemancaran, penyampaian dan atau penerimaan dari setiap informasi berupa penandaan, isyarat, tulisan, gambar, suara dan suara melalui untaian kawat melalui sistem kabel, optik, radio atau sistem elektromagnetik lainnya.

https://tanahlautkab.bps.go.id

8. Jaringan telekomunikasi adalah rangkaian perangkat telekomunikasi dan kelengkapannya yang digunakan dalam bertelekomunikasi.

9. Internet adalah jaringan komunikasi elektronik yang menghubungkan jaringan komputer dan fasilitas komputer yang terorganisasi di seluruh dunia melalui telepon atau satelit.

https://tanahlautkab.bps.go.id

ULASAN

Pada Kecamatan Bati-Bati, tidak terdapat sarana akomodasi seperti hotel dan penginapan. Sarana transportasi antar desa di Kecamatan Bati-Bati dapat ditempuh melalui jalur darat dengan jenis permukaan jalan aspal/beton. Jalan antar desa ini umumnya dapat dilalui kendaraan roda empat atau lebih sepanjang tahun.

Seluruh desa di Kecamatan Bati-Bati sudah dijangkau oleh layanan operator seluler. Namun di Desa Sambangan kondisi sinyal telepon selulernya umumnya lemah. Seluruh desa di Kecamatan Bati-Bati kondisi sinyal internet telepon selulernya secara umum 5G/4G/LTE.

https://tanahlautkab.bps.go.id

6.1 PARIWISATA

Tabel 6.1.1 Jumlah Sarana Akomodasi Menurut Desa/Kelurahan dan Jenis Akomodasi di Kecamatan Bati-Bati, 2023

Desa/Kelurahan	Hotel	Penginapan
(1)	(2)	(3)
Benua Raya	–	–
Bati-Bati	–	–
Padang	–	–
Ujung	–	–
Ujung Baru	–	–
Nusa Indah	–	–
Kait-Kait	–	–
Kait-Kait Baru	–	–
Bentok Darat	–	–
Banyu Irang	–	–
Bentok Kampung	–	–
Sambangan	–	–
Liang Anggang	–	–
Pandahan	–	–
Bati-Bati	**–**	**–**

Sumber: Kantor Desa

https://tanahlautkab.bps.go.id

6.2 TRANSPORTASI

Tabel 6.2.1 Prasarana dan Sarana Transportasi Antar Desa/Kelurahan Menurut Desa/Kelurahan di Kecamatan Bati-Bati, 2023

Desa/Kelurahan	Jenis Prasarana Transportasi	Keberadaan Angkutan Umum
(1)	(2)	(3)
Benua Raya	Darat	Ada, dengan trayek tetap
Bati-Bati	Darat	Ada, dengan trayek tetap
Padang	Darat	Ada, dengan trayek tetap
Ujung	Darat	Ada, dengan trayek tetap
Ujung Baru	Darat	Ada, dengan trayek tetap
Nusa Indah	Darat	Ada, dengan trayek tetap
Kait-Kait	Darat	Tidak ada angkutan umum
Kait-Kait Baru	Darat	Tidak ada angkutan umum
Bentok Darat	Darat	Tidak ada angkutan umum
Banyu Irang	Darat	Tidak ada angkutan umum
Bentok Kampung	Darat	Tidak ada angkutan umum
Sambangan	Darat	Tidak ada angkutan umum
Liang Anggang	Darat	Ada, dengan trayek tetap
Pandahan	Darat	Ada, dengan trayek tetap

https://tanahbutkab.bps.go.id

Lanjutan Tabel 6.2.1

Desa/Kelurahan	Jenis Permukaan Jalan Darat Terluas	Dapat Dilalui Kendaraan Bermotor Roda 4 atau Lebih
(1)	(4)	(5)
Benua Raya	Aspal/beton	Sepanjang tahun
Bati-Bati	Aspal/beton	Sepanjang tahun
Padang	Aspal/beton	Sepanjang tahun
Ujung	Aspal/beton	Sepanjang tahun
Ujung Baru	Aspal/beton	Sepanjang tahun
Nusa Indah	Aspal/beton	Sepanjang tahun
Kait-Kait	Aspal/beton	Sepanjang tahun
Kait-Kait Baru	Aspal/beton	Sepanjang tahun
Bentok Darat	Aspal/beton	Sepanjang tahun
Banyu Irang	Aspal/beton	Sepanjang tahun
Bentok Kampung	Aspal/beton	Sepanjang tahun
Sambangan	Aspal/beton	Sepanjang tahun
Liang Anggang	Aspal/beton	Sepanjang tahun
Pandahan	Aspal/beton	Sepanjang tahun

Sumber: Kantor Desa

https://tanahbumbukab.bps.go.id

Tabel 6.2.2 Banyaknya Kendaraan Bermotor di Kecamatan Bati-Bati, 2021–2023

Jenis Kendaraan Bermotor	2021	2022	2023
(1)	(2)	(3)	(4)
Mobil Penumpang	1.091	1.329	1.452
Bus	–	8	1
Truk	362	476	488
Sepeda Motor	6.865	12.834	14.064

Sumber: Badan Keuangan Daerah Unit Pelayanan Pendapatan Daerah

https://tanahlautkab.bps.go.id

6.3 KOMUNIKASI

Tabel 6.3.1 Keberadaan Kantor Pos/Pos Pembantu/Rumah Pos, Pos Keliling, dan Perusahaan/Agen Jasa Ekspedisi Swasta Menurut Desa/Kelurahan di Kecamatan Bati-Bati, 2023

Desa/Kelurahan	Kantor Pos/Pos Pembantu/Rumah Pos	Pos Keliling	Perusahaan/Agen Jasa Ekspedisi Swasta
(1)	(2)	(3)	(4)
Benua Raya	Tidak ada	Tidak ada	Tidak ada
Bati-Bati	Tidak ada	Tidak ada	Tidak ada
Padang	Beroperasi	Ada	Tidak ada
Ujung	Tidak ada	Tidak ada	Beroperasi
Ujung Baru	Tidak ada	Tidak ada	Tidak ada
Nusa Indah	Tidak ada	Tidak ada	Beroperasi
Kait-Kait	Tidak ada	Tidak ada	Tidak ada
Kait-Kait Baru	Tidak ada	Ada	Tidak ada
Bentok Darat	Tidak ada	Tidak ada	Tidak ada
Banyu Irang	Tidak ada	Tidak ada	Tidak ada
Bentok Kampung	Tidak ada	Tidak ada	Tidak ada
Sambangan	Tidak ada	Tidak ada	Tidak ada
Liang Anggang	Tidak ada	Tidak ada	Tidak ada
Pandahan	Tidak ada	Tidak ada	Tidak ada

Sumber: Kantor Desa

https://tanahlautkab.bps.go.id

Tabel 6.3.2 Jumlah Menara Telepon Seluler dan Operator Layanan Komunikasi Telepon Seluler Menurut Desa/Kelurahan di Kecamatan Bati-Bati, 2023

Desa/Kelurahan	Jumlah Menara Telepon seluler	Jumlah Operator Layanan Komunikasi Telepon Seluler
(1)	(2)	(3)
Benua Raya	1	6
Bati-Bati	3	6
Padang	4	6
Ujung	2	7
Ujung Baru	2	6
Nusa Indah	2	6
Kait-Kait	1	3
Kait-Kait Baru	1	3
Bentok Darat	1	1
Banyu Irang	5	5
Bentok Kampung	2	3
Sambangan	–	3
Liang Anggang	5	7
Pandahan	4	6
Bati-Bati	**33**	**68**

Sumber: Kantor Desa

https://tanahlautkab.bps.go.id

Tabel 6.3.3 Kekuatan Sinyal Telepon Seluler dan Jenis Sinyal Internet Telepon Seluler Menurut Desa/Kelurahan di Kecamatan Bati-Bati, 2023

Desa/Kelurahan	Kekuatan Sinyal Telepon Seluler	Jenis Sinyal Internet Telepon Seluler
(1)	(2)	(3)
Benua Raya	Sangat kuat	5G/4G/LTE
Bati-Bati	Sangat kuat	5G/4G/LTE
Padang	Sangat kuat	5G/4G/LTE
Ujung	Sangat kuat	5G/4G/LTE
Ujung Baru	Sangat kuat	5G/4G/LTE
Nusa Indah	Sangat kuat	5G/4G/LTE
Kait-Kait	Kuat	5G/4G/LTE
Kait-Kait Baru	Sangat kuat	5G/4G/LTE
Bentok Darat	Kuat	5G/4G/LTE
Banyu Irang	Sangat kuat	5G/4G/LTE
Bentok Kampung	Sangat kuat	5G/4G/LTE
Sambangan	Lemah	5G/4G/LTE
Liang Anggang	Sangat kuat	5G/4G/LTE
Pandahan	Kuat	5G/4G/LTE

Sumber: Kantor Desa

https://tanahbumbukab.bps.go.id

BAB 7
PERBANKAN, KOPERASI, DAN PERDAGANGAN

https://tanahlautkab.bps.go.id

PENJELASAN TEKNIS

1. Pada Undang-undang Nomor 10 Tahun 1998 tentang Perbankan, Bank disebutkan sebagai badan usaha yang menghimpun dana dari masyarakat dalam bentuk simpanan dan menyalurkannya kepada masyarakat dalam bentuk kredit dan atau bentukbentuk lainnya dalam rangka meningkatkan taraf hidup Masyarakat.

2. Bank Umum adalah bank yang melaksanakan kegiatan usaha secara konvensional dan atau berdasarkan prinsip syariah, yang dalam kegiatannya memberikan jasa dalam lalu lintas pembayaran.

- Bank umum pemerintah meliputi Bank Rakyat Indonesia (BRI), Bank Negara Indonesia (BNI), Bank Mandiri, Bank Pembangunan Daerah (BPD), Bank Tabungan Negara (BTN), dan Teras BRI.
- Bank umum swasta, meliputi Bank Permata, Bank Syariah Indonesia (BSI), Bank Central Asia (BCA), Bank Mutiara, Rabo Bank, Bank Sinarmas, dsb.

3. Bank Perkreditan Rakyat (BPR) adalah bank yang menerima simpanan dalam bentuk deposito berjangka, tabungan, atau bentuk lain yang disamakan dengan itu, manyalurkan dana dalam bentuk kredit kepada masyarakat yang membutuhkan. Koperasi adalah salah satu bentuk lembaga profit sosial yang bertujuan untuk meningkatkan kesejahteraan anggotanya melalui berbagai bentuk usaha.

4. Koperasi Unit Desa adalah suatu Koperasi serba usaha yang beranggotakan penduduk desa dan berlokasi di daerah pedesaan, daerah kerjanya biasanya mencakup satu wilayah kecamatan. Pembentukan KUD ini merupakan penyatuan dari beberapa Koperasi pertanian yang kecil dan banyak jumlahnya di pedesaan. Koperasi Unit Desa (KUD) adalah suatu organisasi ekonomi yang bersifat sosial merupakan wadah bagi pengembangan berbagai kegiatan ekonomi masyarakat perdesaan yang diselenggarakan oleh dan untuk masyarakat itu sendiri.

5. Koperasi Industri Kecil dan Kerajinan Rakyat (Kopinkra) merupakan koperasi yang beranggotakan industri-industri kecil dan kerajinan rakyat yang ada di wilayah desa/kelurahan.

6. Koperasi Simpan Pinjam (Kospin) adalah koperasi yang bergerak di bidang simpanan dan pinjaman.

https://nasbahpublik.bps.go.id

7. Koperasi lainnya, seperti koperasi serbaguna dan koperasi konsumsi

8. Kelompok pertokoan adalah sejumlah toko yang terdiri dari minimal 10 toko dan mengelompok dalam satu lokasi. Dalam satu kelompok pertokoan, jumlah bangunan fisiknya dapat lebih dari satu. Tidak termasuk ke dalam kelompok pertokoan untuk sejumlah toko yang ada di dalam mall dan pusat perbelanjaan lainnya.

9. Pasar adalah tempat pertemuan antara penjual dan pembeli barang dan jasa. Pasar dapat menggunakan bangunan yang bersifat permanen atau semi permanen ataupun tanpa bangunan. Barang yang diperjualbelikan di dalam pasar dapat terdiri dari banyak komoditas (campuran) ataupun secara khusus suatu komoditas tertentu. Menurut Peraturan Presiden (Perpres) Nomor 112 Tahun 2007 tentang Penataan dan Pembinaan Pasar Tradisional, pasar adalah area tempat jual beli barang dengan jumlah penjual lebih dari satu baik yang disebut sebagai pusat perbelanjaan, pasar tradisional, pertokoan, mall, plasa, pusat perdagangan maupun sebutan lainnya.
   Banyaknya pasar yang dicatat mengacu pada lokasi dan kegiatan. Jika dua atau lebih pasar yang bangunannya berada di lokasi yang saling berdekatan maka dianggap terletak pada lokasi yang berbeda jika pasar-pasar tersebut pengelolanya berbeda. Jika pasar hanya aktif pada hari-hari tertentu saja tetap dicatat sebagai pasar.

10. Pasar dengan bangunan permanen adalah pasar pada bangunan tetap yang memiliki lantai, atap, dan dinding permanen.

11. Pasar dengan bangunan semi permanen adalah pasar pada bangunan tetap yang memiliki lantai dan atap, tetapi tanpa dinding. Bangunan pada pasar tradisional yang mencakup bangunan permanen dan semi permanen dikategorikan sebagai pasar dengan bangunan permanen.

12. Pasar tanpa bangunan adalah pasar yang tidak berada dalam bangunan.

13. Minimarket/swalayan adalah sistem pelayanan mandiri, menjual berbagai jenis barang secara eceran, dan semua barang memiliki label harga, dengan luas bangunan kurang dari 400 m^2. Yang dicatat adalah minimarket yang masih aktif.

14. Supermarket, atau dengan sebutan lain adalah tempat perdagangan dengan sistem pelayanan mandiri, semua barang memiliki label harga, dan

https://kalimantan.bps.go.id

luas minimal 400 m^2. Jika dalam 1 bangunan terdiri dari beberapa unit usaha tersebut, maka tetap dihitung sebagai satu kesatuan sarana ekonomi.

15. Restoran adalah suatu jenis usaha yang mempergunakan seluruh bangunan secara permanen untuk menyediakan jasa pangan yang pengolahan dan penyajiannya secara langsung di tempat sesuai dengan keinginan para pengguna jasa yang mempunyai ciri pembeli biasanya dikenakan pajak. Izin restoran dan kualifikasinya diberikan oleh Ditjen Pariwisata/Kanwil Parpostel setempat.

16. Rumah makan adalah jenis usaha yang menyediakan jasa pangan yang pengolahan makanannya dapat dilakukan diluar rumah makan, yang mempunyai ciri pembeli biasanya dikenakan pajak. Izin rumah makan diberikan oleh Diparda (pada kabupaten/kota). Di wilayah yang terdapat Dinas Pariwisata, biasanya pemberian izin ditangani oleh Direktorat Perekonomian/Bagian Perekonomian Pemda setempat.

17. Warung/kedai makanan minuman adalah usaha yang menjual makanan dan minuman siap saji yang dijual di bangunan yang tetap dan tidak mempunyai surat izin usaha. Ciri utama dari warung/kedai makanan minuman adalah pembeli biasanya tidak dikenakan pajak.

https://kemenkeu.go.id

https://tanahlautkab.bps.go.id

ULASAN

Sarana lembaga keuangan di Kecamatan Bati-Bati tahun 2023 yaitu 3 Bank Umum Pemerintah yang berada di Desa Bati-Bati, Padang, dan Nusa Indah. Terdapat 4 Koperasi Industri Kecil dan Kerajinan Rakyat (Kopinkra) dan 1 koperasi lainnya yang masih aktif beroperasi di Kecamatan Bati-Bati. Sarana perdagangan di Kecamatan Bati-Bati yaitu 1 kelompok pertokoan, 1 pasar dengan bangunan permanen, 9 pasar dengan bangunan semi permanen, 7 pasar tanpa bangunan, 8 minimarket/swalayan/supermarket, dan 2 restoran/rumah makan.

https://tanahlautkab.bps.go.id

Tabel 7.1 **Banyaknya Sarana Lembaga Keuangan Bank Menurut Desa/Kelurahan dan Jenis Bank di Kecamatan Bati-Bati, 2023**

Desa/Kelurahan	Bank Umum Pemerintah	Bank Umum Swasta	Bank Perkreditan Rakyat (BPR)
(1)	(2)	(3)	(4)
Benua Raya	–	–	–
Bati-Bati	1	–	–
Padang	1	–	–
Ujung	–	–	–
Ujung Baru	–	–	–
Nusa Indah	1	–	–
Kait-Kait	–	–	–
Kait-Kait Baru	–	–	–
Bentok Darat	–	–	–
Banyu Irang	–	–	–
Bentok Kampung	–	–	–
Sambangan	–	–	–
Liang Anggang	–	–	–
Pandahan	–	–	–
Bati-Bati	**3**	**–**	**–**

Sumber: Kantor Desa

https://tanahlautkab.bps.go.id

Tabel 7.2 **Banyaknya Koperasi Aktif Menurut Menurut Desa/ Kelurahan dan Jenis Koperasi di Kecamatan Bati-Bati, 2023**

Desa/Kelurahan	Koperasi Unit Desa (KUD)	Koperasi Industri Kecil dan Kerajinan Rakyat (Kopinkra)
(1)	(2)	(3)
Benua Raya	–	–
Bati-Bati	–	–
Padang	–	–
Ujung	–	–
Ujung Baru	–	–
Nusa Indah	–	–
Kait-Kait	–	–
Kait-Kait Baru	–	–
Bentok Darat	–	–
Banyu Irang	–	–
Bentok Kampung	–	4
Sambangan	–	–
Liang Anggang	–	–
Pandahan	–	–
Bati-Bati	**–**	**4**

https://tanahlautkab.bps.go.id

Lanjutan Tabel 7.2

Desa/Kelurahan	Koperasi Simpan Pinjam (Kospin)	Koperasi Lainnya
(1)	(4)	(5)
Benua Raya	–	–
Bati-Bati	–	–
Padang	–	1
Ujung	–	–
Ujung Baru	–	–
Nusa Indah	–	–
Kait-Kait	–	–
Kait-Kait Baru	–	–
Bentok Darat	–	–
Banyu Irang	–	–
Bentok Kampung	–	–
Sambangan	–	–
Liang Anggang	–	–
Pandahan	–	–
Bati-Bati	**–**	**1**

Sumber: Kantor Desa

https://tanahlautkab.bps.go.id

Tabel 7.3 **Banyaknya Sarana Perdagangan Menurut Desa/Kelurahan dan Jenis Sarana Perdagangan di Kecamatan Bati-Bati, 2023**

Desa/Kelurahan	Kelompok Pertokoan	Pasar dengan Bangunan Permanen	Pasar dengan Bangunan Semi Permanen
(1)	(2)	(3)	(4)
Benua Raya	–	–	–
Bati-Bati	–	–	1
Padang	–	–	–
Ujung	–	–	–
Ujung Baru	–	–	–
Nusa Indah	1	1	1
Kait-Kait	–	–	–
Kait-Kait Baru	–	–	2
Bentok Darat	–	–	1
Banyu Irang	–	–	1
Bentok Kampung	–	–	1
Sambangan	–	–	1
Liang Anggang	–	–	–
Pandahan	–	–	1
Bati-Bati	**1**	**1**	**9**

https://tanahlautkab.bps.go.id

Lanjutan Tabel 7.3

Desa/Kelurahan	Pasar tanpa Bangunan	Mini Market/ Swalayan/ Supermarket	Restoran/ Rumah Makan
(1)	(5)	(6)	(7)
Benua Raya	1	–	–
Bati-Bati	1	–	–
Padang	2	2	–
Ujung	1	1	1
Ujung Baru	–	1	–
Nusa Indah	–	2	1
Kait-Kait	–	–	–
Kait-Kait Baru	–	–	–
Bentok Darat	1	–	–
Banyu Irang	–	–	–
Bentok Kampung	–	–	–
Sambangan	–	–	–
Liang Anggang	–	2	–
Pandahan	1	–	–
Bati-Bati	**7**	**8**	**2**

Sumber: Kantor Desa

https://tanahlautkab.bps.go.id

DAFTAR PUSTAKA

Badan Ketahanan Pangan. 2018. *Neraca Bahan Makanan Indonesia 2018–2021*. Jakarta: Badan Ketahanan Pangan.

Badan Pusat Statistik. 2021. *Buku 3: Konsep dan Definisi Podes 2021*. Jakarta: Badan Pusat Statistik.

Badan Pusat Statistik. 2021. *Pedoman Pengumpulan Data Statistik Perikanan*. Jakarta: Badan Pusat Statistik.

Badan Pusat Statistik. 2022. *Buku 4 Konsep dan Definisi Survei Sosial Ekonomi Nasional Maret 2023*. Jakarta: Badan Pusat Statistik.

Badan Pusat Statistik. 2023. Statistik Kriminal 2023. Jakarta: Badan Pusat Statistik.

Badan Pusat Statistik. 2024. *Pedoman SEDAPP Online: Sedia Data Perusahaan Perkebunan dengan Aplikasi SKB-Online*. Jakarta: Badan Pusat Statistik.

Indonesia. Peraturan Kepala Badan Pusat Statistik Nomor 120 Tahun 2020 Tentang Klasifikasi Desa Perkotaan dan Perdesaan di Indonesia 2020. Badan Pusat Statistik. Jakarta.

Kementerian Dalam Negeri. 2019. *Peraturan Menteri Dalam Negeri Nomor 72 Tahun 2019 tentang Perubahan Atas Peraturan Menteri Dalam Negeri Nomor 137 Tahun 2017 Tentang Kode Dan Data Wilayah Administrasi Pemerintahan*. Jakarta.

Kementerian Dalam Negeri. 2022. *Keputusan Menteri Dalam Negeri Nomor 100.1.1-6117 tentang Pemberian dan Pemutakhiran Kode, Data Wilayah Administrasi Pemerintahan, dan Pulau Tahun 2022*. Jakarta.

Kementerian Pertanian, Direktorat Jenderal Hortikultura & Badan Pusat Statistik. 2022. *Pedoman Statistik Pertanian Hortikultura (SPH)*. Jakarta: Direktorat Jenderal Hortikultura, Kementerian Pertanian.

Kementerian Pertanian Republik Indonesia. 2023. *Statistik Peternakan dan Kesehatan Hewan 2023*. Jakarta: Kementerian Pertanian Republik Indonesia.

Keputusan Direktur Jenderal Peternakan dan Kesehatan Hewan No. 14087/ KPTS/ OT.040/F/11/2019 tentang Petunjuk Teknis Pengumpulan, Pengolahan, dan Penyajian Data Pokok Peternakan dan Kesehatan Hewan.

Keputusan Kepala Badan Pusat Statistik Nomor 6 Tahun 2022 tentang Penyelenggaraan Statistik Dasar.

Larasati, Widya. 2023. *Ringkasan Eksekutif Pengeluaran dan Konsumsi Penduduk Indonesia Maret 2023*. Volume 15 Nomor 2. Jakarta: Badan Pusat Statistik.

Peraturan Kepala Badan Nasional Penanggulangan Bencana Nomor 7 Tahun 2023 tentang Petunjuk Pelaksanaan Standar Data Kejadian dan Dampak Bencana.

Peraturan Menteri Dalam Negeri Nomor 72 Tahun 2019 tentang Perubahan Atas Peraturan Menteri Dalam Negeri Nomor 137 Tahun 2017 tentang Kode dan Data Wilayah

https://ranahlitbang.bps.go.id

Administrasi Pemerintahan.

Peraturan Menteri Kesehatan RI Nomor 1332 Tahun 2002 tentang Perubahan Atas Peraturan Menteri Kesehatan RI Nomor 922/MENKES/PER/X/1993 tentang Ketentuan dan Tata Cara Pemberian Izin Apotek. Peraturan Menteri Kesehatan Republik Insonesia Nomor 75 Tahun 2014 tentang Pusat Kesehatan Masyarakat.

Undang-Undang Nomor 24 Tahun 2013 tentang Perubahan atas Undang-Undang Nomor 23 Tahun 2006 tentang Administrasi Kependudukan.

Undang-Undang Republik Indonesia Nomor 44 Tahun 2009 tentang Rumah Sakit.

Undang-Undang Republik Indonesia Nomor 6 Tahun 2014 tentang Desa.

https://tanahlautkab.bps.go.id

https://tanahlautkab.bps.go.id

ST2023
SENSUS PERTANIAN

BerAKHLAK
Berorientasi Pelayanan Akuntabel Kompeten Harmonis Loyal Adaptif Kolaboratif

#bangga melayani bangsa

DATA
MENCERDASKAN BANGSA

https://tanahlautkab.bps.go.id

BADAN PUSAT STATISTIK
KABUPATEN TANAH LAUT

Jl. A. Syairani No. 9 Komplek Perkantoran Gagas, Pelaihari 70814
Telp.: (0512) 21092 Fax.: (0512) 21213
Homapage: http://www.tanahlautkab.bps.go.id
Email:bps6301@bps.go.id

ISSN 0852-5048
9 770852 504001