KATALOG : 1102001.6302200

KECAMATAN PAMUKAN UTARA DALAM ANGKA

2024

https://kotabarukab.bps.go.id

BADAN PUSAT STATISTIK
KABUPATEN KOTABARU

https://kotabarukab.bps.go.id

KATALOG : 1102001.6302200

https://kotabarukab.bps.go.id

KECAMATAN PAMUKAN UTARA DALAM ANGKA

2024

BADAN PUSAT STATISTIK
KABUPATEN KOTABARU

KECAMATAN PAMUKAN UTARA DALAM ANGKA
2024
Volume XVII, 2024

Katalog: 1102001.6302200
ISSN: 2746-735X
Nomor Publikasi: 63020.24031

Ukuran Buku: 14,8 cm x 21 cm
Jumlah Halaman: xxii + 44 hal

Penyusun Naskah:
BPS Kabupaten Kotabaru

Penyunting:
BPS Kabupaten Kotabaru

Pembuat Kover:
BPS Kabupaten Kotabaru

Penerbit:
©BPS Kabupaten Kotabaru

Sumber Ilustrasi:...

Dilarang mereproduksi dan/atau menggandakan sebagian atau seluruh isi
buku ini untuk tujuan komersial tanpa izin tertulis dari Badan Pusat Statistik Kabupaten Kotabaru.

https://kotabarukab.bps.go.id

ISSN 2746-735X

TIM PENYUSUN
KECAMATAN PAMUKAN UTARA DALAM ANGKA 2024

Volume XVII, 2024

Pengarah
Widhi Pranowo

Penanggung Jawab
Widhi Pranowo

Penyunting
Muhammad Iswanto

Pengolah Data dan Penulis Naskah
Pandhu Piwulang
Muhammad Baital Salsabil

Penata Letak
Pandhu Piwulang
Muhammad Baital Salsabil

https://kotasukabumkab.bps.go.id

https://kotabarukab.bps.go.id

KONTRIBUTOR DATA

1. Kementerian Agama
2. Kementerian Pendidikan dan Kebudayaan
3. Badan Pusat Statistik
4. Sekretariat Daerah Kabupaten Kotabaru
5. Dinas Kependudukan dan Pencatatan Sipil

https://kotabarukab.bps.go.id

https://kotabarukab.bps.go.id

PETA WILAYAH KECAMATAN PAMUKAN UTARA

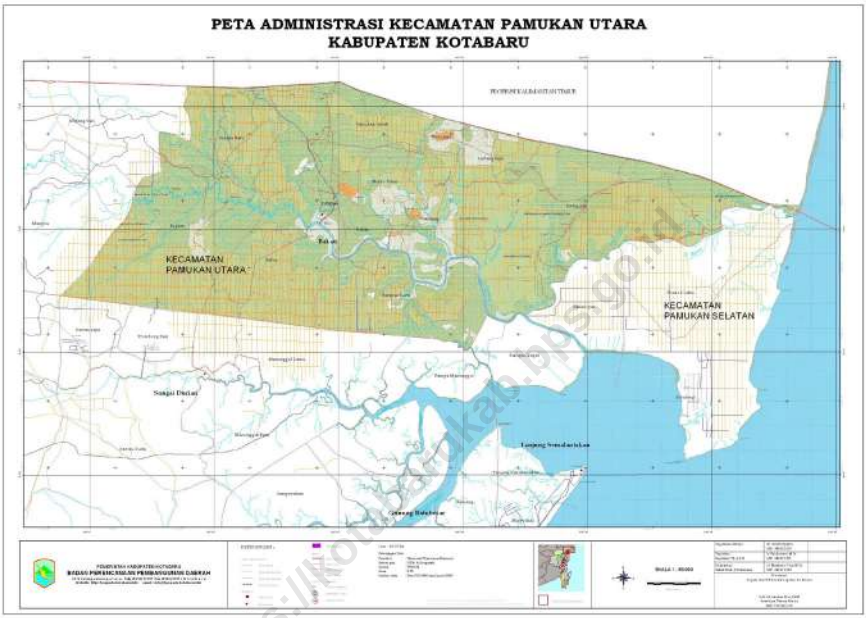

https://kotabarukab.bps.go.id

https://kotabarukab.bps.go.id

KEPALA BPS KABUPATEN KOTABARU

https://kotabarukab.bps.go.id

Widhi Pranowo

https://kotabarukab.bps.go.id

KATA PENGANTAR

Dalam upaya yang kesekian kalinya ini, kami mempersembahkan kembali suatu publikasi yang berisikan data-data statistik yang menggambarkan suatu kecamatan yaitu "KECAMATAN PAMUKAN UTARA DALAM ANGKA TAHUN 2024".

Kami sangat berterima kasih kepada bapak/ibu camat beserta jajarannya yang telah sudi memberikan dukungannya, baik secara moril ataupun materil dan sambutan yang sangat baik atas terbitnya publikasi ini. Tak lupa pula kami ucapkan terima kasih kepada semua Kepala Dinas/Instansi Jawatan Kecamatan dan Kepala Desa yang telah memberikan bantuannya berupa data-data statistik yang diperlukan.

Kami menyadari, publikasi ini masih jauh dari kesempurnaan. Oleh karena itu, kami mengharap semua pihak untuk membantu mewujudkan kesempurnaan itu dengan memberikan saran dan kritik yang positif. Akhirnya, dengan terbitnya publikasi ini semoga mampu memberikan manfaat sesuai dengan keperluannya.

https://kotabarukab.bps.go.id

Kotabaru, September 2024
Kepala BPS
Kabupaten Kotabaru

Widhi Pranowo

ISSN 2746-735X

DAFTAR ISI

KECAMATAN PAMUKAN UTARA DALAM ANGKA
2024
Volume XVII, 2024

Halaman

Kata Pengantar xi
Daftar Isi xii
Daftar Tabel xiii
Daftar Gambar xvii
Penjelasan Umum xix
Daftar Singkatan xxi
1. Geografi 1
2. Pemerintahan 9
3. Penduduk 13
4. Sosial dan Kesejahteraan Rakyat 19
5. Pertanian 33
Daftar Pustaka 43

https://rotabarukab.bps.go.id

DAFTAR TABEL

Tabel Halaman

1. GEOGRAFI

1.1 Luas Daerah Menurut Desa/Kelurahan di Kecamatan Pamukan Utara, 2023 6

1.2 Jarak ke Ibukota Kecamatan dan Ibukota Kabupaten Menurut Desa/Kelurahan di Kecamatan Pamukan Utara (km), 2023 7

2. PEMERINTAHAN

2.1 Jumlah Rukun Warga (RW)/Dusun dan Rukun Tetangga (RT) Menurut Desa/Kelurahan di Kecamatan Pamukan Utara, 2023 12

3. PENDUDUK

3.1 Penduduk, Distribusi Persentase Penduduk, Kepadatan Penduduk, Rasio Jenis Kelamin Penduduk Menurut Desa/ Kelurahan di Kecamatan Pamukan Utara, 2023..... 17

4. SOSIAL DAN KESEJAHTERAAN RAKYAT

4.1 PENDIDIKAN

4.1.1 Banyaknya Desa/Kelurahan yang Memiliki Fasilitas Sekolah Menurut Tingkat Pendidikan di Kecamatan Pamukan Utara, 2021-2023..... 22

4.1.2 Jumlah Sekolah Menurut Tingkat Pendidikan di Kecamatan Pamukan Utara, 2022/2023 dan 2023/2024 23

4.1.3 Jumlah Guru Menurut Tingkat Pendidikan di Kecamatan Pamukan Utara, 2022/2023 dan 2023/2024 24

4.1.4 Jumlah Murid Menurut Tingkat Pendidikan di Kecamatan Pamukan Utara, 2022/2023 dan 2023/2024 25

https://kotabarukab.bps.go.id

Tabel Halaman

4.2 KESEHATAN

4.2.1 Banyaknya Desa/Kelurahan yang Memiliki Sarana Kesehatan Menurut Jenis Sarana Kesehatan di Kecamatan Pamukan Utara, 2021-2023 26

4.3 PERUMAHAN DAN LINGKUNGAN

4.3.1 Banyaknya Desa/Kelurahan Menurut Sumber Air Minum Sebagian Besar Keluarga di Kecamatan Pamukan Utara, 2021-2023 27

4.3.2 Banyaknya Desa/Kelurahan Menurut Sumber Penerangan Jalan Utama di Kecamatan Pamukan Utara, 2021-2023 28

4.3.3 Banyaknya Desa/Kelurahan Menurut Penggunaan Fasilitas Tempat Buang Air Besar Sebagian Besar Keluarga di Kecamatan Pamukan Utara, 2021-2023 29

4.4 AGAMA DAN SOSIAL LAINNYA

4.4.1 Jumlah Tempat Peribadatan Menurut Desa/Kelurahan di Kecamatan Pamukan Utara, 2023 30

4.4.2 Jumlah Penduduk Menurut Desa/Kelurahan dan Agama yang Dianut di Kecamatan Pamukan Utara, 2023 31

5. PERTANIAN

5.1 Luas Panen Tanaman Sayuran dan Buah-buahan Semusim Menurut Jenis Tanaman di Kecamatan Pamukan Utara (ha), 2020–2023 36

5.2 Produksi Tanaman Sayuran dan Buah-buahan Semusim Menurut Jenis Tanaman di Kecamatan Pamukan Utara (kuintal), 2020–2023 37

5.3 Luas Panen Tanaman Biofarmaka Menurut Jenis Tanaman di Kecamatan Pamukan Utara (m^2), 2020–2023 38

5.4 Produksi Tanaman Biofarmaka Menurut Jenis Tanaman di Kecamatan Pamukan Utara (kg), 2020–2023 39

5.5 Luas Panen Tanaman Hias Menurut Jenis Tanaman di Kecamatan Pamukan Utara (m^2), 2020–2023 40

https://kabupatenkab.bps.go.id

Tabel Halaman

5.6 Produksi Tanaman Hias Menurut Jenis Tanaman di Kecamatan Pamukan Utara (tangkai), 2020–2023 41
5.7 Produksi Buah-Buahan dan Sayuran Tahunan Menurut Jenis Tanaman di Kecamatan Pamukan Utara (kuintal), 2020–2023 42

https://kotabarukab.bps.go.id

https://kotabarukab.bps.go.id

DAFTAR GAMBAR

Gambar Halaman

1.1 Luas Daerah Menurut Desa/Kelurahan, 2023 4

1.2 Jarak ke Ibukota Kecamatan Menurut Desa/Kelurahan di Kecamatan Pamukan Utara, 2023 5

3.1 Jumlah Penduduk Menurut Desa/Kelurahan di Kecamatan Pamukan Utara, 2023 16

https://kotabarukab.bps.go.id

https://kotabarukab.bps.go.id

PENJELASAN UMUM

Tanda-tanda, satuan-satuan, dan lain-lainnya yang digunakan dalam publikasi ini adalah sebagai berikut:

1. TANDA-TANDA

Data tidak tersedia	:	...
Tidak ada atau nol	:	–
Data dapat diabaikan	:	~0
Tanda decimal	:	,
Data tidak dapat ditampilkan	:	NA
Angka estimasi	:	e
Angka diperbaiki	:	r
Angka sementara	:	*
Angka sangat sementara	:	**
Angka sangat sangat sementara	:	***

2. SATUAN

barel	:	158,99 liter = 1/6,2898 m^3
hektare (ha)	:	10.000 m^2
kilometer (km)	:	1.000 meter
knot	:	1,8523 km/jam
kuintal	:	100 kg
KWh	:	1.000 Watt *hour*
MWh	:	1.000 KWh
liter (untuk beras)/	:	0,80 kg
MMSCF	:	1/35,3 m^3
metrik ton (m.ton)	:	0,98421 long ton = 1.000 kg
ons	:	28,31 gram
ton	:	1.000 kg

Satuan lain: buah, dus, butir, helai/lembar, kaleng, batang, pulsa, ton kilometer (ton-km), jam, menit, persen (%).

Perbedaan angka di belakang koma disebabkan oleh pembulatan angka.

https://rotabanukab.bps.go.id

https://kotabarukab.bps.go.id

DAFTAR SINGKATAN

SI	:	Stasiun Iklim
SMPK	:	Stasiun Meterologi Pertanian Khusus
t.t	:	Tempat tidur
BCG	:	Bacillus Calmette Guerin
DPT	:	Difteri, Pertusis, Tetanus
TT	:	Tetanus Toxoid
IOT	:	Industri Obat Tradisional
IKOT	:	Industri Kecil Obat Tradisional
Alkes	:	Alat kesehatan
PKRT	:	Perbekalan Kesehatan Rumah tangga
Kompl	:	Komplemen
IRTP	:	Industri Pangan Produksi Rumah Tangga
PBF	:	Pedagang Besar Farmasi
GFK	:	Gudang Farmasi Kab/Kota
RB	:	Rumah Bersalin
Pustu	:	Puskesmas pembantu
BP	:	Balai Pengobatan
TPS	:	Tempat Pembuangan Sampah Sementara
Jamkesmas	:	Jaminan kesehatan masyarakat miskin
PJKMU	:	Program Jaminan Kesehatan Masyarakat Umum
SIUP	:	Surat Ijin Usaha Perdagangan
TDP	:	Tanda Daftar Perusahaan
API	:	Angka Pengenal Importir

https://kotabarukab.bps.go.id

https://kotabarukab.bps.go.id

BAB I
GEOGRAFI

/ge.o.gra.fi/

letak suatu daerah dilihat dari kenyataannya di bumi atau posisi daerah itu pada bola bumi dibandingkan dengan posisi daerah lain.

#GEOGRAPHY

https://kotabarukab.bps.go.id

https://kotabarukab.bps.go.id

ULASAN

Kecamatan Pamukan Utara terletak di pulau yang berbeda dengan Ibukota Kabupaten Kotabaru. Secara geografis, Kecamatan Pamukan Utara memiliki area seluas 572,36 km2. Kecamatan Pamukan Utara terdiri dari 13 desa, yaitu, Bepara, Bakau, Kalian, Binturung, Harapan Baru, Tamiang, Lintang Jaya, Mulyo Harjo, Wonorejo, Pamukan Indah, Balaimea, Betung, dan Sekayu Baru. Ibukota Kecamatan Pamukan Utara terletak di Desa Bakau. Seperti halnya dengan kecamatan lain di Kabupaten Kotabaru, Kecamatan Pamukan Utara memiliki area yang luas, sehingga jarak antara satu desa dengan desa lainnya cukup jauh. Desa Harapan Baru merupakan desa terjauh yang ada di Kecamatan Pamukan Utara. Desa Harapan Baru berjarak sekitar 30 km dari Ibukota Kecamatan Pamukan Utara.

https://kotabarukab.bps.go.id

Gambar 1.1 Luas Daerah menurut Desa/Kelurahan (%), 2023

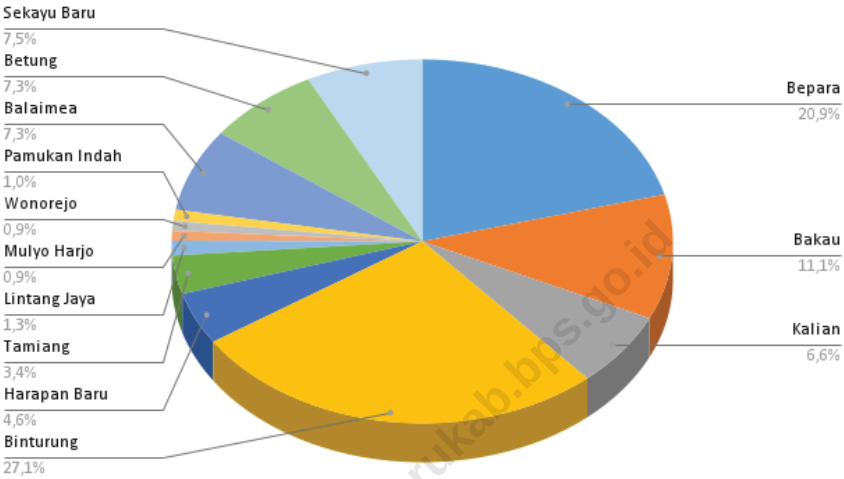

Sumber : Sekretariat Daerah Kabupaten Kotabaru

https://kotabarukab.bps.go.id

Gambar 1.2 Jarak ke Ibukota Kecamatan Menurut Desa/Kelurahan di Kecamatan Pamukan Utara(km), 2023

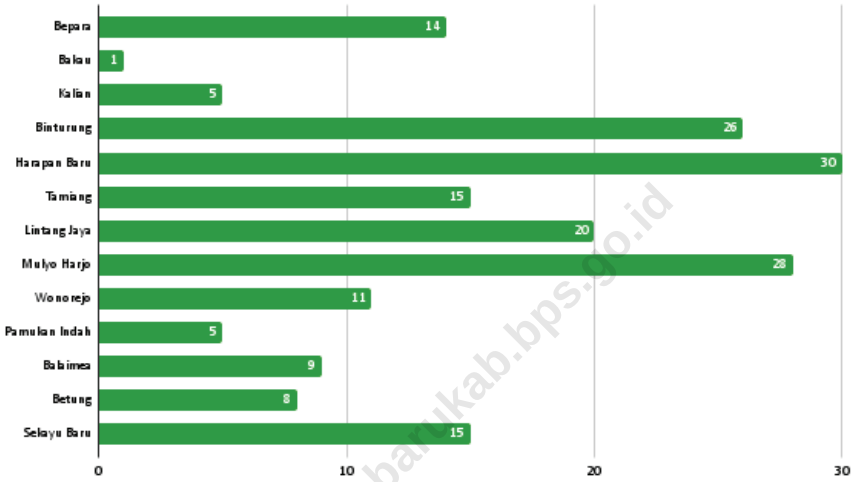

Sumber: Badan Pusat Statistik, Pendataan Potensi Desa (PODES), 2021

https://kotabarukab.bps.go.id

Tabel 1.1 Luas Daerah Menurut Desa/Kelurahan di Kecamatan Pamukan Utara, 2023

Desa/Kelurahan	Luas (km^2)	Persentase terhadap Luas Kecamatan
(1)	(2)	(3)
Bepara	119,36	20,86
Bakau	63,46	11,09
Kalian	37,90	6,62
Binturung	155,33	27,14
Harapan Baru	26,53	4,63
Tamiang	19,59	3,42
Lintang Jaya	7,51	1,31
Mulyo Harjo	4,94	0,86
Wonorejo	5,00	0,87
Pamukan Indah	5,63	0,98
Balaimea	42,00	7,34
Betung	42,00	7,34
Sekayu Baru	43,11	7,53
Kecamatan Pamukan Utara	**572,36**	**100,00**

Catatan: ...
Sumber: Sekretariat Daerah Kabupaten Kotabaru

https://kotabarukab.bps.go.id

Tabel 1.2 Jarak ke Ibukota Kecamatan dan Ibukota Kabupaten/Kota Menurut Desa/Kelurahan di Kecamatan Pamukan Utara (km), 2023

Desa/Kelurahan	Jarak ke Ibukota Kecamatan	Jarak ke Ibukota Kabupaten/ Kota
(1)	(2)	(3)
Bepara	14	261
Bakau	1	275
Kalian	5	279
Binturung	26	296
Harapan Baru	30	273
Tamiang	15	385
Lintang Jaya	20	291
Mulyo Harjo	28	282
Wonorejo	11	278
Pamukan Indah	5	276
Balaimea	9	278
Betung	8	268
Sekayu Baru	15	260

https://kotabarukab.bps.go.id

Catatan: ...
Sumber: Badan Pusat Statistik, Pendataan Potensi Desa (PODES), 2021

https://kotabarukab.bps.go.id

BAB II
PEMERINTAHAN

/pe.me.rin.ta.han/

organisasi atau wadah orang yang mempunyai kekuasaaan dan lembaga yang mengurus masalah kenegaraan dan kesejahteraan rakyat dan negara

#GOVERNMENT

https://kotabarukab.bps.go.id

ULASAN

KKecamatan Pamukan Utara terdiri dari rukun tangga (RT) dan rukun warga (RW)/dusun yang berjumlah masing-masing 91 dan 23. Rata-rata dalam satu desa terdapat sekitar 7 RT serta 1 hingga 2 RW/dusun. RT terbanyak di Kecamatan Pamukan Utara berada di Desa Bepara dan Binturung, yaitu berjumlah 16 RT.

https://kotabarukab.bps.go.id

Tabel 2.1 Jumlah Rukun Warga (RW)/Dusun dan Rukun Tetangga (RT) Menurut Desa/Kelurahan di Kecamatan Pamukan Utara, 2023

Desa/Kelurahan	Rukun Warga (RW)/Dusun	Rukun Tetangga (RT)
(1)	(2)	(3)
Bepara	3	16
Bakau	2	8
Kalian	1	3
Binturung	–	16
Harapan Baru	2	4
Tamiang	1	3
Lintang Jaya	2	6
Mulyo Harjo	2	10
Wonorejo	2	6
Pamukan Indah	2	4
Balaimea	2	5
Betung	2	6
Sekayu Baru	2	4
Kecamatan Pamukan Utara	**23**	**91**

Catatan: ...
Sumber: Kantor Kecamatan Pamukan Utara

https://kotabarukab.bps.go.id

BAB III
PENDUDUK

/pen.du.duk/

semua orang yang berdomisili di wilayah geografis Republik Indonesia selama 6 bulan atau lebih dan atau mereka yang berdomisili kurang dari 6 bulan tetapi bertujuan untuk menetap

#POPULATION

https://jambi.bps.go.id

https://kotabarukab.bps.go.id

ULASAN

Kecamatan Pamukan Utara memiliki jumlah penduduk sebanyak 14.756 orang, dengan 52,34% berjenis kelamin Laki-laki dan 47,66% berjenis kelamin Perempuan. Kecamatan Pamukan Utara memiliki penduduk terbanyak pada Desa Binturung dengan 20,29% dari total penduduk Kecamatan Pamukan Utara berada di desa ini. Kepadatan penduduk tertinggi berada pada di Desa Mulyo Harjo dengan kepadatan penduduk sebesar 215 hingga 216 jiwa per Kilometer Persegi.

https://kotabarukab.bps.go.id

Gambar 3.1 Jumlah Penduduk Menurut Desa/Kelurahan di Kecamatan Pamukan Utara, 2023

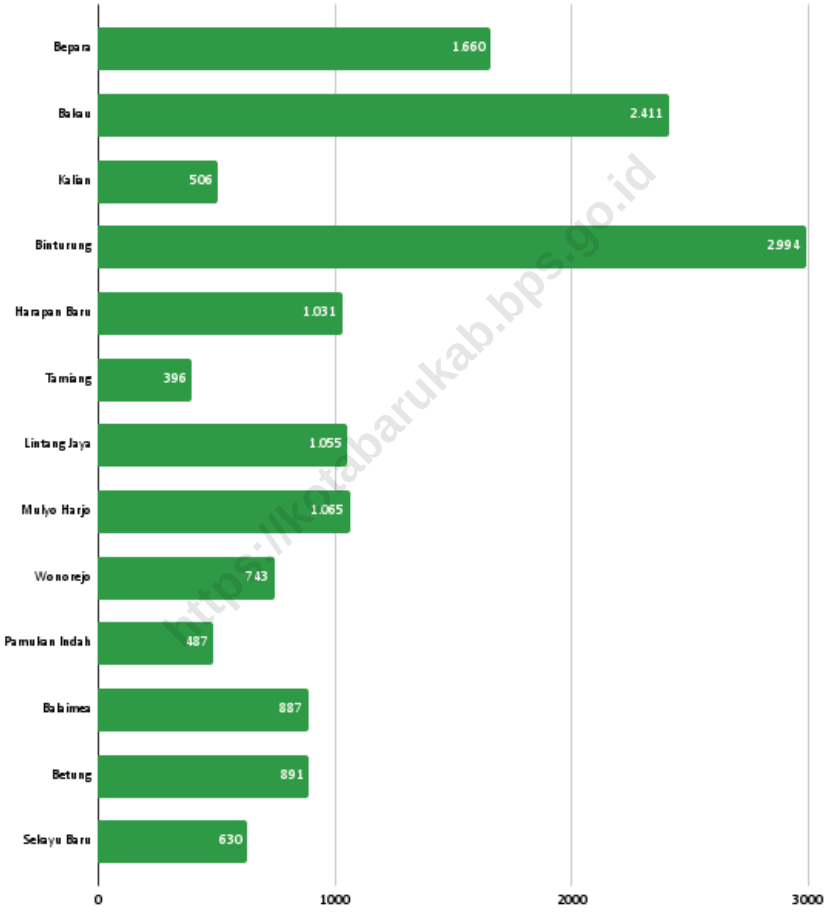

https://kotabarukab.bps.go.id

Sumber: Dinas Kependudukan dan Pencatatan Sipil Kabupaten Kotabaru

Tabel 3.1 Penduduk, Distribusi Persentase Penduduk, Kepadatan Penduduk, Rasio Jenis Kelamin Penduduk Menurut Desa/ Kelurahan di Kecamatan Pamukan Utara, 2023

Desa/Kelurahan	Penduduk		
	Laki-Laki	Perempuan	Jumlah
(1)	(2)	(3)	(4)
Bepara	903	757	1.660
Bakau	1.227	1.184	2.411
Kalian	265	241	506
Binturung	1.552	1.442	2.994
Harapan Baru	541	490	1.031
Tamiang	214	182	396
Lintang Jaya	549	506	1.055
Mulyo Harjo	553	512	1.065
Wonorejo	372	371	743
Pamukan Indah	259	228	487
Balaimea	475	412	887
Betung	481	410	891
Sekayu Baru	333	297	630
Kecamatan Pamukan Utara	**7.724**	**7.032**	**14.756**

https://kotabarukab.bps.go.id

Lanjutan Tabel/*Continued Table* 3.1

Desa/Kelurahan	Persentase Penduduk	Kepadatan Penduduk (per km^2)	Rasio Jenis Kelamin Penduduk
(1)	(5)	(6)	(7)
Bepara	11,25	13,91	1,19
Bakau	16,34	37,99	1,04
Kalian	3,43	13,35	1,10
Binturung	20,29	19,28	1,08
Harapan Baru	6,98	38,87	1,10
Tamiang	2,68	20,21	1,18
Lintang Jaya	7,15	140,42	1,08
Mulyo Harjo	7,22	215,52	1,08
Wonorejo	5,04	148,54	1,00
Pamukan Indah	3,3	86,49	1,14
Balaimea	6,01	21,12	1,15
Betung	6,04	21,22	1,17
Sekayu Baru	4,27	14,61	1,12
Kecamatan Pamukan Utara	**100,00**	**25,78**	**1,10**

Catatan: ...
Sumber: Dinas Kependudukan dan Pencatatan Sipil Kabupaten Kotabaru

https://kotabarukab.bps.go.id

BAB IV
SOSIAL DAN KESEJAHTERAAN RAKYAT

/so.si.al/

segala hal yang berkenaan dengan masyarakat

#SOCIAL & WALFARE

haruskab.bps.go.id

https://kotabarukab.bps.go.id

ULASAN

Kecamatan Pamukan Utara memiliki 32 (tiga puluh dua) sekolah yang terdaftar, dimana jumlah tersebut terdiri dari 8 (delapan) Taman Kanak-Kanak (TK), 18 (delapan belas) Sekolah Dasar (SD), 5 (lima) Sekolah Menengah Pertama (SMP), dan 1 (satu) Sekolah Menengah Atas (SMK). Selain itu, Kecamatan Pamukan Utara memiliki tenaga pendidik sejumlah 280 (dua ratus delapan puluh) orang dan murid 3.187 (tiga ribu seratus delapan puluh tujuh) anak. Kecamatan Pamukan Utara memiliki 6 (enam) poliklinik/balai pengobatan, 1 (satu) puskesmas rawat inap, dan 1 (satu) puskesmas tanpa rawat inap. Terdapat 4 (empat) desa yang sudah dialiri Listrik Pemerintah dan 2 (dua) desa yang dialiri Listrik Non-Pemerintah sebagai sumber penerangan jalan utama. Kecamatan Pamukan Utara juga memiliki 14 (empat belas) Mesjid, 11 (sebelas) Musholla, dan 2 (dua) Gereja Protestan.

https://kotabarukab.bps.go.id

4.1 PENDIDIKAN

Tabel 4.1.1 Banyaknya Desa[1]/Kelurahan yang Memiliki Fasilitas Sekolah Menurut Tingkat Pendidikan di Kecamatan Pamukan Utara, 2021–2023

Tingkat Pendidikan	2021[2]	2022[3]	2023[3]
(1)	(2)	(3)	(4)
Sekolah Dasar (SD)	12	12	12
Madrasah Ibtidaiyah (MI)	–	–	–
Sekolah Menengah Pertama (SMP)	5	5	5
Madrasah Tsanawiyah (MTs)	1	–	–
Sekolah Menengah Atas (SMA)	1	1	1
Sekolah Menengah Kejuruan (SMK)	1	1	1
Madrasah Aliyah (MA)	–	–	–
Akademi/Perguruan Tinggi	–	–	–

https://kotabarukab.bps.go.id

Catatan: [1] Desa pada tabel ini termasuk Unit Permukiman Transmigrasi (UPT) yang masih dibina oleh kementerian terkait
Sumber: [2] Badan Pusat Statistik, Pendataan Potensi Desa (Podes)
[3] Dinas Pendidikan Kabupaten Kotabaru dan Kementerian Agama Kabupaten Kotabaru

Tabel 4.1.2 Jumlah Sekolah Menurut Tingkat Pendidikan di Kecamatan Pamukan Utara, 2022/2023 dan 2023/2024

Tingkat Pendidikan	Negeri		Swasta		Jumlah	
	2022/2023	2023/2024	2022/2023	2023/2024	2022/2023	2023/2024
(1)	(2)	(3)	(4)	(5)	(6)	(7)
Taman Kanak-Kanak (TK)[1]	1	1	7	7	8	8
Raudatul Athfal (RA)[2]	–	–	–	–	–	–
Sekolah Dasar (SD)[1]	11	11	7	7	18	18
Madrasah Ibtidaiyah (MI)[2]	–	–	–	–	–	–
Sekolah Menengah Pertama (SMP)[1]	3	2	3	2	5	5
Madrasah Tsanawiyah (MTs)[2]	–	–	–	–	–	–
Sekolah Menengah Atas (SMA)[1]	1	–	1	–	1	–
Sekolah Menengah Kejuruan (SMK)[1]	–	–	1	1	1	1
Madrasah Aliyah (MA)[2]	–	–	–	–	–	–

Catatan: [3] Seluruh Raudatul Athfal (RA) berstatus swasta

Sumber: [1] Kementerian Pendidikan, Kebudayaan, Riset, dan Teknologi, Sistem Data Pokok Pendidikan (2022/2023) dan Dinas Pendidikan Kabupaten Kotaabru (2023/2024), data semester genap

[2] Kementerian Agama, EMIS, data semester genap

https://kotabarukab.bps.go.id

Tabel 4.1.3 Jumlah Guru Menurut Tingkat Pendidikan di Kecamatan Pamukan Utara, 2022/2023 dan 2023/2024

Tingkat Pendidikan	Negeri		Swasta		Jumlah	
	2022/2023	2023/2024	2022/2023	2023/2024	2022/2023	2023/2024
(1)	(2)	(3)	(4)	(5)	(6)	(7)
Taman Kanak-Kanak (TK)[1]	4	5	18	20	22	25
Raudatul Athfal (RA)[2]	–	–	–	–	–	–
Sekolah Dasar (SD)[1,3]	84	88	54	63	138	151
Madrasah Ibtidaiyah (MI)[2]	–	–	–	–	–	–
Sekolah Menengah Pertama (SMP)[1,3]	32	41	19	22	51	63
Madrasah Tsanawiyah (MTs)[2]	–	–	–	–	–	–
Sekolah Menengah Atas (SMA)[1,3]	17	17	–	–	17	17
Sekolah Menengah Kejuruan (SMK)[1,3]	–	23	20	–	20	23
Madrasah Aliyah (MA)[2]	–	–	–	–	–	–

Catatan: [3] Jumlah guru termasuk kepala sekolah dan guru

Sumber: [1] Kementerian Pendidikan, Kebudayaan, Riset, dan Teknologi, Sistem Data Pokok Pendidikan (2022/2023) dan Dinas Pendidikan Kabupaten Kotaabru (2023/2024), data semester genap

[2] Kementerian Agama, EMIS, data semester genap

https://kotabarukab.bps.go.id

Tabel 4.1.4 Jumlah Murid Menurut Tingkat Pendidikan di Kecamatan Pamukan Utara, 2022/2023 dan 2023/2024

Tingkat Pendidikan	Negeri		Swasta		Jumlah	
	2022/2023	2023/2024	2022/2023	2023/2024	2022/2023	2023/2024
(1)	(2)	(3)	(4)	(5)	(6)	(7)
Taman Kanak-Kanak (TK)[1]	39	49	269	328	308	377
Raudatul Athfal (RA)[2]	–	–	–	–	–	–
Sekolah Dasar (SD)[1]	719	726	943	920	1662	1646
Madrasah Ibtidaiyah (MI)[2]	–	–	–	–	–	–
Sekolah Menengah Pertama (SMP)[1]	348	344	280	305	628	649
Madrasah Tsanawiyah (MTs)[2]	–	–	–	–	–	–
Sekolah Menengah Atas (SMA)[1]	235	235	–	–	235	235
Sekolah Menengah Kejuruan (SMK)[1]	–	–	275	280	275	280
Madrasah Aliyah (MA)[2]	–	–	–	–	–	–

Catatan: ...

Sumber: [1] Kementerian Pendidikan, Kebudayaan, Riset, dan Teknologi, Sistem Data Pokok Pendidikan (2022/2023) dan Dinas Pendidikan Kabupaten Kotaabru (2023/2024), data semester genap
[2] Kementerian Agama, EMIS, data semester genap

https://kotabarukab.bpssigo.id

4.2 KESEHATAN

Tabel 4.2.1 Banyaknya Desa[1]/Kelurahan yang Memiliki Sarana Kesehatan Menurut Jenis Sarana Kesehatan di Kecamatan Pamukan Utara, 2021-2023

Jenis Sarana Kesehatan	2021[2]	2022	2023
(1)	(2)	(3)	(4)
Rumah Sakit	–	...	...
Rumah Sakit Bersalin	–	–	–
Poliklinik/Balai Pengobatan	6	6	6
Puskesmas Rawat Inap	1	1	1
Puskesmas Tanpa Rawat Inap	1	1	1
Apotek	–	...	...

Catatan: [1] Desa pada tabel ini termasuk Unit Permukiman Transmigrasi (UPT) yang masih dibina oleh kementerian terkait
Sumber: [2] Badan Pusat Statistik, Pendataan Potensi Desa (Podes)

https://kotabarukab.bps.go.id

4.3 PERUMAHAN DAN LINGKUNGAN

Tabel 4.3.1 Banyaknya Desa[1]/Kelurahan Menurut Sumber Air Minum Sebagian Besar Keluarga di Kecamatan Pamukan Utara, 2021–2023

Sumber Air Minum	2021[2]	2022	2023
(1)	(2)	(3)	(4)
Air Kemasan Bermerk	–	–	–
Air Isi Ulang	1	–	–
Leding Dengan Meteran	2	2	2
Leding Tanpa Meteran	–	–	–
Sumur Bor atau Pompa	–	–	–
Sumur	7	5	5
Mata Air	–	–	–
Sungai/Danau/Kolam/ Waduk/Situ/ Embung/Bendungan	3	6	6
Air Hujan	–	–	–
Lainnya	–	–	–

Catatan: [1] Desa pada tabel ini termasuk Unit Permukiman Transmigrasi (UPT) yang masih dibina oleh kementerian terkait
Sumber: [2] Badan Pusat Statistik, Pendataan Potensi Desa (Podes)

https://kotabarukab.bps.go.id

Tabel 4.3.2 Banyaknya Desa[1]/Kelurahan Menurut Sumber Penerangan Jalan Utama Desa/Kelurahan di Kecamatan Pamukan Utara, 2021–2023

Sumber Penerangan Jalan Utama	2021[2]	2022	2023
(1)	(2)	(3)	(4)
Listrik Pemerintah	2	3	4
Listrik Non-Pemerintah	6	10	2
Non Listrik	5	–	0

Catatan: [1] Desa pada tabel ini termasuk Unit Permukiman Transmigrasi (UPT) yang masih dibina oleh kementerian terkait
Sumber: [2] Badan Pusat Statistik, Pendataan Potensi Desa (Podes)

https://kotabarukab.bps.go.id

Tabel 4.3.3 Banyaknya Desa[1]/Kelurahan Menurut Penggunaan Fasilitas Tempat Buang Air Besar Sebagian Besar Keluarga di Kecamatan Pamukan Utara, 2021–2023

Fasilitas Tempat Buang Air Besar	2021[2]	2022	2023
(1)	(2)	(3)	(4)
Jamban			
Sendiri	13	13	13
Bersama	–	–	–
Umum	–	–	–
Bukan Jamban	–	–	–
Jumlah	**13**	**13**	**13**

Catatan: [1] Desa pada tabel ini termasuk Unit Permukiman Transmigrasi (UPT) yang masih dibina oleh kementerian terkait
Sumber: [2] Badan Pusat Statistik, Pendataan Potensi Desa (Podes)

https://kotabarukab.bps.go.id

4.4 AGAMA DAN SOSIAL LAINNYA

Tabel 4.4.1 Jumlah Tempat Peribadatan Menurut Desa/Kelurahan di Kecamatan Pamukan Utara, 2023

Desa/Kelurahan	Masjid	Mushola	Gereja Protestan	Gereja Katholik	Pura	Vihara
(1)	(2)	(3)	(4)	(5)	(6)	(7)
Bepara	1	–	1	–	–	–
Bakau	2	2	1	–	–	–
Kalian	1	–	–	–	–	–
Binturung	2	3	–	–	–	–
Harapan Baru	1	–	–	–	–	–
Tamiang	2	–	–	–	–	–
Lintang Jaya	1	5	–	–	–	–
Mulyo Harjo	1	2	–	–	–	–
Wonorejo	1	3	–	–	–	–
Pamukan Indah	1	2	–	–	–	–
Balaimea	–	–	–	–	–	–
Betung	–	–	–	–	–	–
Sekayu Baru	1	–	–	–	–	–
Kecamatan Pamukan Utara	**14**	**17**	**2**	**–**	**–**	**–**

Catatan: ...
Sumber: Kementerian Agama Kabupaten Kotabaru

https://kotabarukab.bps.go.id

Tabel 4.4.2 Jumlah Penduduk Menurut Desa/Kelurahan dan Agama yang Dianut di Kecamatan Pamukan Utara, 2023

Desa/Kelurahan	Islam	Protestan	Katolik	Hindu	Budha	Lainnya
(1)	(2)	(3)	(4)	(5)	(6)	(7)
Bepara	949	355	166	145	1	44
Bakau	2.284	85	40	1	–	1
Kalian	506	–	–	–	–	–
Binturung	2.538	325	110	6	–	15
Harapan Baru	1.012	–	19	–	–	–
Tamiang	396	–	–	–	–	–
Lintang Jaya	1.046	8	1	–	–	–
Mulyo Harjo	1.059	6	–	–	–	–
Wonorejo	722	17	4	–	–	–
Pamukan Indah	480	7	–	–	–	–
Balaimea	423	115	154	89	–	106
Betung	324	442	9	30	1	85
Sekayu Baru	596	8	4	–	2	20
Kecamatan Pamukan Utara	**12.335**	**1.368**	**507**	**271**	**4**	**271**

Catatan: ...
Sumber: Dinas Kependudukan dan Pencatatan Sipil Kabupaten Kotabaru

https://kotabarukab.bps.go.id

https://kotabarukab.bps.go.id

BAB V
PERTANIAN

/per.ta.ni.an/

pertanian mencakup usaha di subsektor tanaman pangan, hortikultura, perkebunan, peternakan, perikanan, kehutanan, serta usaha jasa pertanian

https://kotabaru.kalsel.bps.go.id

#AGRICULTURE

https://kotabarukab.bps.go.id

ULASAN

Sektor pertanian menjadi salah satu mata pencaharian penduduk di Kecamatan Pamukan Utara. Sektor pertanian tersebut mencakup tanaman sayuran dan buah-buah semusim maupun tahunan. Hingga saat ini, tanaman biofarmaka dan tanaman hias masih belum dibudidaya atau diproduksi di wilayah Kecamatan Pamukan Utara. Salah satu komoditas dengan panen terluas pada tahun 2023 adalah cabai rawit, yaitu sekitar 3,75 hektar. Sementara buah semangka menjadi salah satu komoditas Kecamatan Pamukan Utara dengan volume produksi yang tinggi, yaitu sekitar 14,01 kuintal. Untuk tanaman tahunan, buah pisang menjadi salah satu komoditas dengan volume produksi yang tinggi dibandingkan komoditas yang lainnya, yaitu sekitar 1.036,63 kuintal.

https://kotabarukab.bps.go.id

Tabel 5.1 Luas Panen Tanaman Sayuran dan Buah-buahan Semusim Menurut Jenis Tanaman di Kecamatan Pamukan Utara (ha), 2020–2023

Jenis Tanaman	2020	2021	2022	2023
(1)	(2)	(3)	(4)	(5)
Sayuran:				
Bawang Merah	–	–	–	–
Cabai Besar/TW/Teropong	–	1,00	–	–
Cabai Keriting	–	–	–	–
Cabai Rawit	5,00	5,00	5,00	3,75
Kentang	...	–	–	–
Kubis	...	–	–	–
Tomat	–	–	–	1,00
Bawang Putih	...	–	–	–
Kangkung	12,00	12,00	9,00	–
Bayam	12,00	12,00	9,00	–
Buah–buahan:				
Melon	...	–	–	–
Semangka	–	–	–	0,03

Catatan: ...
Sumber: Badan Pusat Statistik, Statistik Pertanian Hortikultura SPH-SBS

https://kotabarukab.bps.go.id

Tabel 5.2 Produksi Tanaman Sayuran dan Buah-buahan Semusim Menurut Jenis Tanaman di Kecamatan Pamukan Utara (kuintal), 2020–2023

Jenis Tanaman	2020	2021	2022	2023
(1)	(2)	(3)	(4)	(5)
Sayuran:				
Bawang Merah	–	–	–	–
Cabai Besar/TW/Teropong	–	65,00	–	–
Cabai Keriting	–	–	–	–
Cabai Rawit	271,00	368,00	231,60	63,83
Kentang	...	–	–	–
Kubis	...	–	–	–
Tomat	–	–	–	3,00
Bawang Putih	...	–	–	–
Kangkung	316,00	407,00	212,50	–
Bayam	634,00	545,00	280,00	–
Buah–buahan:				
Melon	...	–	–	–
Semangka	–	–	–	14,01

Catatan: ...
Sumber: Badan Pusat Statistik, Statistik Pertanian Hortikultura SPH-SBS

https://kotabarukab.bps.go.id

Tabel 5.3 Luas Panen Tanaman Biofarmaka Menurut Jenis Tanaman di Kecamatan Pamukan Utara (m^2), 2020–2023

Jenis Tanaman	2020	2021	2022	2023
(1)	(2)	(3)	(4)	(5)
Jahe	–	–	–	–
Laos/Lengkuas	–	–	–	–
Kencur	–	–	–	–
Kunyit	–	–	–	–
Lidah Buaya	–	–	–	–

Catatan: ...
Sumber: Badan Pusat Statistik, Statistik Pertanian Hortikultura SPH-TBF

https://kotaberukab.bps.go.id

Tabel 5.4 Produksi Tanaman Biofarmaka Menurut Jenis Tanaman di Kecamatan Pamukan Utara (kg), 2020–2023

Jenis Tanaman	2020	2021	2022	2023
(1)	(2)	(3)	(4)	(5)
Jahe	–	–	–	–
Laos/Lengkuas	–	–	–	–
Kencur	–	–	–	–
Kunyit	–	–	–	–
Lidah Buaya	–	–	–	–

Catatan: ...
Sumber: Badan Pusat Statistik, Statistik Pertanian Hortikultura SPH-TBF

https://kotabarukab.bps.go.id

Tabel 5.5 Luas Panen Tanaman Hias Menurut Jenis Tanaman di Kecamatan Pamukan Utara (m^2), 2020–2023

Jenis Tanaman	2020	2021	2022	2023
(1)	(2)	(3)	(4)	(5)
Anggrek Pot	–	–	–	–
Anggrek Potong	–	–	–	–
Krisan	–	–	–	–
Mawar	–	–	–	–
Sedap Malam	–	–	–	–
Melati	–	–	–	–

Catatan: ...
Sumber: Badan Pusat Statistik, Statistik Pertanian Hortikultura SPH-TH

https://kotabarukab.bps.go.id

Tabel 5.6 Produksi Tanaman Hias Menurut Jenis Tanaman di Kecamatan Pamukan Utara (tangkai), 2020–2023

Jenis Tanaman	2020	2021	2022	2023
(1)	(2)	(3)	(4)	(5)
Anggrek Pot	–	–	–	–
Anggrek Potong	–	–	–	–
Krisan	–	–	–	–
Mawar	–	–	–	–
Sedap Malam	–	–	–	–
Melati	–	–	–	–

Catatan: ...
Sumber: Badan Pusat Statistik, Statistik Pertanian Hortikultura SPH-TH

https://kotabarukab.bps.go.id

Tabel 5.7 Produksi Buah-Buahan dan Sayuran Tahunan Menurut Jenis Tanaman di Kecamatan Pamukan Utara (kuintal), 2020–2023

Jenis Tanaman	2020	2021	2022	2023
(1)	(2)	(3)	(4)	(5)
Buah–Buahan:				
Mangga	...	37,71	72	–
Durian	...	15	24	18
Jeruk Siam/Keprok	...	–	–	–
Pisang	...	584,27	1.668,23	1.036,63
Pepaya	...	131,46	77,50	40
Salak	...	1	3,14	0,5
Rambutan	...	48.2	75,60	20
Nangka/Cempedak	...	77.79	55,95	28,52
Sayuran:				
Petai	...	99,79	98	2,4
Jengkol	...	25,88	–	–

Catatan: ...
Sumber: Badan Pusat Statistik, Statistik Pertanian Hortikultura SPH-BST

https://kotabarukab.bps.go.id

DAFTAR PUSTAKA

Direktorat Jenderal Hortikultura & Badan Pusat Statistik. 2022. *Pedoman Statistik Pertanian Hortikultura (SPH)*. Jakarta: Kementerian Pertanian.

Direktorat Statistik Ketahanan Sosial. 2021. *Buku 3: Konsep dan Definisi Podes 2021*. Jakarta: Badan Pusat Statistik.

https://kotabarukab.bps.go.id

https://kotabarukab.bps.go.id

https://kotabarukab.bps.go.id

ST2023
SENSUS PERTANIAN

BerAKHLAK
Berorientasi Pelayanan Akuntabel Kompeten
Harmonis Loyal Adaptif Kolaboratif

#bangga melayani bangsa

https://kotabarukab.bps.go.id

DATA
MENCERDASKAN BANGSA

ISSN 2746-735X
9 772746 735003

BADAN PUSAT STATISTIK
KABUPATEN KOTABARU
Jl. Jamrud I, Dirgahayu, Pulau Laut Utara, Kotabaru, 70242
Telp./Fax : (0518) 21145 Email : bps6302@bps.go.id
Website : kotabarukab.bps.go.id