Katalog: 1102001.6301010
ISSN 2745-8202

# KECAMATAN Panyipatan DALAM ANGKA 2024

Volume 35

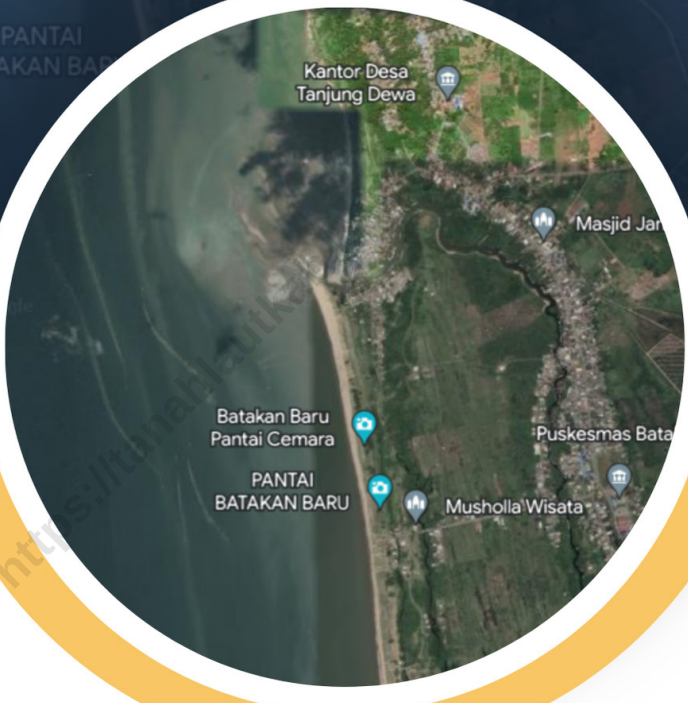


BADAN PUSAT STATISTIK
KABUPATEN TANAH LAUT

https://tanahlautkab.bps.go.id

Katalog: 1102001.6301010
ISSN 2745-8202

# KECAMATAN Panyipatan DALAM ANGKA 2024

Volume 35

https://tanahlautkab.bps.go.id

BADAN PUSAT STATISTIK
KABUPATEN TANAH LAUT

**KECAMATAN PANYIPATAN DALAM ANGKA**
**2024**
Volume 35, 2024

Katalog: 1102001.6301010
ISSN: 2745-8202
Nomor Publikasi: 63010.24011

Ukuran Buku: 14,8 cm x 21 cm
Jumlah Halaman: xxvi+122 halaman

Penyusun Naskah:
BPS Kabupaten Tanah Laut

Penyunting:
BPS Kabupaten Tanah Laut

Pembuat Kover:
BPS Kabupaten Tanah Laut

Penerbit
©BPS Kabupaten Tanah Laut

Sumber Ilustrasi: Google Earth
Dilarang mereproduksi dan/atau menggandakan sebagian atau seluruh isi buku ini untuk tujuan komersial tanpa izin tertulis dari Badan Pusat Statistik Kabupaten Tanah Laut.

https://tanahlautkab.bps.go.id

ISSN 2745-8202

# TIM PENYUSUN

## KECAMATAN PANYIPATAN DALAM ANGKA 2024

Volume 35, 2024

**Pengarah**
Siswo Widjanarko

**Penanggung Jawab**
Nurul Ni'mah

**Penyunting**
Nurul Ni'mah

**Pengolah Data dan Penulis Naskah**
Ardianto S. • Desy Rivina Maulita • Nurul Ni'mah • Surhaliza Aprilianti

**Penata Letak**
Nurul Ni'mah

**Infografis**
Nurul Ni'mah

**Kover**
Surhaliza Aprilianti

https://tanjunglautkab.bps.go.id

https://tanahlautkab.bps.go.id

## KONTRIBUTOR DATA

1. Kementerian Agama
2. Kementerian Pendidikan dan Kebudayaan
3. Badan Pusat Statistik
4. Sekretariat Daerah Kabupaten Tanah Laut
5. Dinas Kependudukan dan Pencatatan Sipil Kabupaten Tanah Laut
6. Dinas Tanaman Pangan, Hortikultura, dan Perkebunan
7. Pengadilan Agama Pelaihari
8. Dinas Peternakan dan Kesehatan Hewan
9. Badan Keuangan Daerah Unit Pelayanan Pendapatan Daerah Pelaihari
10. Kantor Kecamatan
11. Kantor Desa
12. Kepolisian Resor Tanah Laut
13. Kepolisian Sektor
14. Dinas Pengendalian Penduduk, Keluarga Berencana, Pemberdayaan Perempuan dan Perlindungan Anak Kabupaten Tanah Laut

https://tanahlautkab.bps.go.id

https://tanahlautkab.bps.go.id

# PETA WILAYAH KECAMATAN PANYIPATAN

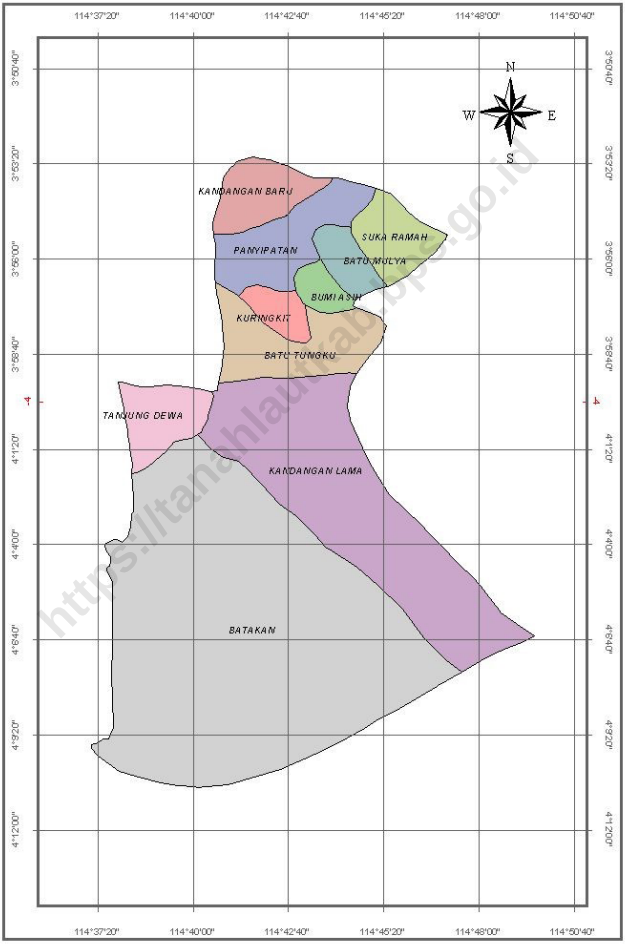

https://tanahlautkab.bps.go.id

https://tanahlautkab.bps.go.id

**KEPALA BPS KABUPATEN TANAH LAUT**

**SISWO WIDJANARKO**

https://tanahlautkab.bps.go.id

# KATA PENGANTAR

Puji syukur kami panjatkan ke hadirat Tuhan Yang Maha Esa atas segala rahmat dan karunia-Nya sehingga publikasi "Kecamatan Panyipatan dalam Angka 2024" ini dapat diselesaikan dengan baik. Publikasi ini merupakan hasil kerja keras dan kerjasama dari berbagai pihak yang telah memberikan kontribusi dalam pengumpulan, pengolahan, dan penyajian data.

Publikasi ini menyajikan berbagai macam data dan informasi mengenai keadaan geografis, demografi, sosial, dan ekonomi di Kecamatan Panyipatan. Data yang disajikan dalam publikasi ini diperoleh dari berbagai sumber, termasuk survei yang dilakukan oleh Badan Pusat Statistik (BPS) serta kompilasi data dari instansi pemerintah.

Kami berharap publikasi ini dapat menjadi sumber informasi yang bermanfaat bagi para pengguna data, baik dari kalangan pemerintah, akademisi, maupun masyarakat umum. Kami juga menyadari bahwa publikasi ini masih memiliki kekurangan dan keterbatasan. Oleh karena itu, kami sangat mengharapkan masukan dan saran yang konstruktif untuk perbaikan di masa mendatang.

Akhir kata, kami mengucapkan terima kasih kepada semua pihak yang telah membantu dalam penyusunan publikasi ini. Semoga publikasi ini dapat memberikan manfaat yang sebesar-besarnya bagi pembangunan dan kesejahteraan masyarakat di Kecamatan Panyipatan.

Pelaihari , September 2024
Kepala BPS
Kabupaten Tanah Laut

**Siswo Widjanarko**

https://tanahlautkab.bps.go.id

https://tanahlautkab.bps.go.id

ISSN 2745-8202

# DAFTAR ISI

**KECAMATAN PANYIPATAN DALAM ANGKA**
**2024**
Volume 35, 2024

Halaman


Kata Pengantar ..... xi
Daftar Isi ..... xiii
Daftar Tabel ..... xv
Daftar Gambar ..... xxi
Penjelasan Umum ..... xxiii
Daftar Singkatan ..... xxv
1. Geografi ..... 1
2. Pemerintahan ..... 11
3. Penduduk ..... 31
4. Sosial dan Kesejahteraan Rakyat ..... 39
5. Pertanian ..... 77
6. Pariwisata, Transportasi, dan Komunikasi ..... 97
7. Perbankan, Koperasi, dan Perdagangan ..... 109
Daftar Pustaka ..... 121


https://tanahlautkab.bps.go.id

https://tanahlautkab.bps.go.id

# DAFTAR TABEL

Tabel Halaman


**1. GEOGRAFI**

**1.1 KEADAAN GEOGRAFI**

1.1.1 Luas Daerah Menurut Desa/Kelurahan di Kecamatan Panyipatan, 2023 ..... 8

1.1.2 Jarak ke Ibukota Kecamatan dan Ibukota Kabupaten/Kota Menurut Desa/Kelurahan di Kecamatan Panyipatan (km), 2023 ..... 9

**2. PEMERINTAHAN**

**2.1 WILAYAH ADMINISTRATIF**

2.1.1 Jumlah Rukun Warga (RW) dan Rukun Tetangga (RT) Menurut Desa/Kelurahan di Kecamatan Panyipatan, 2023 ..... 16

2.1.2 Nama Camat/Kepala Wilayah Kecamatan Panyipatan, 1983-2023 ..... 17

2.1.3 Nama Kepala Desa di Kecamatan Panyipatan, 2023 ..... 18

2.1.4 Jumlah Anggota Badan Permusyawaratan Desa (BPD) di Kecamatan Panyipatan, 2023 ..... 19

2.1.5 Nama Ketua RT di Desa Batakan, 2023 ..... 20

2.1.6 Nama Ketua RT di Desa Tanjung Dewa, 2023 ..... 21

2.1.7 Nama Ketua RT di Desa Kandangan Lama, 2023 ..... 22

2.1.8 Nama Ketua RT di Desa Batu Tungku, 2023 ..... 23

2.1.9 Nama Ketua RT di Desa Kuringkit, 2023 ..... 24

2.1.10 Nama Ketua RT di Desa Bumi Asih, 2023 ..... 25

2.1.11 Nama Ketua RT di Desa Batu Mulya, 2023 ..... 26

2.1.12 Nama Ketua RT di Desa Suka Ramah, 2023 ..... 27

2.1.13 Nama Ketua RT di Desa Panyipatan, 2023 ..... 28

2.1.14 Nama Ketua RT di Desa Kandangan Baru, 2023 ..... 29


https://tanahbumbukab.bps.go.id

Tabel Halaman


**3. PENDUDUK**

3.1 Penduduk, Distribusi Persentase Penduduk, Kepadatan Penduduk, Rasio Jenis Kelamin Penduduk Menurut Desa/Kelurahan di Kecamatan Panyipatan, 2023 ..... 36

**4. SOSIAL DAN KESEJAHTERAAN RAKYAT**

**4.1 PENDIDIKAN**

4.1.1 Banyaknya Desa[1]/Kelurahan yang Memiliki Fasilitas Sekolah Menurut Tingkat Pendidikan di Kecamatan Panyipatan, 2021–2023 ..... 48

4.1.2 Jumlah Sekolah Menurut Tingkat Pendidikan di Kecamatan Panyipatan, 2023/2024 ..... 49

4.1.3 Jumlah Guru Menurut Tingkat Pendidikan di Kecamatan Panyipatan, 2023/2024 ..... 50

4.1.4 Jumlah Murid Menurut Tingkat Pendidikan di Kecamatan Panyipatan, 2023/2024 ..... 51

**4.2 KESEHATAN**

4.2.1 Banyaknya Desa[1]/Kelurahan yang Memiliki Sarana Kesehatan Menurut Jenis Sarana Kesehatan di Kecamatan Panyipatan, 2021–2023 ..... 52

4.2.2 Banyaknya Warga Penderita Kekurangan Gizi Menurut Desa/Kelurahan di Kecamatan Panyipatan, 2023 ..... 53

4.2.3 Jumlah Rumah Sakit Umum, Rumah Sakit Khusus, dan Puskesmas Menurut Desa/Kelurahan di Kecamatan Panyipatan, 2023 ..... 54

4.2.4 Banyaknya Tenaga Kesehatan Menurut Desa/Kelurahan di Kecamatan Panyipatan, 2023 ..... 55

4.2.5 Banyaknya Wanita Usia Subur (WUS) 15–49 Tahun, Pasangan Usia Subur (PUS) Dan Peserta Keluarga Berencana (KB) Menurut Desa/kelurahan di Kecamatan Panyipatan, 2023 ..... 56

**4.3 PERUMAHAN DAN LINGKUNGAN**

4.3.1 Banyaknya Desa[1]/Kelurahan Menurut Sumber Air Minum Sebagian Besar Keluarga di Kecamatan Panyipatan, 2021–2023 ..... 57


https://tanahbumkab.bps.go.id

Tabel Halaman


4.3.2 Banyaknya Keluarga Menurut Desa/Kelurahan dan Jenis Pengguna Listrik di Kecamatan Panyipatan, 2023 ..... 58

4.3.3 Banyaknya Desa/Kelurahan Menurut Sumber Penerangan Jalan Utama Desa/Kelurahan di Kecamatan Panyipatan, 2021–2023..... 59

4.3.4 Banyaknya Desa/Kelurahan Menurut Penggunaan Fasilitas Tempat Buang Air Besar Sebagian Besar Keluarga di Kecamatan Panyipatan, 2021–2023 ..... 60

4.3.5 Banyaknya Desa/Kelurahan Menurut Jenis Bahan Bakar untuk Memasak yang Digunakan Sebagian Besar Keluarga di Kecamatan Panyipatan, 2023..... 61

**4.4 AGAMA DAN SOSIAL LAINNYA**

4.4.1 Jumlah Tempat Peribadatan Menurut Desa/Kelurahan di Kecamatan Panyipatan, 2023 ..... 62

4.4.2 Banyaknya Kejadian Bencana Alam Menurut Desa/Kelurahan dan Jenis Bencana Alam di Kecamatan Panyipatan, 2023..... 63

4.4.3 Banyaknya Korban Jiwa Akibat Bencana Alam Menurut Desa/Kelurahan dan Jenis Bencana Alam di Kecamatan Panyipatan, 2023 ..... 66

4.4.4 Keberadaan Fasilitas/Upaya Antisipasi/Mitigasi Bencana Alam Menurut Desa/Kelurahan di Kecamatan Panyipatan, 2023..... 69

4.4.5 Banyaknya Desa/Kelurahan yang Memiliki Kelompok Kegiatan Olahraga Menurut Jenis Olahraga dan Ketersedian Fasilitas/Lapangan Olahraga di Kecamatan Panyipatan, 2023..... 71

4.4.6 Banyaknya Perkara Kejahatan/Pelanggaran yang Dilaporkan ke Kepolisian dan yang Diselesaikan di Kecamatan Panyipatan, 2023. 72

4.4.7 Jumlah Pondok Pesantren, Jumlah Santri dan Guru/Kyai Menurut Desa/Kelurahan di Kecamatan Panyipatan, 2023 ..... 73

4.4.8 Jumlah Penduduk Menurut Desa/Kelurahan dan Agama yang Dianut di Kecamatan Panyipatan, 2023..... 74

4.4.9 Banyaknya Nikah, Talak, Cerai, dan Rujuk Menurut Desa/Kelurahan di Kecamatan Panyipatan, 2023 ..... 75

4.4.10 Banyaknya Nikah, Talak, Cerai, dan Rujuk Menurut Bulan di Kecamatan Panyipatan, 2023 ..... 76


https://kontulartkab.bps.go.id

Tabel Halaman

## 5. PERTANIAN


5.1 Luas Panen Tanaman Sayuran dan Buah-buahan Semusim Menurut Jenis Tanaman di Kecamatan Panyipatan (ha), 2020–2023 ..... 84

5.2 Produksi Tanaman Sayuran dan Buah-buahan Semusim Menurut Jenis Tanaman di Kecamatan Panyipatan (kuintal), 2020–2023 ..... 85

5.3 Luas Panen Tanaman Biofarmaka Menurut Jenis Tanaman di Kecamatan Panyipatan ($m^2$), 2020–2023 ..... 86

5.4 Produksi Tanaman Biofarmaka Menurut Jenis Tanaman di Kecamatan Panyipatan (kg), 2020–2023 ..... 87

5.5 Luas Panen Tanaman Hias Menurut Jenis Tanaman di Kecamatan Panyipatan ($m^2$), 2020–2023 ..... 88

5.6 Produksi Tanaman Hias Menurut Jenis Tanaman di Kecamatan Panyipatan (tangkai), 2020–2023 ..... 89

5.7 Produksi Buah-buahan dan Sayuran Tahunan Menurut Jenis Tanaman di Kecamatan Panyipatan (kuintal), 2020–2023 ..... 90

5.8 Luas Areal Tanaman Perkebunan Menurut Jenis Tanaman di Kecamatan Panyipatan (ha), 2020–2023 ..... 91

5.9 Produksi Tanaman Perkebunan Menurut Jenis Tanaman di Kecamatan Panyipatan (ton), 2020–2023 ..... 92

5.10 Populasi Unggas Menurut Jenisnya di Kecamatan Panyipatan (ekor), 2020–2023 ..... 93

5.11 Produksi Daging Ternak Unggas di Kecamatan Panyipatan (kg), 2020–2023 ..... 94

5.12 Populasi Ternak Besar dan Kecil Menurut Jenisnya di Kecamatan Panyipatan (ekor), 2020–2023 ..... 95


## 6. PARIWISATA, TRANSPORTASI, DAN KOMUNIKASI

### 6.1 PARIWISATA


6.1.1 Jumlah Sarana Akomodasi Menurut Desa/Kelurahan dan Jenis Akomodasi di Kecamatan Panyipatan, 2023 ..... 102


https://tanahbumbukab.bps.go.id

Tabel Halaman

**6.2 TRANSPORTASI**

6.2.1 Prasarana dan Sarana Transportasi Antar Desa/Kelurahan Menurut Desa/Kelurahan di Kecamatan Panyipatan, 2023 ..... 103

6.2.2 Banyaknya Kendaraan Bermotor di Kecamatan Panyipatan, 2021–2023 ..... 105

**6.3 KOMUNIKASI**

6.3.1 Keberadaan Kantor Pos/Pos Pembantu/Rumah Pos, Pos Keliling, dan Perusahaan/Agen Jasa Ekspedisi Swasta Menurut Desa/Kelurahan di Kecamatan Panyipatan, 2023 ..... 106

6.3.2 Jumlah Menara Telepon Seluler dan Operator Layanan Komunikasi Telepon Seluler Menurut Desa/Kelurahan di Kecamatan Panyipatan, 2023 ..... 107

6.3.3 Kekuatan Sinyal Telepon Seluler dan Jenis Sinyal Internet Telepon Seluler Menurut Desa/Kelurahan di Kecamatan Panyipatan, 2023 .. 108

**7. PERBANKAN, KOPERASI, DAN PERDAGANGAN**

7.1 Banyaknya Sarana Lembaga Keuangan Bank Menurut Desa/Kelurahan dan Jenis Bank di Kecamatan Panyipatan, 2023 ..... 116

7.2 Banyaknya Koperasi Aktif Menurut Menurut Desa/Kelurahan dan Jenis Koperasi di Kecamatan Panyipatan, 2023 ..... 117

7.3 Banyaknya Sarana Perdagangan Menurut Desa/Kelurahan dan Jenis Sarana Perdagangan di Kecamatan Panyipatan, 2023 ..... 119

https://tanahbumbukab.bps.go.id

https://tanahlautkab.bps.go.id

# DAFTAR GAMBAR

Gambar Halaman

1.1 Persentase Luas Desa/Kelurahan terhadap Luas Kecamatan di Kecamatan Panyipatan (persen), 2023..... 6

1.2 Jarak ke Ibukota Kecamatan Menurut Desa/Kelurahan di Kecamatan Panyipatan (km), 2023..... 7

https://tanahlautkab.bps.go.id

https://tanahlautkab.bps.go.id

# PENJELASAN UMUM

Tanda-tanda, satuan-satuan, dan lain-lainnya yang digunakan dalam publikasi ini adalah sebagai berikut:

## 1. TANDA-TANDA

| | | |
|---|---|---|
| Data tidak tersedia | : | ... |
| Tidak ada atau nol | : | - |
| Data dapat diabaikan | : | ~0 |
| Tanda decimal | : | , |
| Data tidak dapat ditampilkan | : | NA |
| Angka estimasi | : | e |
| Angka diperbaiki | : | r |
| Angka sementara | : | * |
| Angka sangat sementara | : | ** |
| Angka sangat sangat sementara | : | *** |

## 2. SATUAN

| | | |
|---|---|---|
| barel | : | 158,99 liter = 1/6,2898 $m^3$ |
| hektare (ha) | : | 10.000 $m^2$ |
| kilometer (km) | : | 1.000 meter (m) |
| knot | : | 1,8523 km/jam |
| kuintal | : | 100 kg |
| KWh | : | 1.000 Watt *hour* |
| MWh | : | 1.000 KWh |
| liter (untuk beras) | : | 0,80 kg |
| MMSCF | : | 1/35,3 $m^3$ |
| metrik ton (m.ton) | : | 0,98421 long ton = 1.000 kg |
| ons | : | 28,31 gram |
| ton | : | 1.000 kg |

Satuan lain: buah, dus, butir, helai/lembar, kaleng, batang, pulsa, ton kilometer (ton-km), jam, menit, persen (%).

Perbedaan angka di belakang koma disebabkan oleh pembulatan angka.

https://tanahlautkab.bps.go.id

https://tanahlautkab.bps.go.id

# DAFTAR SINGKATAN

| | | |
|---|---|---|
| SI | : | Stasiun Iklim |
| SMPK | : | Stasiun Meterologi Pertanian Khusus |
| t.t | : | Tempat tidur |
| BCG | : | Bacillus Calmette Guerin |
| DPT | : | Difteri, Pertusis, Tetanus |
| TT | : | Tetanus Toxoid |
| IOT | : | Industri Obat Tradisional |
| IKOT | : | Industri Kecil Obat Tradisional |
| Alkes | : | Alat kesehatan |
| PKRT | : | Perbekalan Kesehatan Rumah tangga |
| Kompl | : | Komplemen |
| IRTP | : | Industri Pangan Produksi Rumah Tangga |
| GFK | : | Gudang Farmasi Kab/Kota |
| RB | : | Rumah Bersalin |
| Pustu | : | Puskesmas pembantu |
| BP | : | Balai Pengobatan |
| TPS | : | Tempat Pembuangan Sampah Sementara |
| Jamkesmas | : | Jaminan kesehatan masyarakat miskin |
| PJKMU | : | Program Jaminan Kesehatan Masyarakat Umum |
| SIUP | : | Surat Izin Usaha Perdagangan |
| TDP | : | Tanda Daftar Perusahaan |
| API | : | Angka Pengenal Importir |

https://sorlautkab.bps.go.id

https://tanahlautkab.bps.go.id

# BAB 1
# GEOGRAFI

https://tulangbawangkab.bps.go.id

https://tanahlautkab.bps.go.id

## PENJELASAN TEKNIS

1. Secara astronomis, Kecamatan Panyipatan terletak antara 114,619°–114,825° Bujur Timur 3,88573°–4,8015° Lintang Selatan

2. Luas wilayah Kecamatan Panyipatan adalah 388,91 $km^2$ atau hanya 10,12 persen dari luas wilayah Kabupaten Tanah Laut (Berdasarkan Data Sekretariat Daerah Kabupaten Tanah Laut dan Peraturan Menteri Dalam Negeri Nomor 100.1-6117 Tahun 2022 tanggal 9 November 2022).

3. Kecamatan Panyipatan terdiri dari 10 desa, yaitu:
   - Batakan
   - Tanjung Dewa
   - Kandangan Lama
   - Batu Tungku
   - Kuringkit
   - Bumi Asih
   - Batu Mulia
   - Sukaramah
   - Panyipatan
   - Kandangan Baru

https://tanahlautkab.bps.go.id

https://tanahlautkab.bps.go.id

## ULASAN

Kecamatan Panyipatan adalah bagian dari wilayah Kabupaten Tanah Laut, yang terletak pada :

114,619°–114,825° Bujur Timur
3,88573°–4,8015° Lintang Selatan

Dengan batas-batas :

| | |
|---|---|
| Sebelah Utara | : Kecamatan Pelaihari |
| Sebelah Timur | : Kecamatan Jorong |
| Sebelah Barat | : Laut Jawa dan Takisung |
| Sebelah Selatan | : Laut Jawa |

| | |
|---|---|
| Tinggi dari permukaan laut | : 25 - 100 meter |
| Luas Wilayah | : 388,91 $km^2$ |
| Jumlah Desa | : 10 desa |

https://tanahlautkab.bps.go.id

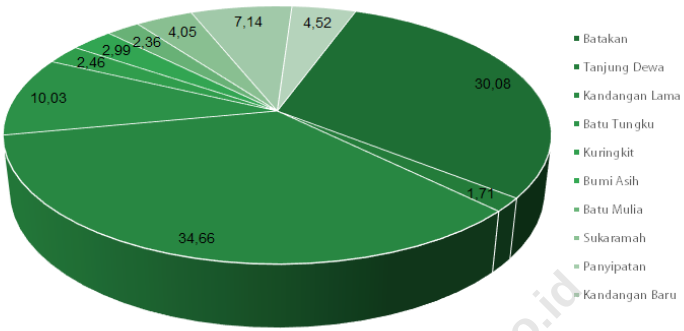


Sumber : Sekretariat Daerah Kabupaten Tanah Laut

**Gambar 1.1 Persentase Luas Desa/Kelurahan terhadap Luas Kecamatan di Kecamatan Panyipatan (persen), 2023**

https://tanahlautkab.bps.go.id

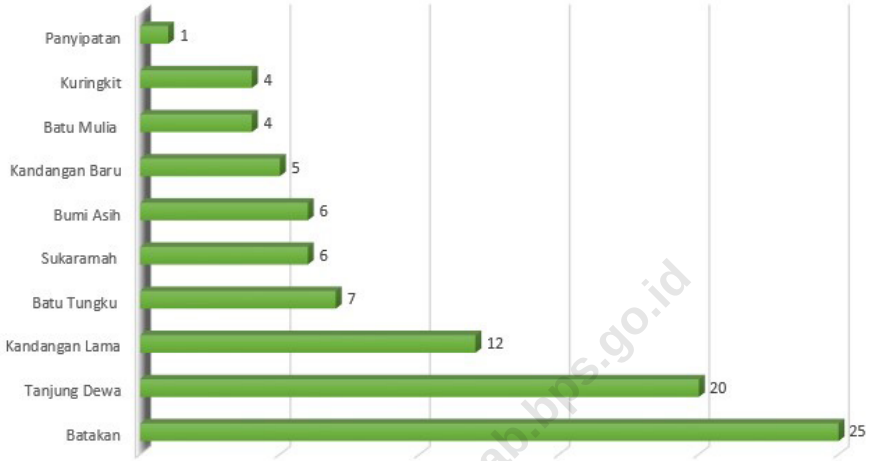


Sumber : Kantor Desa

**Gambar 1.2 Jarak ke Ibukota Kecamatan Menurut Desa/Kelurahan di Kecamatan Panyipatan (km), 2023**

https://kotalautkab.bps.go.id

## 1.1 KEADAAN GEOGRAFI

**Tabel 1.1.1 Luas Daerah Menurut Desa/Kelurahan di Kecamatan Panyipatan, 2023**

| Desa/Kelurahan | Luas ($km^2$) | Persentase terhadap Luas Kecamatan |
|---|---|---|
| (1) | (2) | (3) |
| Batakan | 116,97 | 30,08 |
| Tanjung Dewa | 6,64 | 1,71 |
| Kandangan Lama | 134,81 | 34,66 |
| Batu Tungku | 39,02 | 10,03 |
| Kuringkit | 9,55 | 2,46 |
| Bumi Asih | 11,65 | 2,99 |
| Batu Mulya | 9,17 | 2,36 |
| Suka Ramah | 15,74 | 4,05 |
| Panyipatan | 27,77 | 7,14 |
| Kandangan Baru | 17,59 | 4,52 |
| **Panyipatan** | **388,91** | **100,00** |

Sumber: Sekretariat Daerah Kabupaten Tanah Laut

https://tanahlautkab.bps.go.id

**Tabel 1.1.2 Jarak ke Ibukota Kecamatan dan Ibukota Kabupaten/Kota Menurut Desa/Kelurahan di Kecamatan Panyipatan (km), 2023**

| Desa/Kelurahan | Jarak ke Ibukota Kecamatan (km) | Jarak ke Ibukota Kabupaten/ Kota (km) |
|---|---|---|
| (1) | (2) | (3) |
| Batakan | 25 | 42 |
| Tanjung Dewa | 20 | 43 |
| Kandangan Lama | 12 | 32 |
| Batu Tungku | 7 | 25 |
| Kuringkit | 4 | 23 |
| Bumi Asih | 6 | 27 |
| Batu Mulya | 4 | 19 |
| Suka Ramah | 6 | 35 |
| Panyipatan | 1 | 22 |
| Kandangan Baru | **5** | **15** |

Sumber: Kantor Desa

https://tanahlautkab.bps.go.id

https://tanahlautkab.bps.go.id

# BAB 2
# PEMERINTAHAN

https://talaudkab.bps.go.id

https://tanahlautkab.bps.go.id

## PENJELASAN TEKNIS

1. Desa adalah satuan wilayah yang ditempati oleh sejumlah penduduk sebagai kesatuan masyarakat termasuk di dalamnya kesatuan masyarakat hukum yang mempunyai organisasi pemerintahan terendah dan langsung di bawah camat serta berhak menyelenggarakan rumah tangga sendiri dalam ikatan negara kesatuan Republik Indonesia (RI). Ciri utama desa adalah kepala desanya dipilih oleh masyarakat setempat.

2. Kelurahan adalah satuan wilayah yang ditempati oleh sejumlah penduduk yang mempunyai organisasi pemerintahan terendah langsung di bawah camat dan tidak berhak menyelenggarakan rumah tangga sendiri. Ciri utama kelurahan adalah kepala kelurahannya (lurah) sebagai pegawai negeri dan tidak dipilih oleh rakyat.

3. Badan Permusyawaratan Desa atau yang disebut dengan nama lain BPD adalah lembaga yang melaksanakan fungsi pemerintahan yang anggotanya merupakan wakil dari penduduk desa berdasarkan keterwakilan wilayah dan ditetapkan secara demokratis.

4. Di desa dibentuk lembaga kemasyarakatan desa, seperti rukun tetangga, rukun warga, pembinaan kesejahteraan keluarga, karang taruna, dan lembaga pemberdayaan masyarakat atau yang disebut dengan nama lain. Lembaga kemasyarakatan desa bertugas membantu Pemerintah Desa dan merupakan mitra dalam memberdayakan masyarakat desa.

https://banjarkab.bps.go.id

https://tanahlautkab.bps.go.id

## ULASAN

Jumlah desa di Kecamatan Panyipatan sebanyak 10 desa yang terbagi menjadi 40 dusun/Rukun Warga (RW) dan 145 Rukun Tetangga (RT). Setiap desa di Kecamatan Panyipatan memiliki Badan Pemusyawaratan Desa (BPD) yang memiliki fungsi yaitu membahas dan menyepakati Rancangan Peraturan Desa (Perdes) bersama kepala desa; menampung dan menyalurkan aspirasi masyarakat desa; dan. melakukan pengawasan kinerja kepala desa. Anggota BPD di Kecamatan Panyipatan masing-masing umumnya sejumlah 5 orang kecuali di Desa Batakan 9 orang dan di Desa Tanjung Dewa 7 orang.

https://tanahlautkab.bps.go.id

## 2.1 WILAYAH ADMINISTRATIF

**Tabel 2.1.1 Jumlah Rukun Warga (RW) dan Rukun Tetangga (RT) Menurut Desa/Kelurahan di Kecamatan Panyipatan, 2023**

| Desa/Kelurahan | Rukun Warga (RW) | Rukun Tetangga (RT) |
|---|---|---|
| (1) | (2) | (3) |
| Batakan | 7 | 21 |
| Tanjung Dewa | 5 | 17 |
| Kandangan Lama | 4 | 9 |
| Batu Tungku | 5 | 14 |
| Kuringkit | 2 | 11 |
| Bumi Asih | 3 | 13 |
| Batu Mulya | 3 | 16 |
| Suka Ramah | 4 | 18 |
| Panyipatan | 4 | 16 |
| Kandangan Baru | 3 | 10 |
| **Panyipatan** | **40** | **145** |

Sumber: Kantor Kecamatan

https://tanahlautkab.bps.go.id

**Tabel 2.1.2 Nama Camat/Kepala Wilayah Kecamatan Panyipatan, 1983-2023**

| Nama | Jabatan | Periode Jabatan |
|---|---|---|
| (1) | (2) | (3) |
| Surya Melhani, BA | Camat | 1983–1989 |
| Drs. Sutarno | Camat | 1989–1991 |
| Drs. Fahruraji | Camat | 1991–1992 |
| Drs. Rahadi Noor | Camat | 1992–1998 |
| Drs. M. Rafiki Effendi | Camat | 1998–2001 |
| Drs. Muhidin | Camat | 2001–2002 |
| Drs. Firmansyah | Camat | 2002–2005 |
| Drs. Chairil, M.Si. | Camat | 2005–2007 |
| Drs. Sugian Noor | Camat | 2007–2009 |
| Drs. Mahdiani, MT | Camat | 2009–2010 |
| Bambang Kusudarisman, S.IP, M.Si. | Camat | 2011–2012 |
| Abdurakhman Sidiq, S.Sos | Camat | 2013–2016 |
| Drs. Gusti Sofuan Hadi | Camat | 2016–2016 |
| Muhammad Syahid, S.STP, M.AP | Camat | 2016 –2019 |
| Agus Setiyo, S.STP, MM | Camat | 2019–2023 |
| Muhammad Hadiat Wicaksono, S.STP, M.IP | Camat | 2023–sekarang |

Sumber: Kantor Kecamatan

https://tanahlautkab.bps.go.id

## Tabel 2.1.3 Nama Kepala Desa di Kecamatan Panyipatan, 2023

| Desa | Nama Kepala Desa | Keterangan |
|---|---|---|
| (1) | (2) | (3) |
| Batakan | Patnur | – |
| Tanjung Dewa | Muslih | – |
| Kandangan Lama | Bahtiar | – |
| Batu Tungku | Said Muhammad | – |
| Kuringkit | Amid | PJ |
| Bumi Asih | Ari Wibowo | – |
| Batu Mulya | Masduki | – |
| Suka Ramah | Siti Khoiriah | – |
| Panyipatan | M. Yusri, SE | – |
| Kandangan Baru | Rusdiansyah | – |

Sumber: Kantor Kecamatan

https://tanahlautkab.bps.go.id

**Tabel 2.1.4 Jumlah Anggota Badan Permusyawaratan Desa (BPD) di Kecamatan Panyipatan, 2023**

| Desa | Anggota BPD | Keterangan |
|---|---|---|
| (1) | (2) | (3) |
| Batakan | 9 | – |
| Tanjung Dewa | 7 | – |
| Kandangan Lama | 5 | – |
| Batu Tungku | 5 | – |
| Kuringkit | 5 | – |
| Bumi Asih | 5 | – |
| Batu Mulya | 5 | – |
| Suka Ramah | 5 | – |
| Panyipatan | 5 | – |
| Kandangan Baru | 5 | – |

Sumber: Kantor Kecamatan

https://tanahlautkab.bps.go.id

## Tabel 2.1.5 Nama Ketua RT di Desa Batakan, 2023

| RW/Dusun | RT | Nama Ketua RT |
|---|---|---|
| (1) | (2) | (3) |
| RW 01 | RT 15 | Syamsudin |
| | RT 16 | Kandarani |
| RW 02 | RT 18 | Darasul |
| | RT 21 | Ajis |
| RW 03 | RT 19 | Murhansyah |
| | RT 20 | Suparman |
| RW 04 | RT 01 | Iderus |
| | RT 04 | Armani |
| | RT 05 | Muhammad |
| RW 05 | RT 02 | Mastan |
| | RT 03 | Kaspul Anwar |
| | RT 06 | Maidah |
| | RT 07 | H.Tarmiji |
| RW 06 | RT 08 | Husni |
| | RT 09 | Aseri |
| | RT 10 | Ahmad Syahruji |
| RW 07 | RT 11 | Rahmani |
| | RT 12 | Muhdi |
| | RT 13 | Karnadi |
| | RT 14 | Jali |
| | RT 13A | Karnadi |

Sumber: Kantor Desa Batakan

https://tanahlautkab.bps.go.id

## Tabel 2.1.6 Nama Ketua RT di Desa Tanjung Dewa, 2023

| RW/Dusun | RT | Nama Ketua RT |
|---|---|---|
| (1) | (2) | (3) |
| RW 01 | RT 01 | Sumarni |
| | RT 02 | Darmansyah |
| | RT 03 | Fatimah |
| RW 02 | RT 04 | Sarhani |
| | RT 05 | Taufik Ismail |
| | RT 06 | Lasman |
| RW 03 | RT 07 | Asrani |
| | RT 08 | Aidi |
| | RT 09 | Idrus |
| RW 04 | RT 10 | Ahyani |
| | RT 11 | Darham |
| | RT 12 | Salmani |
| | RT 13A | Mahyuni |
| RW 05 | RT 13 | Mahyuni |
| | RT 14 | Kaspul |
| | RT 15 | Asbullah |
| | RT 13B | Mahyuni |

Sumber: Kantor Desa Tanjung Dewa

https://tanahlautkab.bps.go.id

## Tabel 2.1.7 Nama Ketua RT di Desa Kandangan Lama, 2023

| RW/Dusun | RT | Nama Ketua RT |
|---|---|---|
| (1) | (2) | (3) |
| RW 01 | RT 01 | Usman |
| | RT 02 | H. Jarni |
| | RT 03 | Jamhari |
| RW 02 | RT 04 | Jumaintang |
| | RT 05 | H. A. Kaspul A |
| RW 03 | RT 06 | Badrani |
| | RT 08 | Ali |
| RW 04 | RT 07 | Mustafa |
| | RT 09 | Taufik |

Sumber: Kantor Desa Kandangan Lama

https://tanahlautkab.bps.go.id

## Tabel 2.1.8 Nama Ketua RT di Desa Batu Tungku, 2023

| RW/Dusun | RT | Nama Ketua RT |
|---|---|---|
| (1) | (2) | (3) |
| RW 01 | RT 01 | Darhani |
| RW 02 | RT 04 | Rahmiansyah |
| | RT 05 | M. Salim |
| | RT 4A | Rahmiansyah |
| RW 03 | RT 06 | Iswanto |
| | RT 07 | Paryono |
| | RT 08 | Sugeng Margianto |
| RW 04 | RT 09 | Sumardi |
| | RT 10 | Sulis |
| | RT 11 | Sukamto |
| RW 05 | RT 02 | Basrani |
| | RT 03 | Muhammad J |
| | RT 12 | Supiani |
| | RT 12A | Supiani |

Sumber: Kantor Desa Batu Tungku

https://tanahlautkab.bps.go.id

## Tabel 2.1.9 Nama Ketua RT di Desa Kuringkit, 2023

| RW/Dusun | RT | Nama Ketua RT |
|---|---|---|
| (1) | (2) | (3) |
| RW 01 | RT 01 | Saini |
| | RT 02 | Darmili |
| | RT 07 | Jainudin |
| | RT 08 | M.Iskandar |
| | RT 09 | H. Basurai |
| RW 02 | RT 03 | Rahyu |
| | RT 04 | Abdul Azim |
| | RT 05 | Sayid Abdullah |
| | RT 06 | Abdurahman Sidik |
| | RT 10 | Arkani |
| | RT 06A | Durahman |

Sumber: Kantor Desa Kuringkit

https://tanahlautkab.bps.go.id

## Tabel 2.1.10 Nama Ketua RT di Desa Bumi Asih, 2023

| RW/Dusun | RT | Nama Ketua RT |
|---|---|---|
| (1) | (2) | (3) |
| RW 01 | RT 01 | Sugeng Hariyadi |
| | RT 02 | Nur Suhud |
| | RT 03 | Suparlin |
| RW 02 | RT 04 | M Sarjono |
| | RT 05 | Siswanto |
| | RT 06 | Agung Sutrisno |
| | RT 07 | Amrul Habibi |
| | RT 08 | Dulatip |
| | RT 09 | Sumadi |
| RW 3 | RT 10 | Riaman |
| | RT 11 | Pardi |
| | RT 12 | Suparman |
| | RT 13 | Hariyono |

Sumber: Kantor Desa Bumi Asih

https://tanahlautkab.bps.go.id

## Tabel 2.1.11 Nama Ketua RT di Desa Batu Mulya, 2023

| RW/Dusun | RT | Nama Ketua RT |
|---|---|---|
| (1) | (2) | (3) |
| RW 01 | RT 01 | Jayat |
| | RT 02 | Misdiono |
| | RT 03 | Sutrisno |
| | RT 04 | Supingi |
| | RT 05 | Widodo |
| | RT 01C | Jayat |
| RW 02 | RT 06 | Samino |
| | RT 07 | Tatang Tanaya |
| | RT 08 | Juwono |
| | RT 09 | Sukmara |
| | RT 10 | Suhadi |
| RW 03 | RT 11 | Prajoko |
| | RT 12 | Iman Basori |
| | RT 13 | Suparno |
| | RT 14 | M. Parsuni |
| | RT 15 | Heri Sumarso |

Sumber: Kantor Desa Batu Mulya

https://tanahlautkab.bps.go.id

## Tabel 2.1.12 Nama Ketua RT di Desa Suka Ramah, 2023

| RW/Dusun | RT | Nama Ketua RT |
|---|---|---|
| (1) | (2) | (3) |
| RW 01 | RT 01 | Sumaryono |
| | RT 02 | Haryono |
| | RT 03 | Suparman |
| | RT 04 | Suharyadi |
| RW 02 | RT 05 | Bejo Suprihatin |
| | RT 06 | Sugiran |
| | RT 07 | Jalaludin |
| | RT 08 | Enoh Hermawan |
| RW 03 | RT 09 | Kade Rudita |
| | RT 10 | Supardi |
| | RT 11 | Rudi Puriawan |
| | RT 12 | Hadi Harmami |
| | RT 10A | Supardi |
| RW 04 | RT 13 | Supardi |
| | RT 14 | Hermawan |
| | RT 15 | Selamet |
| | RT 16 | Tolani |

Sumber: Kantor Desa Suka Ramah

https://tanahlautkab.bps.go.id

## Tabel 2.1.13 Nama Ketua RT di Desa Panyipatan, 2023

| RW/Dusun | RT | Nama Ketua RT |
|---|---|---|
| (1) | (2) | (3) |
| Dusun 01 | RT 01 | Supiansyah |
| | RT 04 | Saripudin |
| | RT 05 | Mansyur R. |
| Dusun 02 | RT 02 | Abdul Gaus |
| | RT 03 | Samlani |
| | RT 11 | Abdul Muin |
| | RT 12 | Maskadin |
| Dusun 03 | RT 06 | Isa Ansari |
| | RT 07 | Mursidi |
| | RT 10 | Ambran |
| | RT 10A | A. Badrudin |
| | RT 10B | Ambran |
| Dusun 04 | RT 08 | M. Khalil |
| | RT 08A | Sulhan |
| | RT 09 | Khalik |
| | RT 13 | Ishak |

Sumber: Kantor Desa Panyipatan

https://tanahlautkab.bps.go.id

## Tabel 2.1.14 Nama Ketua RT di Desa Kandangan Baru, 2023

| RW/Dusun | RT | Nama Ketua RT |
|---|---|---|
| (1) | (2) | (3) |
| RW 01 | RT 01 | Maswani |
| | RT 02 | Suriansyah |
| | RT 03 | Abdullah |
| | RT 04 | Ahmad |
| RW 02 | RT 05 | Ibrahim |
| | RT 06 | Saipudin |
| | RT 07 | Jahrani |
| RW 03 | RT 08 | Jaliansyah |
| | RT 09 | Abidin |
| | RT 10 | Rudi Hermanto |

Sumber: Kantor Desa Kandangan Baru

https://tanahlautkab.bps.go.id

https://tanahlautkab.bps.go.id

# BAB 3
# PENDUDUK

https://tanahlautkab.bps.go.id

## PENJELASAN TEKNIS

1. Sumber utama data kependudukan adalah sensus penduduk yang dilaksanakan setiap sepuluh tahun sekali. Di dalam sensus penduduk, pencacahan dilakukan terhadap seluruh penduduk yang berdomisili di wilayah teritorial Indonesia termasuk warga negara asing kecuali anggota korps diplomatik negara sahabat beserta keluarganya.
   Untuk tahun yang tidak dilaksanakan sensus penduduk, data kependudukan diperoleh dari data registrasi penduduk didasarkan pada asumsi dari komponen-komponen perubahan penduduk, yaitu kelahiran, kematian, dan migrasi.

2. Penduduk Indonesia adalah semua orang yang berdomisili di wilayah teritorial Indonesia, mencakup Warga Negara Indonesia (WNI) dan Warga Negara Asing (WNA) yang telah menetap selama satu tahun atau lebih atau berencana menetap di wilayah Indonesia selama minimal satu tahun.

3. Kepadatan penduduk adalah ukuran persebaran penduduk yang menunjukkan jumlah penduduk untuk setiap kilometer persegi luas wilayah.

4. Rasio jenis kelamin adalah perbandingan antara jumlah penduduk laki-laki dan jumlah penduduk perempuan pada suatu daerah dan waktu tertentu, yang biasanya dinyatakan dalam banyaknya penduduk laki-laki per 100 penduduk perempuan.

https://manado.bps.go.id

https://tanahlautkab.bps.go.id

## ULASAN

Jumlah penduduk di Kecamatan Panyipatan pada tahun 2023 berdasarkan hasil registrasi penduduk dari Dinas Kependudukan dan Pencatatan Sipil Kabupaten Tanah Laut yaitu 26.063 jiwa. Penduduk paling banyak di Kecamatan Panyipatan terdapat di Desa Batakan dengan jumlah penduduk sebanyak 5.070 jiwa dan paling sedikit di Desa Kuringkit sejumlah 1.723 jiwa. Jika dilihat kepadatan penduduknya, Desa Tanjung Dewa merupakan desa dengan kepadatan penduduk tertinggi yaitu 468 jiwa per km$^2$. Sementara itu di Desa Kandangan Lama kepadatan penduduknya paling sedikit yaitu 19 jiwa per km$^2$. Rasio jenis kelamin penduduk di Kecamatan Panyipatan secara umum yaitu 102 yang artinya terdapat sebanyak 102 penduduk laki-laki per 100 penduduk perempuan. Desa Kandangan Lama, Bumi Asih, Batu Mulya, dan Panyipatan merupakan desa yang rasio jenis kelaminnya kurang dari 100 yaitu 99.

https://tanahlautkab.bps.go.id

**Tabel 3.1** **Penduduk, Distribusi Persentase Penduduk, Kepadatan Penduduk, Rasio Jenis Kelamin Penduduk Menurut Desa/ Kelurahan di Kecamatan Panyipatan, 2023**

| Desa/Kelurahan | Penduduk | | |
|---|---|---|---|
| | Laki-Laki | Perempuan | Jumlah |
| (1) | (2) | (3) | (4) |
| Batakan | 2.579 | 2.491 | 5.070 |
| Tanjung Dewa | 1.587 | 1.519 | 3.106 |
| Kandangan Lama | 1.238 | 1.269 | 2.507 |
| Batu Tungku | 1.404 | 1.350 | 2.754 |
| Kuringkit | 861 | 862 | 1.723 |
| Bumi Asih | 917 | 938 | 1.855 |
| Batu Mulya | 981 | 1.015 | 1.996 |
| Suka Ramah | 1.238 | 1.184 | 2.422 |
| Panyipatan | 1.387 | 1.423 | 2.810 |
| Kandangan Baru | 951 | 869 | 1.820 |
| **Panyipatan** | **13.143** | **12.920** | **26.063** |

https://tanahlautkab.bps.go.id

Lanjutan Tabel 3.1

| Desa/Kelurahan | Persentase Penduduk | Kepadatan Penduduk (per km$^2$) | Rasio Jenis Kelamin Penduduk |
|---|---|---|---|
| (1) | (5) | (6) | (7) |
| Batakan | 19,45 | 43 | 104 |
| Tanjung Dewa | 11,92 | 468 | 104 |
| Kandangan Lama | 9,62 | 19 | 98 |
| Batu Tungku | 10,57 | 71 | 104 |
| Kuringkit | 6,61 | 180 | 100 |
| Bumi Asih | 7,12 | 159 | 98 |
| Batu Mulya | 7,66 | 218 | 97 |
| Suka Ramah | 9,29 | 154 | 105 |
| Panyipatan | 10,78 | 101 | 97 |
| Kandangan Baru | 6,98 | 103 | 109 |
| **Panyipatan** | **100,00** | **67** | **102** |

Sumber: Dinas Kependudukan dan Pencatatan Sipil Kabupaten Tanah Laut

https://tanahlautkab.bps.go.id

https://tanahlautkab.bps.go.id

# BAB 4
# SOSIAL DAN KESEJAHTERAAN RAKYAT

https://kab-halmahera-tengah.bps.go.id

https://tanahlautkab.bps.go.id

## PENJELASAN TEKNIS

1. Jalur Pendidikan di Indonesia terdiri atas 1) pendidikan formal, 2) pendidikan nonformal, dan 3) pendidikan informal yang ketiganya dapat saling melengkapi dan memperkaya (Undang-Undang No. 20 Tahun 2003 tentang Sistem Pendidikan Nasional).

2. Jenjang Pendidikan Formal terdiri atas pendidikan dasar, pendidikan menengah, dan pendidikan tinggi. Jenis pendidikan yang diajarkan mencakup pendidikan umum, kejuruan, akademik, profesi, vokasi, keagamaan, dan khusus.

- Pendidikan Dasar berbentuk Sekolah Dasar (SD) danMadrasah Ibtidaiyah (MI) atau bentuk lain yang sederajat serta Sekolah Menengah Pertama (SMP) dan MadrasahTsanawiyah (MTs), atau bentuk lain yang sederajat.
- Pendidikan Menengah berbentuk Sekolah Menengah Atas (SMA), Madrasah Aliyah (MA), Sekolah Menengah Kejuruan (SMK), dan Madrasah Aliyah Kejuruan (MAK), atau bentuk lain yang sederajat.
- Pendidikan Tinggi merupakan jenjang pendidikan setelah pendidikan menengah yang mencakup program pendidikan diploma, sarjana, magister, spesialis, dan doktor yang diselenggarakan oleh perguruan tinggi. Perguruan tinggi dapat berbentuk akademi, politeknik, sekolah tinggi, institut, atau universitas.

3. Dokter umum adalah dokter yang diperkenankan untuk melakukan praktik medis tanpa harus memiliki spesialisasi tertentu, sehingga memungkinkannya untuk memeriksa masalah kesehatan pasien secara umum untuk segala usia.

4. Rumah sakit adalah tempat pemeriksaan dan perawatan kesehatan, biasanya berada di bawah pengawasan dokter/tenaga medis, yang melayani pasien untuk berobat rawat jalan atau rawat inap. Undang-Undang RI No. 44 Tahun 2009 tentang Rumah Sakit mengelompokkan rumah sakit berdasarkan jenis pelayanan yang diberikan menjadi:

- Rumah sakit umum adalah rumah sakit yang memberikn pelayanan kesehatan pada semua bidang dan jenis penyakit.
- Rumah sakit khusus adalah rumah sakit yang memberikan pelayanan utama pada satu bidang atau satu jenis penyakit tertentu berdasarkan disiplin ilmu, golongan umur, organ, jenis penyakit, atau kekhususan lainnya.

https://kalimantan.bps.go.id

5. Rumah Sakit Bersalin adalah rumah sakit khusus untuk persalinan, dilengkapi pelayanan spesialis pemeriksaan kehamilan, persalinan, rawat inap dan rawat jalan ibu dan anak yang berada di bawah pengawasan dokter spesialis kandungan.

6. Rumah Bersalin adalah sarana pelayanan kesehatan dengan izin sebagai rumah bersalin, dilengkapi pelayanan pemeriksaan kehamilan, persalinan serta pemeriksaan ibu dan anak yang berada di bawah pengawasan bidan senior.

7. Poliklinik adalah sarana kesehatan yang dipakai untuk pelayanan, berobat jalan, biasanya berada di bawah pengawasan dokter/tenaga medis.

8. Pusat Kesehatan Masyarakat (Puskesmas) adalah unit pelaksana teknis dinas kesehatan kabupaten/kota yang mempunyai fungsi utama sebagai penyelenggara pelayanan kesehatan tingkat pertama. Wilayah kerja puskesmas maksimal adalah 1 (satu) kecamatan. Untuk dapat menjangkau wilayah kerjanya, Puskesmas mempunyai jaringan pelayanan yang meliputi unit Puskesmas Pembantu (Pustu), unit Puskesmas Keliling (Puskel), dan unit bidan desa/komunitas (Peraturan Menteri Kesehatan RI No. 75 Tahun 2014 tentang Pusat Kesehatan Masyarakat).

9. Apotek adalah suatu tempat tertentu yang digunakan untuk melakukan pekerjaan kefarmasian, dan penyaluran/penjualan obat atau bahan farmasi dan perbekalan kesehatan lainnya kepada masyarakat yang dikelola oleh tenaga apoteker (Peraturan Menteri Kesehatan RI No. 1332 Tahun 2002 Tentang Perubahan Atas Peraturan Menteri Kesehatan RI No. 922/MENKES/PER/X/1993 Tentang Ketentuan dan Tata Cara Pemberian Izin Apotek).

10. Air leding adalah sumber air yang berasal dari air yang telah melalui proses penjernihan dan penyehatan sebelum dialirkan kepada konsumen melalui instalasi berupa saluran air. Sumber air ini biasanya diusahakan oleh PAM/PDAM/BPAM. Termasuk dalam hal ini air leding yang didapat secara eceran.

11. Sumur terlindung adalah air yang berasal dari dalam tanah yang digali dan lingkar sumur tersebut dilindungi oleh tembok paling sedikit 0,8 meter di atas tanah dan 3 meter ke bawah tanah, serta ada lantai semen sejauh 1 meter dari lingkar sumur.

https://kotakotukan.bps.go.id

12. Sumber penerangan utama merupakan sumber penerangan yang paling banyak digunakan oleh rumah tangga apabila memiliki lebih dari satu sumber.

13. Fasilitas tempat buang air besar adalah ketersediaan jamban/kloset yang digunakan oleh rumah tangga.

14. Status kepemilikan bangunan tempat tinggal milik sendiri adalah tempat tinggal yang merupakan milik kepala rumah tangga atau salah seorang anggota rumah tangga. Rumah yang dibeli secara angsuran melalui kredit bank atau rumah dengan status sewa beli dianggap rumah milik sendiri.

15. Sanitasi layak adalah fasilitas sanitasi yang memenuhi syarat kesehatan, antara lain kloset menggunakan leher angsa, tempat pembuangan akhir tinja menggunakan tangki septik (septic tank) atau Instalasi/Sistem Pengolahan Air Limbah (IPAL/SPAL), dan fasilitas sanitasi tersebut digunakan oleh rumah tangga sendiri, bersama dengan rumah tangga lain tertentu, ataupun di MCK Komunal. Untuk daerah perdesaan, dikatakan memiliki akses sanitasi layak, jika kloset menggunakan leher angsa, tempat pembuangan akhir tinja ke tangki septik atau Instalasi/Sistem Pengolahan Air Limbah (IPAL/SPAL) atau lubang tanah dan fasilitas sanitasi tersebut digunakan oleh rumah tangga sendiri, bersama dengan rumah tangga lain tertentu, ataupun di MCK Komunal.
    Konsep sanitasi layak mengacu konsep terbaru berdasarkan Surat Kementerian Perencanaan Pembangunan Nasional/Bappenas Nomor 661/ Dt.2.4/01/2019.

16. Sumber air minum layak adalah jika rumah tangga menggunakan sumber air minum utama berupa leding, air terlindungi, atau air hujan. Air terlindungi mencakup sumur bor/pompa, sumur terlindung, dan mata air terlindung. Bagi rumah tangga yang menggunakan sumber air minum berupa air kemasan bermerk atau air isi ulang, maka rumah tangga dikategorikan memiliki akses air minum layak jika sumber air untuk mandi/cuci berasal dari leding, sumur bor/pompa, sumur terlindung, mata air terlindung, atau air hujan.
    Konsep air minum layak mengacu konsep terbaru berdasarkan Surat Kementerian Perencanaan Pembangunan Nasional/Bappenas Nomor 661/ Dt.2.4/01/2019.

https://jambi.bps.go.id

17. Peristiwa kejahatan yang dilaporkan adalah setiap peristiwa yang dilaporkan masyarakat pada Polri, atau peristiwa dimana pelakunya tertangkap tangan oleh kepolisian.

18. Jumlah kejahatan menggambarkan jumlah kasus kejahatan yang terjadi pada kurun waktu tertentu.

19. Tempat ibadah adalah bangunan/ruangan yang lokasinya tetap dan peruntukannya khusus untuk ibadah oleh masyarakat umum sesuai agama yang dianut tanpa memandang status kepemilikan, termasuk bangunan/ruangan yang lokasinya tetap dan fungsinya dikhususkan untuk ibadah di fasilitas umum. Tidak termasuk tempat ibadah yang khusus dipakai oleh pribadi/keluarga.

20. Pernikahan/Perkawinan merupakan ikatan lahir dan batin antara seorang wanita dengan seorang pria sebagai suami istri dengan tujuan membentuk keluarga (rumah tangga) yang bahagia dan kekal berdasarkan Ketuhanan Yang Maha Esa (Undang-Undang Nomor 1 Tahun 1974 tentang Perkawinan Pasal 1).

    Pernikahan/Perkawinan adalah sah, apabila dilakukan menurut hukum masing-masing agamanya dan kepercayaannya itu. Tiap-tiap pernikahan/perkawinan dicatat menurut peraturan perundang-undangan yang berlaku (Undang-undang Nomor 1 Tahun 1974 tentang Perkawinan Pasal 2). Dalam hal ini, pernikahan untuk yang beragama Islam dianggap sah menurut undang-undang jika tercatat di Kantor Urusan Agama (KUA). Pencatatan perkawinan tersebut dilakukan oleh pegawai pencatat nikah. Dengan demikian, setiap perkawinan harus dilangsungkan di hadapan dan di bawah pengawasan pegawai pencatat nikah. Pernikahan boleh dilakukan di KUA atau di luar KUA (nikah bedolan).

21. Perceraian adalah salah satu sebab putusnya perkawinan/pernikahan yang dapat terjadi karena talak (cerai talak) atau berdasarkan gugatan perceraian (cerai gugat). Undang-Undang Nomor 1 Tahun 1974 tentang Perkawinan Pasal 39 menyatakan: (1) Perceraian hanya dapat dilakukan di depan sidang Pengadilan setelah Pengadilan yang bersangkutan berusaha dan tidak berhasil mendamaikan kedua belah pihak; (2) Untuk melakukan perceraian harus ada cukup alasan bahwa antara suami istri itu tidak akan dapat rukun sebagai suami istri; (3) Tata cara perceraian di depan sidang Pengadilan diatur dalam peraturan perundangan tersebut.

https://katuahkab.bps.go.id

Data pernikahan dan perceraian yang tersedia dalam publikasi ini hanya mencakup pernikahan dan perceraian untuk yang beragama Islam. Data pernikahan diperoleh dari Dirjen Bimas Islam, Kementerian Agama RI. Sementara data perceraian diperoleh dari Dirjen Badan Peradilan Agama, Mahkamah Agung.

22. Bencana adalah peristiwa atau rangkaian peristiwa yang mengancam dan mengganggu kehidupan dan penghidupan masyarakat yang disebabkan baik oleh faktor alam dan atau faktor nonalam maupun faktor manusia sehingga mengakibatkan timbulnya korban jiwa, kerusakan lingkungan, kerugian harta benda, dan dampak psikologis.

23. Bencana Alam adalah peristiwa atau serangkaian peristiwa yang mengancam dan mengganggu kehidupan/penghidupan masyarakat yang disebabkan oleh faktor alam antara lain berupa gempa bumi, tsunami, gunung meletus, banjir, kekeringan, angin topan, dan tanah longsor sehingga mengakibatkan kerugian materi maupun nonmateri.

https://tanahlautkab.bps.go.id

https://tanahlautkab.bps.go.id

## ULASAN

Fasilitas pendidikan yang terdapat di Kecamatan Panyipatan terdiri dari 22 SD/MI, 8 SMP/MTs, dan 4 SMA/MA. Seluruh desa di Kecamatan Panyipatan sudah memiliki sarana pendidikan Sekolah Dasar (SD), sedangkan untuk sarana pendidikan pada tingkat yang lebih tinggi hanya terdapat di beberapa desa.

Sarana kesehatan di Kecamatan Panyipatan meliputi 2 puskesmas dan 25 posyandu.

Secara umum keluarga di Kecamatan Panyipatan menggunakan listrik PLN sebagai sumber penerangan utama, menggunakan elpiji 3 kg untuk bahan bakar untuk memasak, menggunakan fasilitas buang air besar berupa jamban milik sendiri, sumber air minumnya dari sumur dan sumur bor atau pompa, dan penerangan jalan utamanya merupakan listrik pemerintah.

Tempat peribadatan di Kecamatan Panyipatan terdiri dari 20 masjid, 57 mushola, 3 gereja Protestan dan 1 gereja Katholik. Mushola dan masjid dapat ditemui di seluruh di desa, sementara gereja Protestan terletak di Desa Batu Tungku dan Bumi Asih; gereja Katholik berada di Desa Batu Mulya. Di Kecamatan Panyipatan tahun 2023, pernikahan paling banyak berlangsung pada bulan Maret.

https://tanah.ayrabb.com

## 4.1 PENDIDIKAN

**Tabel 4.1.1 Banyaknya Desa[1]/Kelurahan yang Memiliki Fasilitas Sekolah Menurut Tingkat Pendidikan di Kecamatan Panyipatan, 2021–2023**

| Tingkat Pendidikan | 2021[2] | 2022[3] | 2023[3] |
|---|---|---|---|
| (1) | (2) | (3) | (4) |
| Sekolah Dasar (SD) | 10 | 10 | 10 |
| Madrasah Ibtidaiyah (MI) | 3 | 3 | 4 |
| Sekolah Menengah Pertama (SMP) | 3 | 3 | 3 |
| Madrasah Tsanawiyah (MTs) | 5 | 5 | 5 |
| Sekolah Menengah Atas (SMA) | 2 | 2 | 2 |
| Sekolah Menengah Kejuruan (SMK) | – | – | – |
| Madrasah Aliyah (MA) | 2 | 2 | 2 |
| Akademi/Perguruan Tinggi | – | – | – |

Catatan: [1] Desa pada tabel ini termasuk Unit Permukiman Transmigrasi (UPT) yang masih dibina oleh kementerian terkait

Sumber: [2] Badan Pusat Statistik, Pendataan Potensi Desa (Podes)

[3] Kantor Desa

https://tanahlautkab.bps.go.id

## Tabel 4.1.2 Jumlah Sekolah Menurut Tingkat Pendidikan di Kecamatan Panyipatan, 2023/2024

| Tingkat Pendidikan | Negeri | Swasta | Jumlah |
|---|---|---|---|
| (1) | (2) | (3) | (4) |
| Taman Kanak-Kanak (TK)[1] | 1 | 16 | 17 |
| Raudatul Athfal (RA)[2] | –[3] | 1 | 1 |
| Sekolah Dasar (SD)[4] | 18 | – | 18 |
| Madrasah Ibtidaiyah (MI)[2] | 1 | 3 | 4 |
| Sekolah Menengah Pertama (SMP)[4] | 3 | – | 3 |
| Madrasah Tsanawiyah (MTs)[2] | 2 | 3 | 5 |
| Sekolah Menengah Atas (SMA)[4] | 1 | 1 | 2 |
| Sekolah Menengah Kejuruan (SMK)[4] | – | – | – |
| Madrasah Aliyah (MA)[2] | – | 2 | 2 |

Catatan: [3] Seluruh Raudatul Athfal (RA) berstatus swasta

Sumber: [1] Kementerian Pendidikan, Kebudayaan, Riset, dan Teknologi; https://dapo.kemdikbud.go.id/sp; data semester genap per tanggal 3 September 2024

[2] Kementerian Agama, EMIS, data semester genap laporan sampai dengan 30 Juni 2024

[4] Kementerian Pendidikan, Kebudayaan, Riset, dan Teknologi; Sistem Data Pokok Pendidikan; data semester ganjil laporan sampai dengan 30 November 2023

https://tanahlautkab.bps.go.id

## Tabel 4.1.3 Jumlah Guru Menurut Tingkat Pendidikan di Kecamatan Panyipatan, 2023/2024

| Tingkat Pendidikan | Negeri | Swasta | Jumlah |
|---|---|---|---|
| (1) | (2) | (3) | (4) |
| Taman Kanak-Kanak (TK)[1] | 10 | 84 | 94 |
| Raudatul Athfal (RA)[2] | –[3] | 5 | 5 |
| Sekolah Dasar (SD)[4] | 181 | – | 181 |
| Madrasah Ibtidaiyah (MI)[2] | 22 | 33 | 55 |
| Sekolah Menengah Pertama (SMP)[4] | 39 | – | 39 |
| Madrasah Tsanawiyah (MTs)[2] | 50 | 45 | 95 |
| Sekolah Menengah Atas (SMA)[4] | 26 | 11 | 37 |
| Sekolah Menengah Kejuruan (SMK)[4] | – | – | – |
| Madrasah Aliyah (MA)[2] | – | 25 | 25 |

Catatan: [3] Seluruh Raudatul Athfal (RA) berstatus swasta
[5] Jumlah guru termasuk kepala sekolah dan guru

Sumber: [1] Kementerian Pendidikan, Kebudayaan, Riset, dan Teknologi; https://dapo.kemdikbud.go.id/sp; data semester genap per tanggal 3 September 2024
[2] Kementerian Agama, EMIS, data semester genap laporan sampai dengan 30 Juni 2024
[4] Kementerian Pendidikan, Kebudayaan, Riset, dan Teknologi; Sistem Data Pokok Pendidikan; data semester ganjil laporan sampai dengan 30 November 2023

https://tanahlautkab.bps.go.id

## Tabel 4.1.4 Jumlah Murid Menurut Tingkat Pendidikan di Kecamatan Panyipatan, 2023/2024

| Tingkat Pendidikan | Negeri | Swasta | Jumlah |
|---|---|---|---|
| (1) | (2) | (3) | (4) |
| Taman Kanak-Kanak (TK)[1] | 63 | 732 | 795 |
| Raudatul Athfal (RA)[2] | –[3] | 53 | 53 |
| Sekolah Dasar (SD)[4] | 2.300 | – | 2.300 |
| Madrasah Ibtidaiyah (MI)[2] | 207 | 303 | 510 |
| Sekolah Menengah Pertama (SMP)[4] | 426 | – | 426 |
| Madrasah Tsanawiyah (MTs)[2] | 359 | 313 | 672 |
| Sekolah Menengah Atas (SMA)[4] | 364 | 87 | 451 |
| Sekolah Menengah Kejuruan (SMK)[4] | – | – | – |
| Madrasah Aliyah (MA)[2] | – | 141 | 141 |

Catatan: [3] Seluruh Raudatul Athfal (RA) berstatus swasta

Sumber: [1] Kementerian Pendidikan, Kebudayaan, Riset, dan Teknologi; https://dapo.kemdikbud.go.id/sp; data semester genap per tanggal 3 September 2024

[2] Kementerian Agama, EMIS, data semester genap laporan sampai dengan 30 Juni 2024

[4] Kementerian Pendidikan, Kebudayaan, Riset, dan Teknologi; Sistem Data Pokok Pendidikan; data semester ganjil laporan sampai dengan 30 November 2023

https://tanahbumbukab.bps.go.id

## 4.2 KESEHATAN

**Tabel 4.2.1 Banyaknya Desa[1]/Kelurahan yang Memiliki Sarana Kesehatan Menurut Jenis Sarana Kesehatan di Kecamatan Panyipatan, 2021–2023**

| Jenis Sarana Kesehatan | 2021[2] | 2022[3] | 2023[3] |
|---|---|---|---|
| (1) | (2) | (3) | (4) |
| Rumah Sakit | – | – | – |
| Rumah Sakit Bersalin | – | – | – |
| Poliklinik/Balai Pengobatan | 1 | 1 | – |
| Puskesmas Rawat Inap | – | – | 1 |
| Puskesmas Tanpa Rawat Inap | 2 | 2 | 1 |
| Apotek | – | – | – |

Catatan: [1] Desa pada tabel ini termasuk Unit Permukiman Transmigrasi (UPT) yang masih dibina oleh kementerian terkait
Sumber: [2] Badan Pusat Statistik, Pendataan Potensi Desa (Podes)
[3] Kantor Kecamatan

https://kotabaru.bps.go.id

**Tabel 4.2.2 Banyaknya Warga Penderita Kekurangan Gizi Menurut Desa/Kelurahan di Kecamatan Panyipatan, 2023**

| Desa/Kelurahan | 2023 |
|---|---|
| (1) | (2) |
| Batakan | – |
| Tanjung Dewa | – |
| Kandangan Lama | – |
| Batu Tungku | – |
| Kuringkit | – |
| Bumi Asih | – |
| Batu Mulya | – |
| Suka Ramah | – |
| Panyipatan | – |
| Kandangan Baru | – |
| **Panyipatan** | **–** |

Sumber: Kantor Desa

https://tanahlautkab.bps.go.id

**Tabel 4.2.3** **Jumlah Rumah Sakit Umum, Rumah Sakit Khusus, dan Puskesmas Menurut Desa/Kelurahan di Kecamatan Panyipatan, 2023**

| Desa/Kelurahan | Rumah Sakit Umum | Rumah Sakit Khusus | Puskesmas[1] | Klinik Pratama | Posyandu |
|---|---|---|---|---|---|
| (1) | (2) | (3) | (4) | (5) | (6) |
| Batakan | – | – | 1 | – | ... |
| Tanjung Dewa | – | – | – | – | ... |
| Kandangan Lama | – | – | – | – | ... |
| Batu Tungku | – | – | – | – | ... |
| Kuringkit | – | – | – | – | ... |
| Bumi Asih | – | – | – | – | ... |
| Batu Mulya | – | – | – | – | ... |
| Suka Ramah | – | – | – | – | ... |
| Panyipatan | – | – | 1 | – | ... |
| Kandangan Baru | – | – | – | – | ... |
| **Panyipatan** | **–** | **–** | **2** | **–** | **25** |

Catatan: [1] Puskesmas yang teregistrasi
Sumber: Kantor Kecamatan, Dinas Kesehatan Kabupaten Tanah Laut

https://tanahlautkab.bps.go.id

**Tabel 4.2.4 Banyaknya Tenaga Kesehatan Menurut Desa/Kelurahan di Kecamatan Panyipatan, 2023**

| Desa/Kelurahan | Dokter | Perawat | Bidan | Farmasi | Ahli Gizi |
|---|---|---|---|---|---|
| (1) | (2) | (3) | (4) | (5) | (6) |
| Batakan | ... | ... | ... | ... | ... |
| Tanjung Dewa | ... | ... | ... | ... | ... |
| Kandangan Lama | ... | ... | ... | ... | ... |
| Batu Tungku | ... | ... | ... | ... | ... |
| Kuringkit | ... | ... | ... | ... | ... |
| Bumi Asih | ... | ... | ... | ... | ... |
| Batu Mulya | ... | ... | ... | ... | ... |
| Suka Ramah | ... | ... | ... | ... | ... |
| Panyipatan | ... | ... | ... | ... | ... |
| Kandangan Baru | ... | ... | ... | ... | ... |
| **Panyipatan** | **4** | **22** | **27** | **3** | **3** |

Catatan: [1] Dokter dalam tabel ini termasuk dokter spesialis (selain spesialis gigi) dan dokter umum
Sumber: Kantor Kecamatan, Dinas Kesehatan Kabupaten Tanah Laut

https://tanahlautkab.bps.go.id

**Tabel 4.2.5** **Banyaknya Wanita Usia Subur (WUS) 15–49 Tahun, Pasangan Usia Subur (PUS) Dan Peserta Keluarga Berencana (KB) Menurut Desa/kelurahan di Kecamatan Panyipatan, 2023**

| Desa/Kelurahan | WUS | PUS | Peserta KB |
|---|---|---|---|
| (1) | (2) | (3) | (4) |
| Batakan | 1.150 | 856 | 753 |
| Tanjung Dewa | 779 | 548 | 493 |
| Kandangan Lama | 652 | 476 | 367 |
| Batu Tungku | 683 | 506 | 427 |
| Kuringkit | 442 | 314 | 266 |
| Bumi Asih | 472 | 352 | 317 |
| Batu Mulya | 503 | 362 | 275 |
| Suka Ramah | 604 | 460 | 397 |
| Panyipatan | 619 | 500 | 457 |
| Kandangan Baru | 453 | 351 | 315 |
| **Panyipatan** | **6.357** | **4.725** | **4.067** |

Sumber: Dinas Pengendalian Penduduk, Keluarga Berencana, Pemberdayaan Perempuan dan Perlindungan Anak Kabupaten Tanah Laut

https://tanahlautkab.bps.go.id

## 4.3 PERUMAHAN DAN LINGKUNGAN

**Tabel 4.3.1 Banyaknya Desa[1]/Kelurahan Menurut Sumber Air Minum Sebagian Besar Keluarga di Kecamatan Panyipatan, 2021–2023**

| Sumber Air Minum | 2021[2] | 2022[3] | 2023[3] |
|---|---|---|---|
| (1) | (2) | (3) | (4) |
| Air Kemasan Bermerk | – | – | – |
| Air Isi Ulang | – | – | – |
| Leding dengan Meteran | – | – | – |
| Leding Tanpa Meteran | – | – | – |
| Sumur Bor atau Pompa | 1 | 1 | 1 |
| Sumur | 9 | 9 | 9 |
| Mata Air | – | – | – |
| Sungai/Danau/Kolam/ Waduk/Situ/ Embung/Bendungan | – | – | – |
| Air Hujan | – | – | – |
| Lainnya | – | – | – |

Catatan: [1] Desa pada tabel ini termasuk Unit Permukiman Transmigrasi (UPT) yang masih dibina oleh kementerian terkait

Sumber: [2] Badan Pusat Statistik, Pendataan Potensi Desa (Podes)

[3] Kantor Desa

https://tanahlautkab.bps.go.id

**Tabel 4.3.2** **Banyaknya Keluarga Menurut Desa/Kelurahan dan Jenis Pengguna Listrik di Kecamatan Panyipatan, 2023**

| Desa/Kelurahan | Pengguna Listrik | | | Bukan Pengguna Listrik |
|---|---|---|---|---|
| | PLN | Non-PLN | Jumlah | |
| (1) | (2) | (3) | (4) | (5) |
| Batakan | 2.044 | 9 | 2.053 | – |
| Tanjung Dewa | 991 | – | 991 | – |
| Kandangan Lama | 880 | – | 880 | 5 |
| Batu Tungku | 986 | – | 986 | – |
| Kuringkit | 583 | – | 583 | – |
| Bumi Asih | 609 | – | 609 | – |
| Batu Mulya | 609 | – | 609 | – |
| Suka Ramah | 870 | 1 | 871 | – |
| Panyipatan | 1.038 | – | 1.038 | – |
| Kandangan Baru | 638 | – | 638 | 1 |
| **Panyipatan** | **9.248** | **10** | **9.258** | **6** |

Sumber: BPS, Pendataan Potensi Desa (Podes)

https://tanahlautkab.bps.go.id

**Tabel 4.3.3 Banyaknya Desa/Kelurahan Menurut Sumber Penerangan Jalan Utama Desa/Kelurahan di Kecamatan Panyipatan, 2021–2023**

| Sumber Penerangan Jalan Utama | 2021[2] | 2022[3] | 2023[3] |
|---|---|---|---|
| (1) | (2) | (3) | (4) |
| Listrik Pemerintah | 10 | 10 | 10 |
| Listrik Non-Pemerintah | – | – | – |
| Non Listrik | – | – | – |

Catatan: [1] Desa pada tabel ini termasuk Unit Permukiman Transmigrasi (UPT) yang masih dibina oleh kementerian terkait
Sumber: [2] Badan Pusat Statistik, Pendataan Potensi Desa (Podes)
[3] Kantor Desa

https://tanahlautkab.bps.go.id

**Tabel 4.3.4 Banyaknya Desa/Kelurahan Menurut Penggunaan Fasilitas Tempat Buang Air Besar Sebagian Besar Keluarga di Kecamatan Panyipatan, 2021–2023**

| Fasilitas Tempat Buang Air Besar | 2021[2] | 2022[3] | 2023[3] |
|---|---|---|---|
| (1) | (2) | (3) | (4) |
| **Jamban** | 10 | 10 | 10 |
| Sendiri | 10 | 10 | 10 |
| Bersama | – | – | – |
| Umum | – | – | – |
| | | | |
| **Bukan Jamban** | – | – | – |
| **Jumlah** | **10** | **10** | **10** |

Catatan: [1] Desa pada tabel ini termasuk Unit Permukiman Transmigrasi (UPT) yang masih dibina oleh kementerian terkait
Sumber: [2] Badan Pusat Statistik, Pendataan Potensi Desa (Podes)
[3] Kantor Desa

https://tanahlautkab.bps.go.id

**Tabel 4.3.5 Banyaknya Desa/Kelurahan Menurut Jenis Bahan Bakar untuk Memasak yang Digunakan Sebagian Besar Keluarga di Kecamatan Panyipatan, 2023**

| Jenis Bahan Bakar untuk Memasak | 2023 |
|---|---|
| (1) | (2) |
| Listrik | – |
| Elpiji 5,5 kg | – |
| Elpiji 12 kg | – |
| Elpiji 3 kg | 10 |
| Gas Kota | – |
| Biogas | – |
| Minyak Tanah | – |
| Briket | – |
| Arang | – |
| Kayu Bakar | – |
| Lainnya | – |
| **Jumlah** | **10** |

Sumber: Kantor Desa

https://tanahlautkab.bps.go.id

## 4.4 AGAMA DAN SOSIAL LAINNYA

**Tabel 4.4.1 Jumlah Tempat Peribadatan Menurut Desa/Kelurahan di Kecamatan Panyipatan, 2023**

| Desa/Kelurahan | Masjid | Mushola | Gereja Protestan | Gereja Katholik | Pura | Vihara |
|---|---|---|---|---|---|---|
| (1) | (2) | (3) | (4) | (5) | (6) | (7) |
| Batakan | 1 | 14 | – | – | – | – |
| Tanjung Dewa | 1 | 5 | – | – | – | – |
| Kandangan Lama | 1 | 4 | – | – | – | – |
| Batu Tungku | 3 | 9 | 1 | – | – | – |
| Kuringkit | 1 | 4 | – | – | – | – |
| Bumi Asih | 3 | 6 | 2 | – | – | – |
| Batu Mulya | 3 | 7 | – | 1 | – | – |
| Suka Ramah | 4 | 2 | – | – | – | – |
| Panyipatan | 2 | 3 | – | – | – | – |
| Kandangan Baru | 1 | 3 | – | – | – | – |
| **Panyipatan** | **20** | **57** | **3** | **1** | **–** | **–** |

Sumber: Kantor Desa

https://tanahlautkab.bps.go.id

**Tabel 4.4.2 Banyaknya Kejadian Bencana Alam Menurut Desa/ Kelurahan dan Jenis Bencana Alam di Kecamatan Panyipatan, 2023**

| Desa/Kelurahan | Gempa Bumi | Tsunami | Gunung Meletus | Tanah Longsor |
|---|---|---|---|---|
| (1) | (2) | (3) | (4) | (5) |
| Batakan | – | – | – | – |
| Tanjung Dewa | – | – | – | – |
| Kandangan Lama | – | – | – | – |
| Batu Tungku | – | – | – | – |
| Kuringkit | – | – | – | – |
| Bumi Asih | – | – | – | – |
| Batu Mulya | – | – | – | – |
| Suka Ramah | – | – | – | – |
| Panyipatan | – | – | – | – |
| Kandangan Baru | – | – | – | – |
| **Panyipatan** | **–** | **–** | **–** | **–** |

https://tanahlautkab.bps.go.id

Lanjutan Tabel 4.4.2

| Desa/Kelurahan | Banjir | Banjir Bandang | Kekeringan | Kebakaran Hutan dan Lahan |
|---|---|---|---|---|
| (1) | (6) | (7) | (8) | (9) |
| Batakan | – | – | – | – |
| Tanjung Dewa | – | – | – | – |
| Kandangan Lama | – | – | – | – |
| Batu Tungku | – | – | – | – |
| Kuringkit | – | – | – | – |
| Bumi Asih | – | – | – | – |
| Batu Mulya | – | – | – | – |
| Suka Ramah | – | – | – | – |
| Panyipatan | – | – | – | – |
| Kandangan Baru | – | – | – | – |
| **Panyipatan** | **–** | **–** | **–** | **–** |

https://tanahlautkab.bps.go.id

Lanjutan Tabel 4.4.2

| Desa/Kelurahan | Angin Puyuh/ Puting Beliung/ Topan | Gelombang Pasang | Abrasi |
|---|---|---|---|
| (1) | (10) | (11) | (12) |
| Batakan | – | – | – |
| Tanjung Dewa | – | – | – |
| Kandangan Lama | – | – | – |
| Batu Tungku | – | – | – |
| Kuringkit | – | – | – |
| Bumi Asih | – | – | – |
| Batu Mulya | – | – | – |
| Suka Ramah | – | – | – |
| Panyipatan | – | – | – |
| Kandangan Baru | – | – | – |
| **Panyipatan** | **–** | **–** | **–** |

Sumber: Kantor Desa

https://tanahlautkab.bps.go.id

**Tabel 4.4.3** **Banyaknya Korban Jiwa Akibat Bencana Alam Menurut Desa/Kelurahan dan Jenis Bencana Alam di Kecamatan Panyipatan, 2023**

| Desa/Kelurahan | Gempa Bumi | Tsunami | Gunung Meletus | Tanah Longsor |
|---|---|---|---|---|
| (1) | (2) | (3) | (4) | (5) |
| Batakan | – | – | – | – |
| Tanjung Dewa | – | – | – | – |
| Kandangan Lama | – | – | – | – |
| Batu Tungku | – | – | – | – |
| Kuringkit | – | – | – | – |
| Bumi Asih | – | – | – | – |
| Batu Mulya | – | – | – | – |
| Suka Ramah | – | – | – | – |
| Panyipatan | – | – | – | – |
| Kandangan Baru | – | – | – | – |
| **Panyipatan** | **–** | **–** | **–** | **–** |

https://tanahlautkab.bps.go.id

Lanjutan Tabel 4.4.3

| Desa/Kelurahan | Banjir | Banjir Bandang | Kekeringan | Kebakaran Hutan dan Lahan |
|---|---|---|---|---|
| (1) | (6) | (7) | (8) | (9) |
| Batakan | – | – | – | – |
| Tanjung Dewa | – | – | – | – |
| Kandangan Lama | – | – | – | – |
| Batu Tungku | – | – | – | – |
| Kuringkit | – | – | – | – |
| Bumi Asih | – | – | – | – |
| Batu Mulya | – | – | – | – |
| Suka Ramah | – | – | – | – |
| Panyipatan | – | – | – | – |
| Kandangan Baru | – | – | – | – |
| **Panyipatan** | **–** | **–** | **–** | **–** |

https://tanahlautkab.bps.go.id

Lanjutan Tabel 4.4.3

| Desa/Kelurahan | Angin Puyuh/ Puting Beliung/ Topan | Gelombang Pasang | Abrasi |
|---|---|---|---|
| (1) | (10) | (11) | (12) |
| Batakan | – | – | – |
| Tanjung Dewa | – | – | – |
| Kandangan Lama | – | – | – |
| Batu Tungku | – | – | – |
| Kuringkit | – | – | – |
| Bumi Asih | – | – | – |
| Batu Mulya | – | – | – |
| Suka Ramah | – | – | – |
| Panyipatan | – | – | – |
| Kandangan Baru | – | – | – |
| **Panyipatan** | **–** | **–** | **–** |

Sumber: Kantor Desa

https://tanahlautkab.bps.go.id

**Tabel 4.4.4 Keberadaan Fasilitas/Upaya Antisipasi/Mitigasi Bencana Alam Menurut Desa/Kelurahan di Kecamatan Panyipatan, 2023**

| Desa/Kelurahan | Sistem Peringatan Dini Bencana Alam | Sistem Peringatan Dini Khusus Tsunami | Perlengkapan Keselamatan |
|---|---|---|---|
| (1) | (2) | (3) | (4) |
| Batakan | Tidak Ada | Bukan Wilayah Potensi Tsunami | Ada |
| Tanjung Dewa | Tidak Ada | Bukan Wilayah Potensi Tsunami | Tidak Ada |
| Kandangan Lama | Tidak Ada | Bukan Wilayah Potensi Tsunami | Tidak Ada |
| Batu Tungku | Tidak Ada | Bukan Wilayah Potensi Tsunami | Tidak Ada |
| Kuringkit | Tidak Ada | Bukan Wilayah Potensi Tsunami | Tidak Ada |
| Bumi Asih | Tidak Ada | Bukan Wilayah Potensi Tsunami | Tidak Ada |
| Batu Mulya | Tidak Ada | Bukan Wilayah Potensi Tsunami | Tidak Ada |
| Suka Ramah | Tidak Ada | Bukan Wilayah Potensi Tsunami | Tidak Ada |
| Panyipatan | Tidak Ada | Bukan Wilayah Potensi Tsunami | Ada |
| Kandangan Baru | Tidak Ada | Bukan Wilayah Potensi Tsunami | Tidak Ada |

https://tanbalautkab.bps.go.id

Lanjutan Tabel 4.4.4

| Desa/Kelurahan | Rambu-Rambu dan Jalur Evakuasi Bencana | Pembuatan, Perawatan, atau Normalisasi: Sungai, Kanal, Tanggul, Parit, Drainase, Waduk, Pantai, dll |
|---|---|---|
| (1) | (5) | (6) |
| Batakan | Ada | Ada |
| Tanjung Dewa | Tidak Ada | Tidak Ada |
| Kandangan Lama | Tidak Ada | Tidak Ada |
| Batu Tungku | Ada | Ada |
| Kuringkit | Tidak Ada | Tidak Ada |
| Bumi Asih | Tidak Ada | Ada |
| Batu Mulya | Tidak Ada | Tidak Ada |
| Suka Ramah | Tidak Ada | Tidak Ada |
| Panyipatan | Ada | Ada |
| Kandangan Baru | Tidak Ada | Ada |

Sumber: Kantor Desa

https://tanahbumbukab.bps.go.id

**Tabel 4.4.5 Banyaknya Desa/Kelurahan yang Memiliki Kelompok Kegiatan Olahraga Menurut Jenis Olahraga dan Ketersedian Fasilitas/Lapangan Olahraga di Kecamatan Panyipatan, 2023**

| Jenis Olahraga | Kondisi Fasilitas/Lapangan Olahraga | | | Tidak Ada Fasilitas/ Lapangan Olahraga |
|---|---|---|---|---|
| | Baik | Rusak Sedang | Rusak Parah | |
| (1) | (2) | (3) | (4) | (5) |
| Sepak Bola | 7 | 3 | – | – |
| Bola Voli | 4 | 3 | – | 3 |
| Bulu Tangkis | 3 | – | – | 7 |
| Bola Basket | – | – | – | 10 |
| Tenis Lapangan | – | – | – | 10 |
| Tenis Meja | 1 | – | – | 9 |
| Futsal | – | – | – | 10 |
| Renang | – | – | – | 10 |
| Bela Diri | 1 | – | – | 9 |
| Bilyard | – | 1 | – | 9 |
| Fitnes, Aerobik, dll | – | – | – | 10 |
| Lainnya | – | – | – | 10 |

Sumber: Kantor Desa

https://tanahlautkab.bps.go.id

**Tabel 4.4.6 Banyaknya Perkara Kejahatan/Pelanggaran yang Dilaporkan ke Kepolisian dan yang Diselesaikan di Kecamatan Panyipatan, 2023**

| Jenis Kejahatan/Pelanggaran | Dilaporkan | Diselesaikan |
|---|---|---|
| (1) | (2) | (3) |
| Pencurian Ringan | ... | ... |
| Penipuan | ... | ... |
| Kebakaran | ... | ... |
| Penggelapan | ... | ... |
| Penganiayaan Berat | ... | ... |
| Penadahan | ... | ... |
| Perjudian | ... | ... |
| Perkosaan | ... | ... |
| Pelanggaran Lalu Lintas | ... | ... |
| Lain-Lain | ... | ... |
| **Jumlah** | **...** | **...** |

Sumber: Kepolisian Resor Kabupaten Tanah Laut

https://tanahlautkab.bps.go.id

**Tabel 4.4.7 Jumlah Pondok Pesantren, Jumlah Santri dan Guru/Kyai Menurut Desa/Kelurahan di Kecamatan Panyipatan, 2023**

| Desa/Kelurahan | Pondok Pesantren | Santri | Guru/Kyai |
|---|---|---|---|
| (1) | (2) | (3) | (4) |
| Batakan | – | – | – |
| Tanjung Dewa | 1 | 254 | 25 |
| Kandangan Lama | – | – | – |
| Batu Tungku | 1 | 94 | 9 |
| Kuringkit | – | – | – |
| Bumi Asih | – | – | – |
| Batu Mulya | 1 | 518 | 2 |
| Suka Ramah | – | – | – |
| Panyipatan | – | – | – |
| Kandangan Baru | – | – | – |
| **Panyipatan** | **3** | **866** | **36** |

Sumber: Kementerian Agama, EMIS, data semester ganjil tahun ajaran 2023/2024

https://tanahlautkab.bps.go.id

**Tabel 4.4.8 Jumlah Penduduk Menurut Desa/Kelurahan dan Agama yang Dianut di Kecamatan Panyipatan, 2023**

| Desa/Kelurahan | Islam | Protestan | Katolik | Hindu | Budha | Lainnya |
|---|---|---|---|---|---|---|
| (1) | (2) | (3) | (4) | (5) | (6) | (7) |
| Batakan | 5.571 | ... | ... | ... | ... | ... |
| Tanjung Dewa | 3.188 | ... | ... | ... | ... | ... |
| Kandangan Lama | 2.554 | ... | ... | ... | ... | ... |
| Batu Tungku | 2.499 | 20 | ... | ... | ... | ... |
| Kuringkit | 1.756 | 2 | ... | ... | ... | ... |
| Bumi Asih | 1.755 | 38 | ... | ... | ... | ... |
| Batu Mulya | 1.828 | 80 | ... | ... | ... | ... |
| Suka Ramah | 2.268 | 5 | 7 | ... | ... | ... |
| Panyipatan | 2.509 | ... | ... | ... | ... | ... |
| Kandangan Baru | 1.771 | ... | ... | ... | ... | ... |
| **Panyipatan** | **25.699** | **145** | **7** | **–** | **–** | **–** |

Catatan: Lainnya termasuk agama Konghucu
Sumber: Kantor Kementerian Agama Kab. Tanah Laut, Kantor Desa

https://tanahlautkab.bps.go.id

**Tabel 4.4.9 Banyaknya Nikah, Talak, Cerai, dan Rujuk Menurut Desa/ Kelurahan di Kecamatan Panyipatan, 2023**

| Desa/Kelurahan | Nikah | Talak | Cerai | Rujuk |
|---|---|---|---|---|
| (1) | (2) | (3) | (4) | (5) |
| Batakan | 40 | ... | ... | ... |
| Tanjung Dewa | 32 | ... | ... | ... |
| Kandangan Lama | 20 | ... | ... | ... |
| Batu Tungku | 20 | ... | ... | ... |
| Kuringkit | 16 | ... | ... | ... |
| Bumi Asih | 11 | ... | ... | ... |
| Batu Mulya | 14 | ... | ... | ... |
| Suka Ramah | 14 | ... | ... | ... |
| Panyipatan | 21 | ... | ... | ... |
| Kandangan Baru | 11 | ... | ... | ... |
| **Panyipatan** | **199** | **9** | **41** | **...** |

Sumber: KUA Kecamatan, Kantor Kementerian Agama Kab. Tanah Laut, Pengadilan Agama Pelaihari

https://tanahlautkab.bps.go.id

**Tabel 4.4.10 Banyaknya Nikah, Talak, Cerai, dan Rujuk Menurut Bulan di Kecamatan Panyipatan, 2023**

| Bulan | Nikah | Talak | Cerai | Rujuk |
|---|---|---|---|---|
| (1) | (2) | (3) | (4) | (5) |
| Januari | 16 | ... | ... | ... |
| Februari | 15 | ... | ... | ... |
| Maret | 40 | ... | ... | ... |
| April | 12 | ... | ... | ... |
| Mei | 10 | ... | ... | ... |
| Juni | 11 | ... | ... | ... |
| Juli | 19 | ... | ... | ... |
| Agustus | 11 | ... | ... | ... |
| September | 27 | ... | ... | ... |
| Oktober | 12 | ... | ... | ... |
| November | 14 | ... | ... | ... |
| Desember | 12 | ... | ... | ... |
| **Jumlah** | **199** | **9** | **41** | **...** |

Sumber: KUA Kecamatan, Kantor Kementerian Agama Kab. Tanah Laut, Pengadilan Agama Pelaihari

https://tanahlautkab.bps.go.id

# BAB 5
# PERTANIAN

https://bontokab.bps.go.id

https://tanahlautkab.bps.go.id

## PENJELASAN TEKNIS

1. Tanaman sayuran dan buah-buahan semusim

- Tanaman sayuran semusim adalah tanaman yang bermanfaat sebagai sayur, sebagai sumber vitamin, mineral, dan lain-lain yang berumur kurang dari satu tahun. Pada umumnya, bagian yang digunakan sebagai sayur berupa daun, bunga, buah, dan umbi.
- Tanaman buah-buahan semusim adalah tanaman yang menghasilkan buah segar sebagai sumber vitamin, mineral, dan lain-lain yang berumur kurang dari satu tahun dan berbatang lunak. Pada umumnya, buah yang dihasilkan dapat dikonsumsi tanpa dimasak terlebih dahulu.

2. Tanaman buah-buahan dan sayuran tahunan

- Tanaman buah-buahan tahunan adalah tanaman yang menghasilkan buah segar sebagai sumber vitamin, mineral, dan lain-lain yang berumur satu tahun atau lebih dan berbatang keras. Pada umumnya, buah yang dihasilkan dapat dikonsumsi tanpa dimasak terlebih dahulu.
- Tanaman sayuran tahunan adalah tanaman yang bermanfaat sebagai sayur, sebagai sumber vitamin, mineral, dan lain-lain yang berumur satu tahun atau lebih. Pada umumnya, bagian yang digunakan sebagai sayur berupa daun, bunga, buah, dan umbi.

3. Tanaman biofarmaka adalah tanaman yang bermanfaat untuk obat-obatan, kosmetik, dan kesehatan yang dikonsumsi atau digunakan dari bagian-bagian tanaman seperti daun, batang, buah, umbi (rimpang) ataupun akar.

4. Tanaman hias adalah tanaman yang mempunyai nilai keindahan baik bentuk, warna daun, tajuk maupun bunganya untuk penghias pekarangan dan lain sebagainya.

5. Luas panen tanaman hortikultura adalah luas tanaman sayuran, buah-buahan, biofarmaka, dan tanaman hias yang diambil hasilnya/dipanen pada periode pelaporan.

6. Luas panen untuk tanaman sayuran adalah luas tanaman yang dipanen sekaligus/habis/dibongkar dan luas tanaman yang dipanen berkali-kali (lebih dari satu kali)/belum habis.

- Tanaman yang dipanen sekaligus/habis/dibongkar adalah tanaman yang sehabis panen langsung dibongkar/dicabut, terdiri dari bawang merah,bawang putih, bawang daun, kentang, kol/kubis, kembang kol,

https://www.bps.go.id

petsai/sawi, wortel, lobak, dan kacang merah.

- Tanaman yang dipanen berkali-kali (lebih dari satu kali)/belum habis adalah tanaman yang pemanennya lebih dari satu kali dan biasanya dibongkar apabila panenan terakhir sudah tidak memadai lagi, terdiri dari : kacang panjang, cabe besar, cabe rawit, jamur, tomat, terung, buncis, ketimun, labu siam, kangkung, bayam, melon, dan semangka.

7. Produksi hortikultura adalah hasil menurut bentuk produk dari setiap tanaman sayuran, buah-buahan, biofarmaka dan tanaman hias yang diambil berdasarkan luas yang dipanen/tanaman yang menghasilkan pada bulan/triwulan laporan.

8. Tanaman perkebunan tahunan adalah tanaman perkebunan yang umumnya berumur lebih dari satu tahun dan pemungutan hasilnya dilakukan lebih dari satu kali dan tidak dibongkar sekali panen.

9. Tanaman perkebunan semusim adalah tanaman perkebunan yang pada umumnya berumur kurang dari satu tahun dan pemanenannya dilakukan satu kali atau beberapa kali masa panen.

10. Produksi Perkebunan adalah hasil dari setiap tanaman tahunan atau semusim menurut bentuk produksi (hasil) yang diambil berdasarkan luas yang dipanen pada periode laporan.

11. Bentuk produksi perkebunan meliputi karet kering (karet), kopra (kelapa), minyak kelapa sawit (kelapa sawit), biji kering (kopi dan kakao), daun kering (teh dan tembakau), bunga kering (cengkeh), gelondong kering (jambu mete), biji kering (pala), lada kering (lada), gula kristal putih (tebu), dan minyak nilam (nilam).

12. Data populasi dan produksi ternak berasal dari Direktorat Jenderal Peternakan dan Kesehatan Hewan, Kementerian Pertanian. Produksi daging sapi, kerbau, kuda, kambing, domba, dan babi dalam bentuk karkas ditambah edible portion, dihitung berdasarkan pemotongan ternak tercatat (di RPH, selain di RPH, Qurban) dan pemotongan ternak tidak tercatat.

13. Pemotongan ternak tercatat adalah pemotongan ternak yang dilakukan di Rumah Potong Hewan Ruminansia (RPH-R), Rumah Potong Hewan Babi (RPHB), dan Rumah Potong Hewan Unggas (RPH-U), baik milik pemerintah maupun swasta, serta tempat pemotongan hewan selain RPH yang

https://kotanlebukab.bps.go.id

dilaporkan kepada dinas atau dicatat oleh dinas yang membidangi fungsi peternakan dan kesehatan hewan setempat.

14. Pemotongan ternak tidak tercatat adalah pemotongan yang dilakukan oleh orang perorangan yang tidak dilaporkan kepada dinas atau tidak dicatat oleh dinas yang membidangi fungsi peternakan dan kesehatan hewan setempat.

https://tanahlautkab.bps.go.id

https://tanahlautkab.bps.go.id

## ULASAN

Luas panen dan produksi tanaman sayuran semusim cabai rawit pada tahun 2023 di Kecamatan Panyipatan yaitu 26 hektar dan produksi 1.477 kuintal, sedangkan cabai besar dengan luas panen 27 hektar memproduksi 1.041 kuintal. Produksi buah-buahan tahunan pisang sebanyak 1.465 kuintal. Produksi tanaman biofarmaka terbesar di Kecamatan panyipatan yaitu kunyit dengan luas panen 6 $m^2$ total produksi 75 kg. Komoditas perkebunan unggulan di Kecamatan Panyipatan adalah kelapa sawit. Produksi tanaman kelapa sawit di Kecamatan Panyipatan tahun 2023 sebanyak 2.463,3 ton. Populasi unggas terbesar di Kecamatan Panyipatan yaitu ayam pedaging dengan total 4.825.465 ekor sedangkan populasi ternak besar yaitu sapi potong dengan total 16.777 ekor ternak.

https://tanahlautkab.bps.go.id

**Tabel 5.1** **Luas Panen Tanaman Sayuran dan Buah-buahan Semusim Menurut Jenis Tanaman di Kecamatan Panyipatan (ha), 2020–2023**

| Jenis Tanaman | 2020 | 2021 | 2022 | 2023 |
|---|---|---|---|---|
| (1) | (2) | (3) | (4) | (5) |
| **Sayuran:** | | | | |
| Bawang Merah | – | 2 | – | 8 |
| Cabai Besar | 14 | 20 | 14 | 27 |
| Cabai Keriting | – | – | 5 | 16 |
| Cabai Rawit | 22 | 26 | 20 | 26 |
| Kentang | – | – | – | – |
| Kubis | – | – | – | – |
| Tomat | 8 | 15 | 13 | 16 |
| Bawang Putih | – | – | – | – |
| Terung | 15 | 16 | 16 | 14 |
| | | | | |
| **Buah-buahan:** | | | | |
| Semangka | 3 | 2 | 8 | 1 |

Sumber: Badan Pusat Statistik, Statistik Pertanian Hortikultura SPH-SBS

https://tanahlautkab.bps.go.id

**Tabel 5.2** **Produksi Tanaman Sayuran dan Buah-buahan Semusim Menurut Jenis Tanaman di Kecamatan Panyipatan (kuintal), 2020–2023**

| Jenis Tanaman | 2020 | 2021 | 2022 | 2023 |
|---|---|---|---|---|
| (1) | (2) | (3) | (4) | (5) |
| **Sayuran:** | | | | |
| Bawang Merah | – | 15 | – | 185 |
| Cabai Besar | 309 | 763 | 535 | 1.041 |
| Cabai Keriting | – | – | 230 | 474 |
| Cabai Rawit | 514 | 891 | 800 | 1.477 |
| Kentang | – | – | – | – |
| Kubis | – | – | – | – |
| Tomat | 239 | 568 | 420 | 510 |
| Bawang Putih | – | – | – | – |
| Terung | 440 | 660 | 480 | 374 |
| | | | | |
| **Buah-buahan:** | | | | |
| Semangka | 190 | 450 | 1.145 | 35 |

Sumber: Badan Pusat Statistik, Statistik Pertanian Hortikultura SPH-SBS

https://kanahlautkab.bps.go.id

**Tabel 5.3** **Luas Panen Tanaman Biofarmaka Menurut Jenis Tanaman di Kecamatan Panyipatan ($m^2$), 2020–2023**

| Jenis Tanaman | 2020 | 2021 | 2022 | 2023 |
|---|---|---|---|---|
| (1) | (2) | (3) | (4) | (5) |
| Jahe | 77 | 12 | 7 | 3 |
| Laos/Lengkuas | 1 | 5 | 2 | 3 |
| Kencur | 29 | 5 | 4 | 5 |
| Kunyit | 26 | 6 | 5 | 6 |

Sumber: Badan Pusat Statistik, Statistik Pertanian Hortikultura SPH-TBF

https://tanahlautkab.bps.go.id

**Tabel 5.4** **Produksi Tanaman Biofarmaka Menurut Jenis Tanaman di Kecamatan Panyipatan (kg), 2020–2023**

| Jenis Tanaman | 2020 | 2021 | 2022 | 2023 |
|---|---|---|---|---|
| (1) | (2) | (3) | (4) | (5) |
| Jahe | 260 | 225 | 130 | 30 |
| Laos/Lengkuas | 4 | 48 | 27 | 19 |
| Kencur | 69 | 69 | 40 | 50 |
| Kunyit | 75 | 80 | 50 | 75 |

Sumber: Badan Pusat Statistik, Statistik Pertanian Hortikultura SPH-TBF

https://tanahlautkab.bps.go.id

**Tabel 5.5 Luas Panen Tanaman Hias Menurut Jenis Tanaman di Kecamatan Panyipatan ($m^2$), 2020–2023**

| Jenis Tanaman | 2020 | 2021 | 2022 | 2023 |
|---|---|---|---|---|
| (1) | (2) | (3) | (4) | (5) |
| Anggrek Pot | – | – | – | – |
| Anggrek Potong | – | – | – | – |
| Krisan | – | – | – | – |
| Mawar | – | – | – | – |
| Sedap Malam | – | – | – | – |

Sumber: Badan Pusat Statistik, Statistik Pertanian Hortikultura SPH-TH

https://tanahlautkab.bps.go.id

**Tabel 5.6 Produksi Tanaman Hias Menurut Jenis Tanaman di Kecamatan Panyipatan (tangkai), 2020–2023**

| Jenis Tanaman | 2020 | 2021 | 2022 | 2023 |
|---|---|---|---|---|
| (1) | (2) | (3) | (4) | (5) |
| Anggrek Pot | – | – | – | – |
| Anggrek Potong | – | – | – | – |
| Krisan | – | – | – | – |
| Mawar | – | – | – | – |
| Sedap Malam | – | – | – | – |

Sumber: Badan Pusat Statistik, Statistik Pertanian Hortikultura SPH-TH

https://tanahlautkab.bps.go.id

**Tabel 5.7** **Produksi Buah-buahan dan Sayuran Tahunan Menurut Jenis Tanaman di Kecamatan Panyipatan (kuintal), 2020–2023**

| Jenis Tanaman | 2020 | 2021 | 2022 | 2023 |
|---|---|---|---|---|
| (1) | (2) | (3) | (4) | (5) |
| **Buah-Buahan:** | | | | |
| Mangga | 1.000 | 80 | 10 | 950 |
| Durian | 4.500 | 70 | – | 175 |
| Jeruk Siam/Keprok | 704 | 65 | 8 | 15 |
| Pisang | 8.500 | 2.120 | 765 | 1.465 |
| Pepaya | 470 | 395 | 505 | 1.025 |
| Nenas | 22 | 8 | 7 | – |
| Salak | 80 | 30 | 4 | – |
| Nangka/Cempedak | 740 | 245 | 240 | 20 |
| Rambutan | 17.000 | 145 | 1.315 | 515 |
| Buah Naga | – | – | – | – |
| | | | | |
| **Sayuran:** | | | | |
| Petai | 3.100 | 900 | 505 | 760 |
| Jengkol | 20 | 10 | 6 | 40 |
| Melinjo | 220 | 20 | – | – |

Sumber: BPS, Statistik Pertanian Hortikultura SPH-BST

https://tanahlautkab.bps.go.id

**Tabel 5.8** **Luas Areal Tanaman Perkebunan Menurut Jenis Tanaman di Kecamatan Panyipatan (ha), 2020–2023**

| Jenis Tanaman | 2020 | 2021 | 2022 | 2023 |
|---|---|---|---|---|
| (1) | (2) | (3) | (4) | (5) |
| Kelapa Sawit | 360 | 395 | 434 | 464 |
| Kelapa | 46 | 45 | 43 | 37 |
| Karet | 1.026 | 1.031 | 1.033 | 1.030 |
| Kopi | 3,5 | 4 | 4 | 4 |
| Kakao | – | – | – | – |
| Tebu | – | – | – | – |
| Teh | – | – | – | – |
| Tembakau | – | – | – | – |

Sumber: Dinas Tanaman Pangan, Hortikultura dan Perkebunan

https://tanahlautkab.bps.go.id

**Tabel 5.9** **Produksi Tanaman Perkebunan Menurut Jenis Tanaman di Kecamatan Panyipatan (ton), 2020–2023**

| Jenis Tanaman | 2020 | 2021 | 2022 | 2023 |
|---|---|---|---|---|
| (1) | (2) | (3) | (4) | (5) |
| Kelapa Sawit | 626,90 | 819,00 | 1.726,40 | 2.463,30 |
| Kelapa | 37,10 | 45,50 | 86,85 | 107,70 |
| Karet | 445,50 | 415,80 | 838,30 | 1.134,00 |
| Kopi | 2,50 | 3,20 | 6,40 | 9,00 |
| Kakao | – | – | – | – |
| Tebu | – | – | – | – |
| Teh | – | – | – | – |
| Tembakau | – | – | – | – |

Sumber: Dinas Tanaman Pangan, Hortikultura dan Perkebunan

https://tanahlautkab.bps.go.id

**Tabel 5.10 Populasi Unggas Menurut Jenisnya di Kecamatan Panyipatan (ekor), 2020–2023**

| Jenis Unggas | 2020 | 2021 | 2022 | 2023 |
|---|---|---|---|---|
| (1) | (2) | (3) | (4) | (5) |
| Ayam Kampung | 708.501 | 1.045.655 | 157.219 | 239.100 |
| Ayam Petelur | 165.014 | 191.747 | 40.463 | – |
| Ayam Pedaging | 5.269.047 | 4.579.463 | 7.995.215 | 4.825.465 |
| Itik | 28.624 | 34.052 | 22.297 | 7.581 |
| Burung Puyuh | – | – | – | – |

Sumber: Dinas Peternakan dan Kesehatan Hewan

https://tanahlautkab.bps.go.id

**Tabel 5.11 Produksi Daging Ternak Unggas di Kecamatan Panyipatan (kg), 2020–2023**

| Jenis Unggas | 2020 | 2021 | 2022 | 2023 |
|---|---|---|---|---|
| (1) | (2) | (3) | (4) | (5) |
| Ayam Kampung | 46.281 | 41.967 | 53.846 | 142.005 |
| Ayam Petelur | 8.092 | 8.796 | 44.285 | – |
| Ayam Pedaging | ... | ... | 2.864.361 | 2.612.281 |
| Itik | 21.651 | 19.929 | 31.675 | 14.600 |
| Burung Puyuh | – | – | – | – |

Sumber: Dinas Peternakan dan Kesehatan Hewan

https://tanahlautkab.bps.go.id

**Tabel 5.12** **Populasi Ternak Besar dan Kecil Menurut Jenisnya di Kecamatan Panyipatan (ekor), 2020–2023**

| Jenis Ternak | 2020 | 2021 | 2022 | 2023 |
|---|---|---|---|---|
| (1) | (2) | (3) | (4) | (5) |
| Sapi Perah | – | – | – | – |
| Sapi Potong | 18.363 | 13.868 | 15.148 | 16.777 |
| Kerbau | 247 | 99 | 39 | 50 |
| Kuda | 52 | 56 | 56 | 56 |
| Kambing | 5.297 | 5.360 | 2.396 | 1.157 |
| Domba | – | 5 | 2 | 3 |
| Babi | – | – | – | – |

Sumber: Dinas Peternakan dan Kesehatan Hewan

https://tanahlautkab.bps.go.id

https://tanahlautkab.bps.go.id

# BAB 6
# PARIWISATA, TRANSPORTASI, DAN KOMUNIKASI

https://karawangkab.bps.go.id

https://tanahlautkab.bps.go.id

## PENJELASAN TEKNIS

1. Konsep dan definisi pariwisata mengikuti rekomendasi *United Nations World Tourism Organization* (UNWTO).

2. Usaha penyediaan akomodasi adalah usaha yang menyediakan pelayanan penginapan yang dapat dilengkapi dengan pelayanan pariwisata lainnya. Usaha penyediaan akomodasi dapat berupa hotel, vila, pondok wisata, bumi perkemahan, persinggahan karavan, dan akomodasi lainnya yang digunakan untuk tujuan pariwisata.

3. Hotel adalah penyediaan akomodasi secara harian berupa kamar-kamar di dalam satu bangunan yang dapat dilengkapi dengan jasa pelayanan makan dan minum, kegiatan hiburan dan atau fasilitas lainnya. Hotel terdiri dari hotel berbintang dan hotel non- bintang.

4. Data transportasi dan komunikasi meliputi:
   a. Panjang jalan
   b. Angkutan darat
   c. Angkutan laut
   d. Angkutan udara
   e. Pos dan telekomunikasi

5. Kendaraan bermotor adalah setiap kendaraan yang digerakkan oleh peralatan teknik yang ada pada kendaraan tersebut, biasanya digunakan untuk angkutan orang atau barang di atas jalan raya selain kendaraan yang berjalan di atas rel. Kendaraan bermotor yang dicatat adalah semua jenis kendaraan kecuali kendaraan bermotor TNI/Polri dan Korps Diplomatik.

6. Kantor Pos adalah tempat pemberi pelayanan komunikasi tertulis dan atau surat elektronik, layanan paket, layanan logistik, layanan transaksi keuangan, dan layanan keagenan pos untuk kepentingan umum. Rumah pos berfungsi sama seperti kantor pos dan kantor pos pembantu, bedanya rumah pos biasanya terletak di daerah terpencil.

7. Telekomunikasi meliputi setiap pemancaran, penyampaian dan atau penerimaan dari setiap informasi berupa penandaan, isyarat, tulisan, gambar, suara dan suara melalui untaian kawat melalui sistem kabel, optik, radio atau sistem elektromagnetik lainnya.

https://tanahlautkab.bps.go.id

8. Jaringan telekomunikasi adalah rangkaian perangkat telekomunikasi dan kelengkapannya yang digunakan dalam bertelekomunikasi.

9. Internet adalah jaringan komunikasi elektronik yang menghubungkan jaringan komputer dan fasilitas komputer yang terorganisasi di seluruh dunia melalui telepon atau satelit.

https://tanahlautkab.bps.go.id

## ULASAN

Pada Kecamatan Panyipatan terdapat 38 akomodasi penginapan. Sarana transportasi antar desa di Kecamatan Panyipatan dapat ditempuh melalui jalur darat dengan jenis permukaan jalan aspal/beton. Jalan antar desa ini umumnya dapat dilalui kendaraan roda empat atau lebih sepanjang tahun.

Seluruh desa di Kecamatan Panyipatan sudah dijangkau oleh layanan operator seluler. Namun di Desa Batu Tungku, Kuringkit, dan Kandangan Lama kondisi sinyal telepon selulernya cenderung lemah. Sementara itu, untuk sinyal internet telepon seluler dari 10 desa di Kecamatan Panyipatan, 9 desa sinyal internetnya sudah 5G/4G/LTE, sedangkan 1 desa masih 3G/H/H+/EVDO yaitu Desa Kuringkit.

https://tanahlautkab.bps.go.id

## 6.1 PARIWISATA

**Tabel 6.1.1 Jumlah Sarana Akomodasi Menurut Desa/Kelurahan dan Jenis Akomodasi di Kecamatan Panyipatan, 2023**

| Desa/Kelurahan | Hotel | Penginapan |
|---|---|---|
| (1) | (2) | (3) |
| Batakan | – | 38 |
| Tanjung Dewa | – | – |
| Kandangan Lama | – | – |
| Batu Tungku | – | – |
| Kuringkit | – | – |
| Bumi Asih | – | – |
| Batu Mulya | – | – |
| Suka Ramah | – | – |
| Panyipatan | – | – |
| Kandangan Baru | – | – |
| **Panyipatan** | **–** | **38** |

Sumber: Kantor Desa

https://tanahlautkab.bps.go.id

## 6.2 TRANSPORTASI

**Tabel 6.2.1 Prasarana dan Sarana Transportasi Antar Desa/Kelurahan Menurut Desa/Kelurahan di Kecamatan Panyipatan, 2023**

| Desa/Kelurahan | Jenis Prasarana Transportasi | Keberadaan Angkutan Umum |
|---|---|---|
| (1) | (2) | (3) |
| Batakan | Darat | Ada, dengan trayek tetap |
| Tanjung Dewa | Darat | Ada, dengan trayek tetap |
| Kandangan Lama | Darat | Ada, dengan trayek tetap |
| Batu Tungku | Darat | Ada, dengan trayek tetap |
| Kuringkit | Darat | Ada, dengan trayek tetap |
| Bumi Asih | Darat | Ada, tanpa trayek tetap |
| Batu Mulya | Darat | Tidak ada angkutan umum |
| Suka Ramah | Darat | Tidak ada angkutan umum |
| Panyipatan | Darat | Ada, dengan trayek tetap |
| Kandangan Baru | Darat | Ada, dengan trayek tetap |

https://tanahbutkab.bps.go.id

Lanjutan Tabel 6.2.1

| Desa/Kelurahan | Jenis Permukaan Jalan Darat Terluas | Dapat Dilalui Kendaraan Bermotor Roda 4 atau Lebih |
|---|---|---|
| (1) | (4) | (5) |
| Batakan | Aspal/beton | Sepanjang tahun |
| Tanjung Dewa | Aspal/beton | Sepanjang tahun |
| Kandangan Lama | Aspal/beton | Sepanjang tahun |
| Batu Tungku | Aspal/beton | Sepanjang tahun |
| Kuringkit | Aspal/beton | Sepanjang tahun |
| Bumi Asih | Aspal/beton | Sepanjang tahun |
| Batu Mulya | Aspal/beton | Sepanjang tahun |
| Suka Ramah | Aspal/beton | Sepanjang tahun |
| Panyipatan | Aspal/beton | Sepanjang tahun |
| Kandangan Baru | Aspal/beton | Sepanjang tahun |

Sumber: Kantor Desa

https://tanahbumbukab.bps.go.id

**Tabel 6.2.2 Banyaknya Kendaraan Bermotor di Kecamatan Panyipatan, 2021–2023**

| Jenis Kendaraan Bermotor | 2021 | 2022 | 2023 |
|---|---|---|---|
| (1) | (2) | (3) | (4) |
| Mobil Penumpang | 335 | 413 | 459 |
| Bus | – | 4 | 2 |
| Truk | 56 | 64 | 67 |
| Sepeda Motor | 2.929 | 5.899 | 6.420 |

Sumber: Badan Keuangan Daerah Unit Pelayanan Pendapatan Daerah

https://tanahlautkab.bps.go.id

## 6.3 KOMUNIKASI

**Tabel 6.3.1 Keberadaan Kantor Pos/Pos Pembantu/Rumah Pos, Pos Keliling, dan Perusahaan/Agen Jasa Ekspedisi Swasta Menurut Desa/Kelurahan di Kecamatan Panyipatan, 2023**

| Desa/Kelurahan | Kantor Pos/Pos Pembantu/Rumah Pos | Pos Keliling | Perusahaan/Agen Jasa Ekspedisi Swasta |
|---|---|---|---|
| (1) | (2) | (3) | (4) |
| Batakan | Tidak ada | Ada | Tidak ada |
| Tanjung Dewa | Tidak ada | Ada | Tidak ada |
| Kandangan Lama | Tidak ada | Ada | Tidak ada |
| Batu Tungku | Tidak ada | Ada | Tidak ada |
| Kuringkit | Tidak ada | Ada | Tidak ada |
| Bumi Asih | Tidak ada | Ada | Tidak ada |
| Batu Mulya | Beroperasi | Ada | Tidak ada |
| Suka Ramah | Tidak ada | Ada | Tidak ada |
| Panyipatan | Tidak ada | Ada | Tidak ada |
| Kandangan Baru | Tidak ada | Tidak ada | Tidak ada |

Sumber: Kantor Desa

https://tanahlautkab.bps.go.id

**Tabel 6.3.2** **Jumlah Menara Telepon Seluler dan Operator Layanan Komunikasi Telepon Seluler Menurut Desa/Kelurahan di Kecamatan Panyipatan, 2023**

| Desa/Kelurahan | Jumlah Menara Telepon seluler | Jumlah Operator Layanan Komunikasi Telepon Seluler |
|---|---|---|
| (1) | (2) | (3) |
| Batakan | 1 | 3 |
| Tanjung Dewa | 2 | 3 |
| Kandangan Lama | 1 | 2 |
| Batu Tungku | 1 | 2 |
| Kuringkit | – | 5 |
| Bumi Asih | 1 | 4 |
| Batu Mulya | 2 | 4 |
| Suka Ramah | 2 | 3 |
| Panyipatan | 2 | 3 |
| Kandangan Baru | – | 3 |
| **Panyipatan** | **12** | **32** |

Sumber: Kantor Desa

https://tanahlautkab.bps.go.id

**Tabel 6.3.3 Kekuatan Sinyal Telepon Seluler dan Jenis Sinyal Internet Telepon Seluler Menurut Desa/Kelurahan di Kecamatan Panyipatan, 2023**

| Desa/Kelurahan | Kekuatan Sinyal Telepon Seluler | Jenis Sinyal Internet Telepon Seluler |
|---|---|---|
| (1) | (2) | (3) |
| Batakan | Sangat kuat | 5G/4G/LTE |
| Tanjung Dewa | Kuat | 5G/4G/LTE |
| Kandangan Lama | Kuat | 5G/4G/LTE |
| Batu Tungku | Lemah | 5G/4G/LTE |
| Kuringkit | Lemah | 3G/H/H+/EVDO |
| Bumi Asih | Kuat | 5G/4G/LTE |
| Batu Mulya | Sangat kuat | 5G/4G/LTE |
| Suka Ramah | Kuat | 5G/4G/LTE |
| Panyipatan | Kuat | 5G/4G/LTE |
| Kandangan Baru | Lemah | 5G/4G/LTE |

Sumber: Kantor Desa

https://tanahbumbukab.bps.go.id

# BAB 7
# PERBANKAN, KOPERASI, DAN PERDAGANGAN

https://tanahlautkab.bps.go.id

## PENJELASAN TEKNIS

1. Pada Undang-undang Nomor 10 Tahun 1998 tentang Perbankan, Bank disebutkan sebagai badan usaha yang menghimpun dana dari masyarakat dalam bentuk simpanan dan menyalurkannya kepada masyarakat dalam bentuk kredit dan atau bentukbentuk lainnya dalam rangka meningkatkan taraf hidup Masyarakat.

2. Bank Umum adalah bank yang melaksanakan kegiatan usaha secara konvensional dan atau berdasarkan prinsip syariah, yang dalam kegiatannya memberikan jasa dalam lalu lintas pembayaran.

- Bank umum pemerintah meliputi Bank Rakyat Indonesia (BRI), Bank Negara Indonesia (BNI), Bank Mandiri, Bank Pembangunan Daerah (BPD), Bank Tabungan Negara (BTN), dan Teras BRI.
- Bank umum swasta, meliputi Bank Permata, Bank Syariah Indonesia (BSI), Bank Central Asia (BCA), Bank Mutiara, Rabo Bank, Bank Sinarmas, dsb.

3. Bank Perkreditan Rakyat (BPR) adalah bank yang menerima simpanan dalam bentuk deposito berjangka, tabungan, atau bentuk lain yang disamakan dengan itu, manyalurkan dana dalam bentuk kredit kepada masyarakat yang membutuhkan. Koperasi adalah salah satu bentuk lembaga profit sosial yang bertujuan untuk meningkatkan kesejahteraan anggotanya melalui berbagai bentuk usaha.

4. Koperasi Unit Desa adalah suatu Koperasi serba usaha yang beranggotakan penduduk desa dan berlokasi di daerah pedesaan, daerah kerjanya biasanya mencakup satu wilayah kecamatan. Pembentukan KUD ini merupakan penyatuan dari beberapa Koperasi pertanian yang kecil dan banyak jumlahnya di pedesaan. Koperasi Unit Desa (KUD) adalah suatu organisasi ekonomi yang bersifat sosial merupakan wadah bagi pengembangan berbagai kegiatan ekonomi masyarakat perdesaan yang diselenggarakan oleh dan untuk masyarakat itu sendiri.

5. Koperasi Industri Kecil dan Kerajinan Rakyat (Kopinkra) merupakan koperasi yang beranggotakan industri-industri kecil dan kerajinan rakyat yang ada di wilayah desa/kelurahan.

6. Koperasi Simpan Pinjam (Kospin) adalah koperasi yang bergerak di bidang simpanan dan pinjaman.

https://nasbahpublik.bps.go.id

7. Koperasi lainnya, seperti koperasi serbaguna dan koperasi konsumsi

8. Kelompok pertokoan adalah sejumlah toko yang terdiri dari minimal 10 toko dan mengelompok dalam satu lokasi. Dalam satu kelompok pertokoan, jumlah bangunan fisiknya dapat lebih dari satu. Tidak termasuk ke dalam kelompok pertokoan untuk sejumlah toko yang ada di dalam mall dan pusat perbelanjaan lainnya.

9. Pasar adalah tempat pertemuan antara penjual dan pembeli barang dan jasa. Pasar dapat menggunakan bangunan yang bersifat permanen atau semi permanen ataupun tanpa bangunan. Barang yang diperjualbelikan di dalam pasar dapat terdiri dari banyak komoditas (campuran) ataupun secara khusus suatu komoditas tertentu. Menurut Peraturan Presiden (Perpres) Nomor 112 Tahun 2007 tentang Penataan dan Pembinaan Pasar Tradisional, pasar adalah area tempat jual beli barang dengan jumlah penjual lebih dari satu baik yang disebut sebagai pusat perbelanjaan, pasar tradisional, pertokoan, mall, plasa, pusat perdagangan maupun sebutan lainnya.
   Banyaknya pasar yang dicatat mengacu pada lokasi dan kegiatan. Jika dua atau lebih pasar yang bangunannya berada di lokasi yang saling berdekatan maka dianggap terletak pada lokasi yang berbeda jika pasar-pasar tersebut pengelolanya berbeda. Jika pasar hanya aktif pada hari-hari tertentu saja tetap dicatat sebagai pasar.

10. Pasar dengan bangunan permanen adalah pasar pada bangunan tetap yang memiliki lantai, atap, dan dinding permanen.

11. Pasar dengan bangunan semi permanen adalah pasar pada bangunan tetap yang memiliki lantai dan atap, tetapi tanpa dinding. Bangunan pada pasar tradisional yang mencakup bangunan permanen dan semi permanen dikategorikan sebagai pasar dengan bangunan permanen.

12. Pasar tanpa bangunan adalah pasar yang tidak berada dalam bangunan.

13. Minimarket/swalayan adalah sistem pelayanan mandiri, menjual berbagai jenis barang secara eceran, dan semua barang memiliki label harga, dengan luas bangunan kurang dari 400 $m^2$. Yang dicatat adalah minimarket yang masih aktif.

14. Supermarket, atau dengan sebutan lain adalah tempat perdagangan dengan sistem pelayanan mandiri, semua barang memiliki label harga, dan

https://kaimonotan.bps.go.id

luas minimal 400 $m^2$. Jika dalam 1 bangunan terdiri dari beberapa unit usaha tersebut, maka tetap dihitung sebagai satu kesatuan sarana ekonomi.

15. Restoran adalah suatu jenis usaha yang mempergunakan seluruh bangunan secara permanen untuk menyediakan jasa pangan yang pengolahan dan penyajiannya secara langsung di tempat sesuai dengan keinginan para pengguna jasa yang mempunyai ciri pembeli biasanya dikenakan pajak. Izin restoran dan kualifikasinya diberikan oleh Ditjen Pariwisata/Kanwil Parpostel setempat.

16. Rumah makan adalah jenis usaha yang menyediakan jasa pangan yang pengolahan makanannya dapat dilakukan diluar rumah makan, yang mempunyai ciri pembeli biasanya dikenakan pajak. Izin rumah makan diberikan oleh Diparda (pada kabupaten/kota). Di wilayah yang terdapat Dinas Pariwisata, biasanya pemberian izin ditangani oleh Direktorat Perekonomian/Bagian Perekonomian Pemda setempat.

17. Warung/kedai makanan minuman adalah usaha yang menjual makanan dan minuman siap saji yang dijual di bangunan yang tetap dan tidak mempunyai surat izin usaha. Ciri utama dari warung/kedai makanan minuman adalah pembeli biasanya tidak dikenakan pajak.

https://kemdikbud.go.id

https://tanahlautkab.bps.go.id

## ULASAN

Sarana lembaga keuangan di Kecamatan Panyipatan tahun 2023 terdapat 1 Bank Umum Pemerintah yang berada di Desa Batu Mulya. Di Kecamatan Panyipatan terdapat 8 Koperasi Industri Kecil dan Kerajinan Rakyat (Kopinkra) yang berada di Desa Suka Ramah. Sarana perdagangan di Kecamatan Panyipatan yaitu 1 pasar bangunan permanen, 3 pasar dengan bangunan semi permanen, dan 3 pasar tanpa bangunan.

https://tanahlautkab.bps.go.id

**Tabel 7.1** **Banyaknya Sarana Lembaga Keuangan Bank Menurut Desa/Kelurahan dan Jenis Bank di Kecamatan Panyipatan, 2023**

| Desa/Kelurahan | Bank Umum Pemerintah | Bank Umum Swasta | Bank Perkreditan Rakyat (BPR) |
|---|---|---|---|
| (1) | (2) | (3) | (4) |
| Batakan | – | – | – |
| Tanjung Dewa | – | – | – |
| Kandangan Lama | – | – | – |
| Batu Tungku | – | – | – |
| Kuringkit | – | – | – |
| Bumi Asih | – | – | – |
| Batu Mulya | 1 | – | – |
| Suka Ramah | – | – | – |
| Panyipatan | – | – | – |
| Kandangan Baru | – | – | – |
| **Panyipatan** | **1** | **–** | **–** |

Sumber: Kantor Desa

https://tanahlautkab.bps.go.id

**Tabel 7.2** **Banyaknya Koperasi Aktif Menurut Menurut Desa/ Kelurahan dan Jenis Koperasi di Kecamatan Panyipatan, 2023**

| Desa/Kelurahan | Koperasi Unit Desa (KUD) | Koperasi Industri Kecil dan Kerajinan Rakyat (Kopinkra) |
|---|---|---|
| (1) | (2) | (3) |
| Batakan | – | – |
| Tanjung Dewa | – | – |
| Kandangan Lama | – | – |
| Batu Tungku | – | – |
| Kuringkit | – | – |
| Bumi Asih | – | – |
| Batu Mulya | – | – |
| Suka Ramah | – | 8 |
| Panyipatan | – | – |
| Kandangan Baru | – | – |
| **Panyipatan** | **–** | **8** |

https://tanahlautkab.bps.go.id

Lanjutan Tabel 7.2

| Desa/Kelurahan | Koperasi Simpan Pinjam (Kospin) | Koperasi Lainnya |
|---|---|---|
| (1) | (4) | (5) |
| Batakan | – | – |
| Tanjung Dewa | – | – |
| Kandangan Lama | – | – |
| Batu Tungku | – | – |
| Kuringkit | – | – |
| Bumi Asih | – | – |
| Batu Mulya | – | – |
| Suka Ramah | – | – |
| Panyipatan | – | – |
| Kandangan Baru | – | – |
| **Panyipatan** | **–** | **–** |

Sumber: Kantor Desa

https://tanahlautkab.bps.go.id

**Tabel 7.3** **Banyaknya Sarana Perdagangan Menurut Desa/Kelurahan dan Jenis Sarana Perdagangan di Kecamatan Panyipatan, 2023**

| Desa/Kelurahan | Kelompok Pertokoan | Pasar dengan Bangunan Permanen | Pasar dengan Bangunan Semi Permanen |
|---|---|---|---|
| (1) | (2) | (3) | (4) |
| Batakan | – | – | 1 |
| Tanjung Dewa | – | – | 1 |
| Kandangan Lama | – | – | 1 |
| Batu Tungku | – | – | – |
| Kuringkit | – | – | – |
| Bumi Asih | – | – | – |
| Batu Mulya | – | 1 | – |
| Suka Ramah | – | – | – |
| Panyipatan | – | – | – |
| Kandangan Baru | – | – | – |
| **Panyipatan** | **–** | **1** | **3** |

https://tanahlautkab.bps.go.id

Lanjutan Tabel 7.3

| Desa/Kelurahan | Pasar tanpa Bangunan | Mini Market/ Swalayan/ Supermarket | Restoran/ Rumah Makan |
|---|---|---|---|
| (1) | (5) | (6) | (7) |
| Batakan | – | – | – |
| Tanjung Dewa | – | – | – |
| Kandangan Lama | 1 | – | – |
| Batu Tungku | 1 | – | – |
| Kuringkit | – | – | – |
| Bumi Asih | – | – | – |
| Batu Mulya | – | – | – |
| Suka Ramah | – | – | – |
| Panyipatan | 1 | – | – |
| Kandangan Baru | – | – | – |
| **Panyipatan** | **3** | **–** | **–** |

Sumber: Kantor Desa

https://tanahlautkab.bps.go.id

# DAFTAR PUSTAKA


Badan Ketahanan Pangan. 2018. *Neraca Bahan Makanan Indonesia 2018–2021*. Jakarta: Badan Ketahanan Pangan.

Badan Pusat Statistik. 2021. *Buku 3: Konsep dan Definisi Podes 2021*. Jakarta: Badan Pusat Statistik.

Badan Pusat Statistik. 2021. *Pedoman Pengumpulan Data Statistik Perikanan*. Jakarta: Badan Pusat Statistik.

Badan Pusat Statistik. 2022. *Buku 4 Konsep dan Definisi Survei Sosial Ekonomi Nasional Maret 2023*. Jakarta: Badan Pusat Statistik.

Badan Pusat Statistik. 2023. Statistik Kriminal 2023. Jakarta: Badan Pusat Statistik.

Badan Pusat Statistik. 2024. *Pedoman SEDAPP Online: Sedia Data Perusahaan Perkebunan dengan Aplikasi SKB-Online*. Jakarta: Badan Pusat Statistik.

Indonesia. Peraturan Kepala Badan Pusat Statistik Nomor 120 Tahun 2020 Tentang Klasifikasi Desa Perkotaan dan Perdesaan di Indonesia 2020. Badan Pusat Statistik. Jakarta.

Kementerian Dalam Negeri. 2019. *Peraturan Menteri Dalam Negeri Nomor 72 Tahun 2019 tentang Perubahan Atas Peraturan Menteri Dalam Negeri Nomor 137 Tahun 2017 Tentang Kode Dan Data Wilayah Administrasi Pemerintahan*. Jakarta.

Kementerian Dalam Negeri. 2022. *Keputusan Menteri Dalam Negeri Nomor 100.1.1-6117 tentang Pemberian dan Pemutakhiran Kode, Data Wilayah Administrasi Pemerintahan, dan Pulau Tahun 2022*. Jakarta.

Kementerian Pertanian, Direktorat Jenderal Hortikultura & Badan Pusat Statistik. 2022. *Pedoman Statistik Pertanian Hortikultura (SPH)*. Jakarta: Direktorat Jenderal Hortikultura, Kementerian Pertanian.

Kementerian Pertanian Republik Indonesia. 2023. *Statistik Peternakan dan Kesehatan Hewan 2023*. Jakarta: Kementerian Pertanian Republik Indonesia.

Keputusan Direktur Jenderal Peternakan dan Kesehatan Hewan No. 14087/ KPTS/ OT.040/F/11/2019 tentang Petunjuk Teknis Pengumpulan, Pengolahan, dan Penyajian Data Pokok Peternakan dan Kesehatan Hewan.

Keputusan Kepala Badan Pusat Statistik Nomor 6 Tahun 2022 tentang Penyelenggaraan Statistik Dasar.

Larasati, Widya. 2023. *Ringkasan Eksekutif Pengeluaran dan Konsumsi Penduduk Indonesia Maret 2023*. Volume 15 Nomor 2. Jakarta: Badan Pusat Statistik.

Peraturan Kepala Badan Nasional Penanggulangan Bencana Nomor 7 Tahun 2023 tentang Petunjuk Pelaksanaan Standar Data Kejadian dan Dampak Bencana.

Peraturan Menteri Dalam Negeri Nomor 72 Tahun 2019 tentang Perubahan Atas Peraturan Menteri Dalam Negeri Nomor 137 Tahun 2017 tentang Kode dan Data Wilayah


https://perpustakaan.bps.go.id

Administrasi Pemerintahan.

Peraturan Menteri Kesehatan RI Nomor 1332 Tahun 2002 tentang Perubahan Atas Peraturan Menteri Kesehatan RI Nomor 922/MENKES/PER/X/1993 tentang Ketentuan dan Tata Cara Pemberian Izin Apotek. Peraturan Menteri Kesehatan Republik Insonesia Nomor 75 Tahun 2014 tentang Pusat Kesehatan Masyarakat.

Undang-Undang Nomor 24 Tahun 2013 tentang Perubahan atas Undang-Undang Nomor 23 Tahun 2006 tentang Administrasi Kependudukan.

Undang-Undang Republik Indonesia Nomor 44 Tahun 2009 tentang Rumah Sakit.

Undang-Undang Republik Indonesia Nomor 6 Tahun 2014 tentang Desa.

https://tanahlautkab.bps.go.id

https://tanahlautkab.bps.go.id

ST2023
SENSUS PERTANIAN

BerAKHLAK
Berorientasi Pelayanan Akuntabel Kompeten Harmonis Loyal Adaptif Kolaboratif

#bangga melayani bangsa

# DATA
MENCERDASKAN BANGSA

https://tanahlautkab.bps.go.id

**BADAN PUSAT STATISTIK**
**KABUPATEN TANAH LAUT**

Jl. A. Syairani No. 9 Komplek Perkantoran Gagas, Pelaihari 70814
Telp.: (0512) 21092 Fax.: (0512) 21213
Homapage: http://www.tanahlautkab.bps.go.id
Email:bps6301@bps.go.id

ISSN 2745-8202
9 772745 820007