KATALOG : 1102001.6302190

KECAMATAN SAMPANAHAN DALAM ANGKA

2024

https://kotabarukab.bps.go.id

BADAN PUSAT STATISTIK
KABUPATEN KOTABARU

https://kotabarukab.bps.go.id

KATALOG : 1102001.6302190

https://kotabarukab.bps.go.id

KECAMATAN **SAMPANAHAN** DALAM ANGKA

2024

BADAN PUSAT STATISTIK
KABUPATEN KOTABARU

KECAMATAN SAMPANAHAN DALAM ANGKA
2024
Volume XVII, 2024

Katalog: 1102001.6302190
ISSN: 2746-7341
Nomor Publikasi: 63020.24030

Ukuran Buku: 14,8 cm x 21 cm
Jumlah Halaman: xxii + 44 hal

Penyusun Naskah:
BPS Kabupaten Kotabaru

Penyunting:
BPS Kabupaten Kotabaru

Pembuat Kover:
BPS Kabupaten Kotabaru

Penerbit:
©BPS Kabupaten Kotabaru

Sumber Ilustrasi: ...

Dilarang mereproduksi dan/atau menggandakan sebagian atau seluruh isi
buku ini untuk tujuan komersial tanpa izin tertulis dari Badan Pusat Statistik Kabupaten Kotabaru.

https://kotabarukab.bps.go.id

ISSN 2746-7341

TIM PENYUSUN

KECAMATAN SAMPANAHAN DALAM ANGKA 2024

Volume XVII, 2024

Pengarah
Widhi Pranowo

Penanggung Jawab
Widhi Pranowo

Penyunting
Kharisma Ayu Pradani

Pengolah Data dan Penulis Naskah
Pandhu Piwulang
Kharisma Ayu Pradani

Penata Letak
Pandhu Piwulang
Kharisma Ayu Pradani

https://kotasukabumkab.bps.go.id

https://kotabarukab.bps.go.id

KONTRIBUTOR DATA

1. Kementerian Agama
2. Kementerian Pendidikan dan Kebudayaan
3. Badan Pusat Statistik
4. Sekretariat Daerah Kabupaten Kotabaru
5. Dinas Kependudukan dan Pencatatan Sipil

https://kotabarukab.bps.go.id

https://kotabarukab.bps.go.id

PETA WILAYAH KECAMATAN SAMPANAHAN

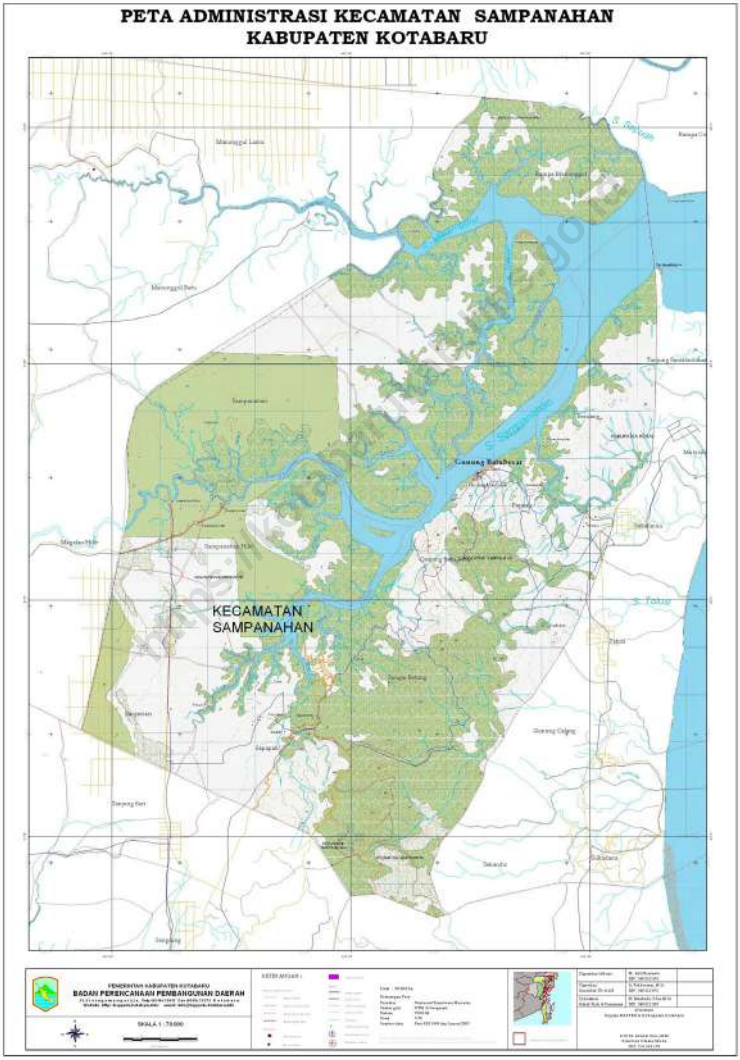

https://kotabarukab.bps.go.id

KEPALA BPS KABUPATEN KOTABARU

Widhi Pranowo

https://kotabaru.bps.go.id

https://kotabarukab.bps.go.id

KATA PENGANTAR

Dalam upaya yang kesekian kalinya ini, kami mempersembahkan kembali suatu publikasi yang berisikan data-data statistik yang menggambarkan suatu kecamatan yaitu "KECAMATAN SAMPANAHAN DALAM ANGKA TAHUN 2024".

Kami sangat berterima kasih kepada bapak/ibu camat beserta jajarannya yang telah sudi memberikan dukungannya, baik secara moril ataupun materil dan sambutan yang sangat baik atas terbitnya publikasi ini. Tak lupa pula kami ucapkan terima kasih kepada semua Kepala Dinas/Instansi Jawatan Kecamatan dan Kepala Desa yang telah memberikan bantuannya berupa data-data statistik yang diperlukan.

Kami menyadari, publikasi ini masih jauh dari kesempurnaan. Oleh karena itu, kami mengharap semua pihak untuk membantu mewujudkan kesempurnaan itu dengan memberikan saran dan kritik yang positif. Akhirnya, dengan terbitnya publikasi ini semoga mampu memberikan manfaat sesuai dengan keperluannya.

https://kotabarukab.bps.go.id

Kotabaru, September 2024
Kepala BPS
Kabupaten Kotabaru

Widhi Pranowo

ISSN 2746-7341

DAFTAR ISI

KECAMATAN SAMPANAHAN DALAM ANGKA
2024
Volume XVII, 2024

Halaman

Kata Pengantar xi
Daftar Isi xii
Daftar Tabel xiii
Daftar Gambar xvii
Penjelasan Umum xix
Daftar Singkatan xxi
1. Geografi 1
2. Pemerintahan 9
3. Penduduk 13
4. Sosial dan Kesejahteraan Rakyat 19
5. Pertanian 33
Daftar Pustaka 43

https://rotabarukab.bps.go.id

DAFTAR TABEL

Tabel Halaman

1. GEOGRAFI

1.1 Luas Daerah Menurut Desa/Kelurahan di Kecamatan Sampanahan, 2023 6

1.2 Jarak ke Ibukota Kecamatan dan Ibukota Kabupaten Menurut Desa/Kelurahan di Kecamatan Sampanahan (km), 2023 7

2. PEMERINTAHAN

2.1 Jumlah Rukun Warga (RW)/Dusun dan Rukun Tetangga (RT) Menurut Desa/Kelurahan di Kecamatan Sampanahan, 2023 12

3. PENDUDUK

3.1 Penduduk, Distribusi Persentase Penduduk, Kepadatan Penduduk, Rasio Jenis Kelamin Penduduk Menurut Desa/ Kelurahan di Kecamatan Sampanahan, 2023 17

4. SOSIAL DAN KESEJAHTERAAN RAKYAT

4.1 PENDIDIKAN

4.1.1 Banyaknya Desa/Kelurahan yang Memiliki Fasilitas Sekolah Menurut Tingkat Pendidikan di Kecamatan Sampanahan, 2021-2023 22

4.1.2 Jumlah Sekolah Menurut Tingkat Pendidikan di Kecamatan Sampanahan, 2022/2023 dan 2023/2024 23

4.1.3 Jumlah Guru Menurut Tingkat Pendidikan di Kecamatan Sampanahan, 2022/2023 dan 2023/2024 24

4.1.4 Jumlah Murid Menurut Tingkat Pendidikan di Kecamatan Sampanahan, 2022/2023 dan 2023/2024 25

https://kotabarukab.bps.go.id

Tabel Halaman

4.2 KESEHATAN

4.2.1 Banyaknya Desa/Kelurahan yang Memiliki Sarana Kesehatan Menurut Jenis Sarana Kesehatan di Kecamatan Sampanahan, 2021-2023 26

4.3 PERUMAHAN DAN LINGKUNGAN

4.3.1 Banyaknya Desa/Kelurahan Menurut Sumber Air Minum Sebagian Besar Keluarga di Kecamatan Sampanahan, 2021-2023 .. 27

4.3.2 Banyaknya Desa/Kelurahan Menurut Sumber Penerangan Jalan Utama di Kecamatan Sampanahan, 2021-2023 28

4.3.3 Banyaknya Desa/Kelurahan Menurut Penggunaan Fasilitas Tempat Buang Air Besar Sebagian Besar Keluarga di Kecamatan Sampanahan, 2021-2023 29

4.4 AGAMA DAN SOSIAL LAINNYA

4.4.1 Jumlah Tempat Peribadatan Menurut Desa/Kelurahan di Kecamatan Sampanahan, 2023 30

4.4.2 Jumlah Penduduk Menurut Desa/Kelurahan dan Agama yang Dianut di Kecamatan Sampanahan, 2023 31

5. PERTANIAN

5.1 Luas Panen Tanaman Sayuran dan Buah-buahan Semusim Menurut Jenis Tanaman di Kecamatan Sampanahan (ha), 2020–2023 36

5.2 Produksi Tanaman Sayuran dan Buah-buahan Semusim Menurut Jenis Tanaman di Kecamatan Sampanahan (kuintal), 2020–2023 37

5.3 Luas Panen Tanaman Biofarmaka Menurut Jenis Tanaman di Kecamatan Sampanahan (m^2), 2020–2023 38

5.4 Produksi Tanaman Biofarmaka Menurut Jenis Tanaman di Kecamatan Sampanahan (kg), 2020–2023 39

5.5 Luas Panen Tanaman Hias Menurut Jenis Tanaman di Kecamatan Sampanahan (m^2), 2020–2023 40

https://kotaparukabps.id

Tabel Halaman

5.6 Produksi Tanaman Hias Menurut Jenis Tanaman di Kecamatan Sampanahan (tangkai), 2020–2023 41
5.7 Produksi Buah-Buahan dan Sayuran Tahunan Menurut Jenis Tanaman di Kecamatan Sampanahan (kuintal), 2020–2023 42

https://kotabarukab.bps.go.id

https://kotabarukab.bps.go.id

DAFTAR GAMBAR

Gambar Halaman

1.1 Luas Daerah Menurut Desa/Kelurahan (%), 2023..... 4

1.2 Jarak ke Ibukota Kecamatan Menurut Desa/Kelurahan di Kecamatan Sampanahan, 2023..... 5

3.1 Jumlah Penduduk Menurut Desa/Kelurahan di Kecamatan Sampanahan, 2023..... 16

https://kotabarukab.bps.go.id

https://kotabarukab.bps.go.id

PENJELASAN UMUM

Tanda-tanda, satuan-satuan, dan lain-lainnya yang digunakan dalam publikasi ini adalah sebagai berikut:

1. TANDA-TANDA

Data tidak tersedia	:	...
Tidak ada atau nol	:	–
Data dapat diabaikan	:	~0
Tanda decimal	:	,
Data tidak dapat ditampilkan	:	NA
Angka estimasi	:	e
Angka diperbaiki	:	r
Angka sementara	:	*
Angka sangat sementara	:	**
Angka sangat sangat sementara	:	***

2. SATUAN

barel	:	158,99 liter/*litres* = 1/6,2898 m^3
hektare (ha)	:	10.000 m^2
kilometer (km)	:	1.000 meter
knot	:	1,8523 km/jam
kuintal	:	100 kg
KWh	:	1.000 Watt *hour*
MWh	:	1.000 KWh
liter (untuk beras)/	:	0,80 kg
MMSCF	:	1/35,3 m^3
metrik ton (m.ton)	:	0,98421 long ton = 1.000 kg
ons	:	28,31 gram
ton	:	1.000 kg

Satuan lain: buah, dus, butir, helai/lembar, kaleng, batang, pulsa, ton kilometer (ton-km), jam, menit, persen (%).

Perbedaan angka di belakang koma disebabkan oleh pembulatan angka.

https://rotabanukab.bps.go.id

https://kotabarukab.bps.go.id

DAFTAR SINGKATAN

SI	:	Stasiun Iklim
SMPK	:	Stasiun Meterologi Pertanian Khusus
t.t	:	Tempat tidur
BCG	:	Bacillus Calmette Guerin
DPT	:	Difteri, Pertusis, Tetanus
TT	:	Tetanus Toxoid
IOT	:	Industri Obat Tradisional
IKOT	:	Industri Kecil Obat Tradisional
Alkes	:	Alat kesehatan
PKRT	:	Perbekalan Kesehatan Rumah tangga
Kompl	:	Komplemen
IRTP	:	Industri Pangan Produksi Rumah Tangga
PBF	:	Pedagang Besar Farmasi
GFK	:	Gudang Farmasi Kab/Kota
RB	:	Rumah Bersalin
Pustu	:	Puskesmas pembantu
BP	:	Balai Pengobatan
TPS	:	Tempat Pembuangan Sampah Sementara
Jamkesmas	:	Jaminan kesehatan masyarakat miskin
PJKMU	:	Program Jaminan Kesehatan Masyarakat Umum
SIUP	:	Surat Ijin Usaha Perdagangan
TDP	:	Tanda Daftar Perusahaan
API	:	Angka Pengenal Importir

https://kotabarukab.bps.go.id

https://kotabarukab.bps.go.id

BAB I
GEOGRAFI

/ge.o.gra.fi/

letak suatu daerah dilihat dari kenyataannya di bumi atau posisi daerah itu pada bola bumi dibandingkan dengan posisi daerah lain.

https://kotabarukab.bps.go.id

#GEOGRAPHY

https://kotabarukab.bps.go.id

ULASAN

Kecamatan Sampanahan merupakan salah satu kecamatan yang ada di Kabupaten Kotabaru. Kecamatan Sampanahan terletak antara garis 115050'11"-116006'57" bujur timur dan 002042'16" - 003006'08" lintang selatan. Sebelah barat Kecamatan Sampanahan berbatasan dengan Kecamatan Kelumpang Hulu dan Kecamatan Kelumpang Selatan, sebelah timur berbatasan dengan Kecamatan Kelumpang Utara dan Selat Malaka, sebelah selatan berbatasan dengan Kecamatan Kelumpang Selatan dan Selat Malaka, sementara sebelah utara dibatasi oleh Kecamatan Kelumpang Barat dan Kecamatan Kelumpang Utara.

Secara administratif, terdapat 10 desa di Kecamatan Sampanahan dengan Desa Gunung Batu Besar sebagai ibukota kecamatan. Luas wilayah Kecamatan Sampanahan sebesar 404,80 km2.

https://kotabarukab.bps.go.id

Gambar 1.1 Luas Daerah menurut Desa/Kelurahan (%), 2023

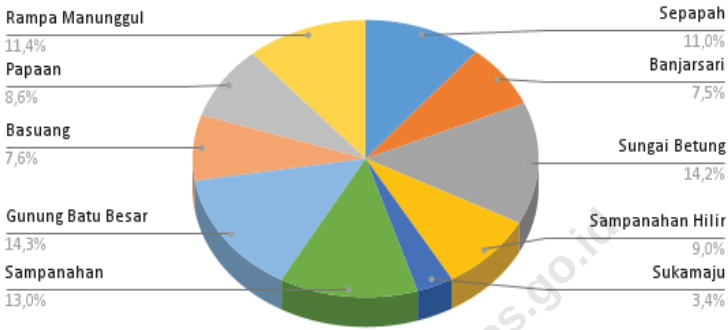

Sumber : Sekretariat Daerah Kabupaten Kotabaru

https://kotabarukab.bps.go.id

Gambar 1.2 Jarak ke Ibukota Kecamatan Menurut Desa/Kelurahan di Kecamatan Sampanahan (km), 2023

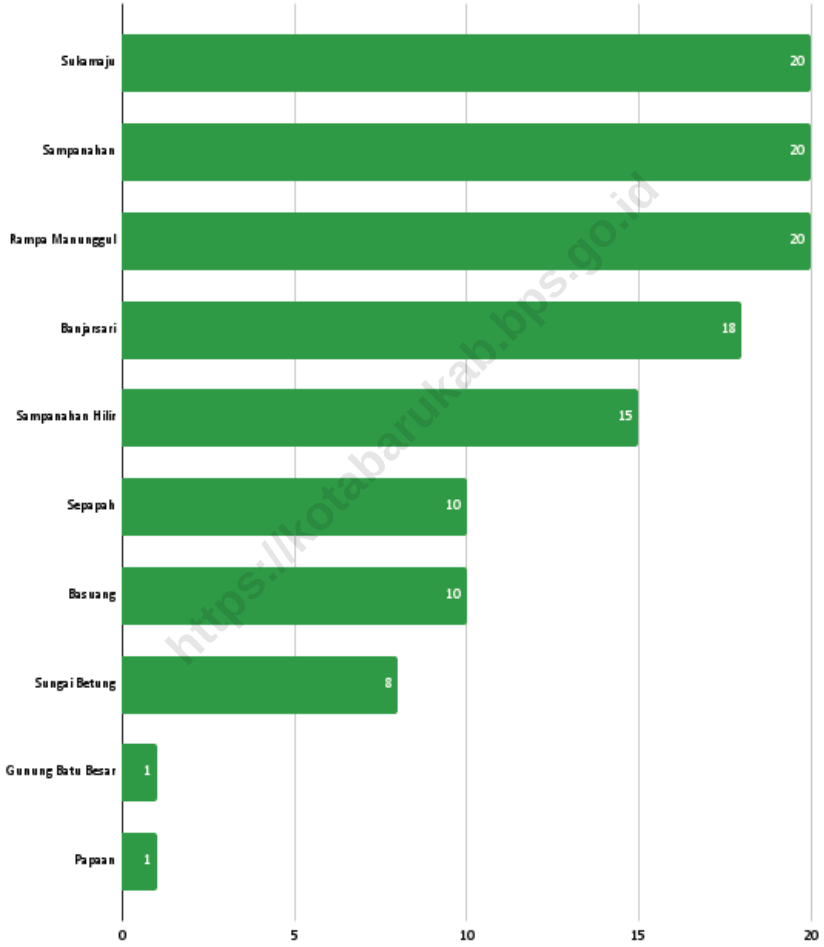

https://kotabarukab.bps.go.id

Sumber: Badan Pusat Statistik, Pendataan Potensi Desa (PODES), 2021

Tabel 1.1 Luas Daerah Menurut Desa/Kelurahan di Kecamatan Sampanahan, 2023

Desa/Kelurahan	Luas (km^2)	Persentase terhadap Luas Kecamatan
(1)	(2)	(3)
Sepapah	44,62	11,02
Banjarsari	30,19	7,46
Sungai Betung	57,44	14,19
Sampanahan Hilir	36,57	9,03
Sukamaju	13,91	3,44
Sampanahan	52,44	12,96
Gunung Batu Besar	58,07	14,35
Basuang	30,87	7,63
Papaan	34,73	8,58
Rampa Manunggul	45,96	11,35
Kecamatan Sampanahan	**404,80**	**100,00**

Catatan: ...
Sumber: Sekretariat Daerah Kabupaten Kotabaru

https://kotabarukab.bps.go.id

Tabel 1.2 Jarak ke Ibukota Kecamatan dan Ibukota Kabupaten/Kota Menurut Desa/Kelurahan di Kecamatan Sampanahan (km), 2023

Desa/Kelurahan	Jarak ke Ibukota Kecamatan	Jarak ke Ibukota Kabupaten/ Kota
(1)	(2)	(3)
Sepapah	10	100
Banjarsari	18	60
Sungai Betung	8	128
Sampanahan Hilir	15	298
Sukamaju	20	185
Sampanahan	20	300
Gunung Batu Besar	1	210
Basuang	10	218
Papaan	1	210
Rampa Manunggul	20	280

Catatan: ...
Sumber: Badan Pusat Statistik, Pendataan Potensi Desa (PODES), 2021

https://kotabarukab.bps.go.id

https://kotabarukab.bps.go.id

BAB II
PEMERINTAHAN

/pe.me.rin.ta.han/

organisasi atau wadah orang yang mempunyai kekuasaaan dan lembaga yang mengurus masalah kenegaraan dan kesejahteraan rakyat dan negara

#GOVERNMENT

https://kotabarukab.bps.go.id

ULASAN

Pada bab ini disajikan data mengenai pemerintahan di Kecamatan Sampanahan. Dari 10 desa di Kecamatan Sampanahan terdapat 73 RT dan 19 RW/ Dusun. Desa yang memiliki jumlah RT terbanyak yaitu Desa Sukamaju dengan jumlah RT sebanyak 13 RT dan RW sebanyak 3 RW. Sementara itu Desa Sepapah merupakan desa dengan jumlah RT dan RW paling sedikit yaitu sebanyak 2 RT dan 1 RW.

https://kotabarukab.bps.go.id

Tabel 2.1 Jumlah Rukun Warga (RW)/Dusun dan Rukun Tetangga (RT) Menurut Desa/Kelurahan di Kecamatan Sampanahan, 2023

Desa/Kelurahan	Rukun Warga (RW)/Dusun	Rukun Tetangga (RT)
(1)	(2)	(3)
Sepapah	1	2
Banjarsari	3	11
Sungai Betung	1	4
Sampanahan Hilir	3	9
Sukamaju	3	13
Sampanahan	2	11
Gunung Batu Besar	2	6
Basuang	2	7
Papaan	1	4
Rampa Manunggul	1	6
Kecamatan Sampanahan	**19**	**73**

Catatan: ...
Sumber: Kantor Kecamatan Sampanahan

https://kotabarukab.bps.go.id

BAB III
PENDUDUK

/pen.du.duk/

semua orang yang berdomisili di wilayah geografis Republik Indonesia selama 6 bulan atau lebih dan atau mereka yang berdomisili kurang dari 6 bulan tetapi bertujuan untuk menetap

#POPULATION

Salinan Elektronik BPS Kabupaten Kepulauan Seribu
https://kepulauanseribukab.bps.go.id

https://kotabarukab.bps.go.id

ULASAN

Pada bab ini disajikan data mengenai kependudukan di Kecamatan Sampanahan. Pada tahun 2023 jumlah penduduk Kecamatan Sampanahan berjumlah 11.157 jiwa, terdiri dari 5.869 jiwa penduduk laki-laki dan 5.288 jiwa penduduk perempuan. Jumlah ini menyebabkan rasio jenis kelamin di Kecamatan Sampanahan sebesar 110,99, yang artinya diantara 100 penduduk perempuan terdapat 110 hingga 111 penduduk laki-laki.

Berdasarkan karakteristik wilayahnya, 18,39 persen atau sebanyak 2.052 jiwa penduduk Kecamatan Sampanahan bertempat tinggal di Desa Sukamaju. Sementara itu dari tingkat kepadatan penduduk, Desa Sukamaju merupakan desa dengan tingkat kepadatan penduduk tertinggi yaitu sebesar 147,54 jiwa per km2.

https://kotabarukab.bps.go.id

Gambar 3.1 Jumlah Penduduk Menurut Desa/Kelurahan di Kecamatan Sampanahan, 2023

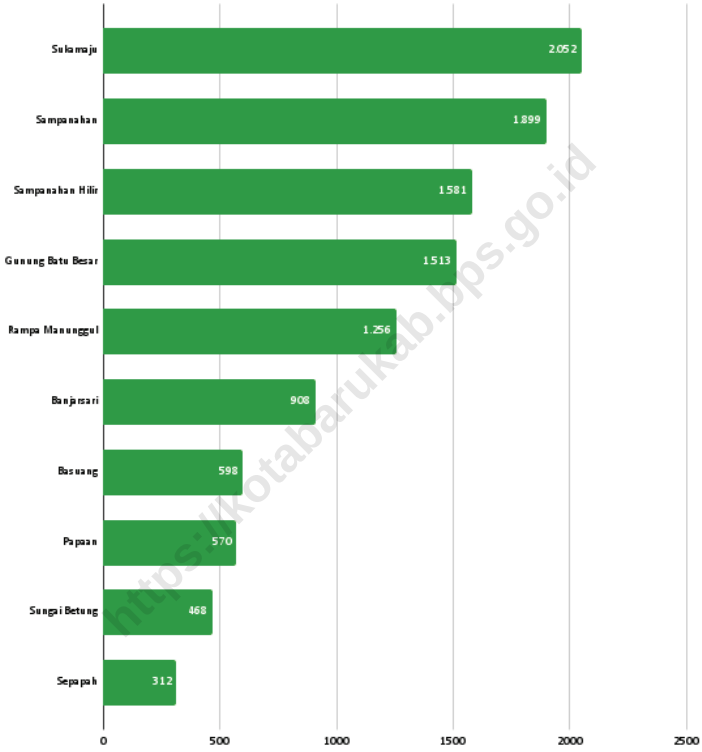

Sumber: Dinas Kependudukan dan Pencatatan Sipil Kabupaten Kotabaru

https://kotabarukab.bps.go.id

Tabel 3.1 Penduduk, Distribusi Persentase Penduduk, Kepadatan Penduduk, Rasio Jenis Kelamin Penduduk Menurut Desa/ Kelurahan di Kecamatan Sampanahan, 2023

Desa/Kelurahan	Penduduk		
	Laki-Laki	Perempuan	Jumlah
(1)	(2)	(3)	(4)
Sepapah	153	159	312
Banjarsari	477	431	908
Sungai Betung	253	215	468
Sampanahan Hilir	849	732	1.581
Sukamaju	1.064	988	2.052
Sampanahan	1.009	890	1.899
Gunung Batu Besar	788	725	1.513
Basuang	309	289	598
Papaan	280	290	570
Rampa Manunggul	687	569	1.256
Kecamatan Sampanahan	**5.869**	**5.288**	**11.157**

https://kotabarukab.bps.go.id

Lanjutan Tabel/*Continued Table* 3.1

Desa/Kelurahan	Persentase Penduduk	Kepadatan Penduduk (per km^2)	Rasio Jenis Kelamin Penduduk
(1)	(5)	(6)	(7)
Sepapah	2,8	6,99	96,23
Banjarsari	8,14	30,08	110,67
Sungai Betung	4,19	8,15	117,67
Sampanahan Hilir	14,17	43,23	115,98
Sukamaju	18,39	147,54	107,69
Sampanahan	17,02	36,21	113,37
Gunung Batu Besar	13,56	26,05	108,69
Basuang	5,36	19,37	106,92
Papaan	5,11	16,41	96,55
Rampa Manunggul	11,26	27,33	120,74
Kecamatan Sampanahan	**100,00**	**27,56**	**110,99**

Catatan: ...
Sumber: Dinas Kependudukan dan Pencatatan Sipil Kabupaten Kotabaru

https://kotabarukab.bps.go.id

BAB IV
SOSIAL DAN KESEJAHTERAAN RAKYAT

/so.si.al/

segala hal yang berkenaan dengan masyarakat

#SOCIAL & WALFARE

karuskab.bps.go.id

https://kotabarukab.bps.go.id

ULASAN

Pada bab ini disajikan data mengenai sosial dan kesejahteraan masyarakat yang ada di Kecamatan Sampanahan. Terdapat empat bagian yang dibahas mulai dari pendidikan, kesehatan, perumahan dan sosial, serta agama dan sosial lainnya.

Dari sisi pendidikan, di Kecamatan Sampanahan tersedia sekolah dari jenjang pendidikan taman kanak-kanak, sekolah dasar hingga sekolah menengah atas. Fasilitas pendidikan tersebut terdiri dari sekolah negeri maupun swasta yang tersebar di beberapa desa di Kecamatan Sampanahan. Dari sisi kesehatan, di Kecamatan Sampanahan pada tahun 2021 terdapat 2 puskesmas dengan rincian 1 puskesmas dengan rawat inap dan 1 puskesmas tanpa rawat inap. Dari sisi perumahan dan lingkungan yang salah satunya tercermin dari penggunaan fasilitas tempat buang air besar sebagian besar keluarga. Pada tahun 2021 terdapat sebanyak 9 desa/kelurahan yang menggunakan jamban milik sendiri dan 1 desa/kelurahan yang menggunakan bukan jamban.

https://kotabarukab.bps.go.id

4.1 PENDIDIKAN

Tabel 4.1.1 Banyaknya Desa[1]/Kelurahan yang Memiliki Fasilitas Sekolah Menurut Tingkat Pendidikan di Kecamatan Sampanahan, 2021–2023

Tingkat Pendidikan	2021[2]	2022[3]	2023[3]
(1)	(2)	(3)	(4)
Sekolah Dasar (SD)	8	8	8
Madrasah Ibtidaiyah (MI)	1	-	-
Sekolah Menengah Pertama (SMP)	2	2	2
Madrasah Tsanawiyah (MTs)	2	2	2
Sekolah Menengah Atas (SMA)	1	1	1
Sekolah Menengah Kejuruan (SMK)	-	-	-
Madrasah Aliyah (MA)	-	-	-
Akademi/Perguruan Tinggi	-	-	-

https://kotabarukab.bps.go.id

Catatan: [1] Desa pada tabel ini termasuk Unit Permukiman Transmigrasi (UPT) yang masih dibina oleh kementerian terkait
Sumber: [2] Badan Pusat Statistik, Pendataan Potensi Desa (Podes)
[3] Dinas Pendidikan Kabupaten Kotabaru dan Kementerian Agama Kabupaten Kotabaru

Tabel 4.1.2 Jumlah Sekolah Menurut Tingkat Pendidikan di Kecamatan Sampanahan, 2022/2023 dan 2023/2024

Tingkat Pendidikan	Negeri		Swasta		Jumlah	
	2022/2023	2023/2024	2022/2023	2023/2024	2022/2023	2023/2024
(1)	(2)	(3)	(4)	(5)	(6)	(7)
Taman Kanak-Kanak (TK)[1]	1	1	5	5	6	6
Raudatul Athfal (RA)[2]	-	-	-	1	-	1
Sekolah Dasar (SD)[1]	9	9	1	1	10	10
Madrasah Ibtidaiyah (MI)[2]	-	-	-	1	-	1
Sekolah Menengah Pertama (SMP)[1]	2	2	-	-	2	2
Madrasah Tsanawiyah (MTs)[2]	-	-	2	2	2	2
Sekolah Menengah Atas (SMA)[1]	1	1	-	-	1	1
Sekolah Menengah Kejuruan (SMK)[1]	-	-	-	-	-	-
Madrasah Aliyah (MA)[2]	-	-	-	-	-	-

Catatan: [3] Seluruh Raudatul Athfal (RA) berstatus swasta

Sumber: [1] Kementerian Pendidikan, Kebudayaan, Riset, dan Teknologi, Sistem Data Pokok Pendidikan (2022/2023) dan Dinas Pendidikan Kabupaten Kotaabru (2023/2024), data semester genap

[2] Kementerian Agama, EMIS, data semester genap

https://kotabarukab.bps.go.id

Tabel 4.1.3 Jumlah Guru Menurut Tingkat Pendidikan di Kecamatan Sampanahan, 2022/2023 dan 2023/2024

Tingkat Pendidikan	Negeri		Swasta		Jumlah	
	2022/2023	2023/2024	2022/2023	2023/2024	2022/2023	2023/2024
(1)	(2)	(3)	(4)	(5)	(6)	(7)
Taman Kanak-Kanak (TK)[1]	5	5	17	21	22	26
Raudatul Athfal (RA)[2]	-	-	4	3	4	3
Sekolah Dasar (SD)[1,3]	100	109	7	9	107	118
Madrasah Ibtidaiyah (MI)[2]	-	-	-	7	-	7
Sekolah Menengah Pertama (SMP)[1,3]	25	30	-	-	25	30
Madrasah Tsanawiyah (MTs)[2]	-	-	28	34	28	34
Sekolah Menengah Atas (SMA)[1,3]	27	27	-	-	27	27
Sekolah Menengah Kejuruan (SMK)[1,3]	-	-	-	-	-	-
Madrasah Aliyah (MA)[2]	-	-	-	-	-	-

Catatan: [3] Jumlah guru termasuk kepala sekolah dan guru

Sumber: [1] Kementerian Pendidikan, Kebudayaan, Riset, dan Teknologi, Sistem Data Pokok Pendidikan (2022/2023) dan Dinas Pendidikan Kabupaten Kotaabru (2023/2024), data semester genap

[2] Kementerian Agama, EMIS, data semester genap

https://kotabarukab.bps.go.id

Tabel 4.1.4 Jumlah Murid Menurut Tingkat Pendidikan di Kecamatan Sampanahan, 2022/2023 dan 2023/2024

Tingkat Pendidikan	Negeri		Swasta		Jumlah	
	2022/2023	2023/2024	2022/2023	2023/2024	2022/2023	2023/2024
(1)	(2)	(3)	(4)	(5)	(6)	(7)
Taman Kanak-Kanak (TK)[1]	50	54	187	204	237	258
Raudatul Athfal (RA)[2]	-	-	43	24	43	24
Sekolah Dasar (SD)[1]	1.067	1.035	72	80	1.139	1.115
Madrasah Ibtidaiyah (MI)[2]	-	-	-	50	-	50
Sekolah Menengah Pertama (SMP)[1]	298	285	-	-	298	285
Madrasah Tsanawiyah (MTs)[2]	-	-	279	291	279	291
Sekolah Menengah Atas (SMA)[1]	381	345	-	-	381	345
Sekolah Menengah Kejuruan (SMK)[1]	-	-	-	-	-	-
Madrasah Aliyah (MA)[2]	-	-	-	-	-	-

Catatan: ...

Sumber: [1] Kementerian Pendidikan, Kebudayaan, Riset, dan Teknologi, Sistem Data Pokok Pendidikan (2022/2023) dan Dinas Pendidikan Kabupaten Kotaabru (2023/2024), data semester genap
[2] Kementerian Agama, EMIS, data semester genap

https://kotabarukab.bps.go.id

4.2 KESEHATAN

Tabel 4.2.1 Banyaknya Desa[1]/Kelurahan yang Memiliki Sarana Kesehatan Menurut Jenis Sarana Kesehatan di Kecamatan Sampanahan, 2021-2023

Jenis Sarana Kesehatan	2021[2]	2022	2023
(1)	(2)	(3)	(4)
Rumah Sakit	-	...	...
Rumah Sakit Bersalin	-	...	...
Poliklinik/Balai Pengobatan	-	...	...
Puskesmas Rawat Inap	1	...	...
Puskesmas Tanpa Rawat Inap	1	...	...
Apotek	-	...	...

Catatan: [1] Desa pada tabel ini termasuk Unit Permukiman Transmigrasi (UPT) yang masih dibina oleh kementerian terkait

Sumber: [2] Badan Pusat Statistik, Pendataan Potensi Desa (Podes)

https://kotabarukab.bps.go.id

4.3 PERUMAHAN DAN LINGKUNGAN

Tabel 4.3.1 Banyaknya Desa[1]/Kelurahan Menurut Sumber Air Minum Sebagian Besar Keluarga di Kecamatan Sampanahan, 2021–2023

Sumber Air Minum	2021[2]	2022	2023
(1)	(2)	(3)	(4)
Air Kemasan Bermerk	-	...	...
Air Isi Ulang	3	...	...
Leding Dengan Meteran	-	...	...
Leding Tanpa Meteran	1	...	...
Sumur Bor atau Pompa	-	...	...
Sumur	-	...	...
Mata Air	2	...	...
Sungai/Danau/Kolam/ Waduk/Situ/ Embung/Bendungan	3	...	...
Air Hujan	1	...	...
Lainnya	-	...	...

Catatan: [1] Desa pada tabel ini termasuk Unit Permukiman Transmigrasi (UPT) yang masih dibina oleh kementerian terkait
Sumber: [2] Badan Pusat Statistik, Pendataan Potensi Desa (Podes)

https://kotabarukab.bps.go.id

Tabel 4.3.2 Banyaknya Desa[1]/Kelurahan Menurut Sumber Penerangan Jalan Utama Desa/Kelurahan di Kecamatan Sampanahan, 2021–2023

Sumber Penerangan Jalan Utama	2021[2]	2022	2023
(1)	(2)	(3)	(4)
Listrik Pemerintah	4	...	...
Listrik Non-Pemerintah	2	...	...
Non Listrik	-	...	...

Catatan: [1] Desa pada tabel ini termasuk Unit Permukiman Transmigrasi (UPT) yang masih dibina oleh kementerian terkait
Sumber: [2] Badan Pusat Statistik, Pendataan Potensi Desa (Podes)

https://kotabarukab.bps.go.id

Tabel 4.3.3 Banyaknya Desa[1]/Kelurahan Menurut Penggunaan Fasilitas Tempat Buang Air Besar Sebagian Besar Keluarga di Kecamatan Sampanahan, 2021–2023

Fasilitas Tempat Buang Air Besar	2021[2]	2022	2023
(1)	(2)	(3)	(4)
Jamban	9	...	...
Sendiri	9	...	...
Bersama	-	...	...
Umum	-	...	...
Bukan Jamban	1	...	...
Jumlah	**10**	**...**	**...**

Catatan: [1] Desa pada tabel ini termasuk Unit Permukiman Transmigrasi (UPT) yang masih dibina oleh kementerian terkait
Sumber: [2] Badan Pusat Statistik, Pendataan Potensi Desa (Podes)

https://kotabarukab.bps.go.id

4.4 AGAMA DAN SOSIAL LAINNYA

Tabel 4.4.1 Jumlah Tempat Peribadatan Menurut Desa/Kelurahan di Kecamatan Sampanahan, 2023

Desa/Kelurahan	Masjid	Mushola	Gereja Protestan	Gereja Katholik	Pura	Vihara
(1)	(2)	(3)	(4)	(5)	(6)	(7)
Sepapah	-	-	-	-	-	-
Banjarsari	1	5	-	-	-	-
Sungai Betung	1	-	-	-	-	-
Sampanahan Hilir	2	1	-	-	-	-
Sukamaju	1	10	-	-	-	-
Sampanahan	1	1	1	-	-	-
Gunung Batu Besar	1	1	-	-	-	-
Basuang	1	2	-	-	-	-
Papaan	-	1	-	-	-	-
Rampa Manunggul	1	-	-	-	-	-
Kecamatan Sampanahan	**9**	**21**	**1**	**-**	**-**	**-**

https://kotabarukab.bps.go.id

Catatan: ...
Sumber: Kementerian Agama Kabupaten Kotabaru

Tabel 4.4.2 Jumlah Penduduk Menurut Desa/Kelurahan dan Agama yang Dianut di Kecamatan Sampanahan, 2023

Desa/Kelurahan	Islam	Protestan	Katolik	Hindu	Budha	Lainnya
(1)	(2)	(3)	(4)	(5)	(6)	(7)
Sepapah	208	70	-	1	19	14
Banjarsari	868	35	5	-	-	-
Sungai Betung	466	-	-	-	-	2
Sampanahan Hilir	1.570	9	2	-	-	-
Sukamaju	2.043	8	1	-	-	-
Sampanahan	1.831	40	24	-	-	4
Gunung Batu Besar	1.510	3	-	-	-	-
Basuang	598	-	-	-	-	-
Papaan	565	5	-	-	-	-
Rampa Manunggul	1.227	3	26	-	-	-
Kecamatan Sampanahan	**10.886**	**173**	**58**	**1**	**19**	**20**

https://kotabarukab.bps.go.id

Catatan: ...
Sumber: Dinas Kependudukan dan Pencatatan Sipil Kabupaten Kotabaru

https://kotabarukab.bps.go.id

BAB V
PERTANIAN

/per.ta.ni.an/

pertanian mencakup usaha di subsektor tanaman pangan, hortikultura, perkebunan, peternakan, perikanan, kehutanan, serta usaha jasa pertanian

#AGRICULTURE

https://kotabaratkab.bps.go.id

https://kotabarukab.bps.go.id

ULASAN

Bab ini menyajikan data pertanian khususnya tanaman hortikultura semusim dan tahunan, tanaman biofarmaka, serta tanaman hias di Kecamatan Sampanahan. Pada tanaman hortikultura semusim luas panen terluas pada tahun 2023 adalah petsai/sawi yaitu 7 ha dengan nilai produksi 95 kuintal. Pada tanaman biofarmaka, komoditas laos/lengkuas merupakan komoditas dengan luas panen terbesar pada tahun 2023 yaitu 824 m2 dan produksi 297 kg. Pada tanaman hias, komoditas mawar merupakan komoditas dengan luas panen terbesar yaitu 50 m2 dan produksi 50 tangkai. Sementara itu, pada tanaman hortikultura tahunan, mangga merupakan komoditas dengan produksi terbesar pada tahun 2023 yaitu 428 kuintal.

https://kotabarukab.bps.go.id

Tabel 5.1 Luas Panen Tanaman Sayuran dan Buah-buahan Semusim Menurut Jenis Tanaman di Kecamatan Sampanahan (ha), 2020–2023

Jenis Tanaman	2020	2021	2022	2023
(1)	(2)	(3)	(4)	(5)
Sayuran:				
Bawang Merah	-	-	-	-
Cabai Besar/TW/Teropong	-	-	-	3
Cabai Keiting	-	-	-	-
Cabai Rawit	2	4	4	3
Kentang	-	-	-	-
Kubis	-	-	-	-
Tomat	2	1	1	-
Bawang Putih	-	-	-	-
Petsai/Sawi	5	10	7	7
Kacang Panjang	7	6	3	6
Buah–buahan:				
Melon	-	-	1	-
Semangka	7	1	1	2

Catatan: ...
Sumber: Badan Pusat Statistik, Statistik Pertanian Hortikultura SPH-SBS

https://kotabarukab.bps.go.id

Tabel 5.2 Produksi Tanaman Sayuran dan Buah-buahan Semusim Menurut Jenis Tanaman di Kecamatan Sampanahan (kuintal), 2020–2023

Jenis Tanaman	2020	2021	2022	2023
(1)	(2)	(3)	(4)	(5)
Sayuran:				
Bawang Merah	-	-	-	-
Cabai Besar/TW/Teropong	-	-	-	45
Cabai Keiting	-	-	-	-
Cabai Rawit	44	86	44	33
Kentang	-	-	-	-
Kubis	-	-	-	-
Tomat	75	20	8	-
Bawang Putih	-	-	-	-
Petsai/Sawi	245	360	230	95
Kacang Panjang	180	79	76	80,66
Buah–buahan:				
Melon	-	-	200	-
Semangka	2.067	320	200	155

Catatan: ...
Sumber: Badan Pusat Statistik, Statistik Pertanian Hortikultura SPH-SBS

https://kotabarukab.bps.go.id

Tabel 5.3 Luas Panen Tanaman Biofarmaka Menurut Jenis Tanaman di Kecamatan Sampanahan (m^2), 2020–2023

Jenis Tanaman	2020	2021	2022	2023
(1)	(2)	(3)	(4)	(5)
Jahe	-	-	2.205	52
Laos/Lengkuas	-	-	576	824
Kencur	-	-	356	500
Kunyit	-	-	1.275	-
Mahkota Dewa (Pohon)	-	-	90	-
Temulawak	-	-	97	-

Catatan: ...
Sumber: Badan Pusat Statistik, Statistik Pertanian Hortikultura SPH-TBF

https://kotabarukab.bps.go.id

Tabel 5.4 Produksi Tanaman Biofarmaka Menurut Jenis Tanaman di Kecamatan Sampanahan (kg), 2020–2023

Jenis Tanaman	2020	2021	2022	2023
(1)	(2)	(3)	(4)	(5)
Jahe	-	-	530	13
Laos/Lengkuas	-	-	1.104	297
Kencur	-	-	121	170
Kunyit	-	-	548	-
Mahkota Dewa	-	-	1.757	-
Temulawak	-	-	60	-

Catatan: ...
Sumber: Badan Pusat Statistik, Statistik Pertanian Hortikultura SPH-TBF

https://kotabarukab.bps.go.id

Tabel 5.5 Luas Panen Tanaman Hias Menurut Jenis Tanaman di Kecamatan Sampanahan (m^2), 2020–2023

Jenis Tanaman	2020	2021	2022	2023
(1)	(2)	(3)	(4)	(5)
Anggrek Pot	-	-	-	-
Anggrek Potong	-	-	-	-
Krisan	-	-	-	-
Mawar	-	-	-	50
Sedap Malam	-	-	-	-

Catatan: ...
Sumber: Badan Pusat Statistik, Statistik Pertanian Hortikultura SPH-TH

https://kotabarukab.bps.go.id

Tabel 5.6 Produksi Tanaman Hias Menurut Jenis Tanaman di Kecamatan Sampanahan (tangkai), 2020–2023

Jenis Tanaman	2020	2021	2022	2023
(1)	(2)	(3)	(4)	(5)
Anggrek Pot	-	-	-	-
Anggrek Potong	-	-	-	-
Krisan	-	-	-	-
Mawar	-	-	-	50
Sedap Malam	-	-	-	-

Catatan: ...
Sumber: Badan Pusat Statistik, Statistik Pertanian Hortikultura SPH-TH

https://kotabarukab.bps.go.id

Tabel 5.7 Produksi Buah-Buahan dan Sayuran Tahunan Menurut Jenis Tanaman di Kecamatan Sampanahan (kuintal), 2020–2023

Jenis Tanaman	2020	2021	2022	2023
(1)	(2)	(3)	(4)	(5)
Buah–Buahan:				
Mangga	-	270	633	270
Durian	604	451	523	428
Jeruk Siam/Keprok	40	15	4	6
Pisang	284	331	446	372
Pepaya	424	248	15	36
Salak	16	60	112	98
Nangka/Cempedak	632	265	165	163
Jambu Air	-	136	174	155
Sayuran:				
Petai	76	75	122	127

Catatan: ...
Sumber: Badan Pusat Statistik, Statistik Pertanian Hortikultura SPH-BST

https://kotabarukab.bps.go.id

DAFTAR PUSTAKA

Direktorat Jenderal Hortikultura & Badan Pusat Statistik. 2022. *Pedoman Statistik Pertanian Hortikultura (SPH)*. Jakarta: Kementerian Pertanian.

Direktorat Statistik Ketahanan Sosial. 2021. *Buku 3: Konsep dan Definisi Podes 2021*. Jakarta: Badan Pusat Statistik.

https://kotabarukab.bps.go.id

https://kotabarukab.bps.go.id

https://kotabarukab.bps.go.id

ST2023
SENSUS PERTANIAN

BerAKHLAK
Berorientasi Pelayanan Akuntabel Kompeten
Harmonis Loyal Adaptif Kolaboratif

#bangga melayani bangsa

DATA
MENCERDASKAN BANGSA

https://kotabarukab.bps.go.id

BADAN PUSAT STATISTIK
KABUPATEN KOTABARU
Jl. Jamrud I, Dirgahayu, Pulau Laut Utara, Kotabaru, 70242
Telp./Fax : (0518) 21145 Email : bps6302@bps.go.id
Website : kotabarukab.bps.go.id